MINISTERO DELLA DIFESA

meteomont Servizio Nazionale di previsione neve e valanghe

EAWS EUROPEAN AVALANCHE WARNING SERVICES

CARABINIERI

In collaborazione con: arpav

DOLOMITI SETTENTRIONALI

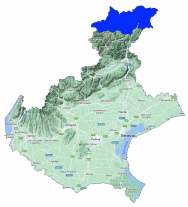

Bollettino Valanghe N. 336/2026 del 05/02/2026 ore 14.00
Validità 48 ore prossima emissione 06/02/2026

A cura del Servizio METEOMONT dell'ARMA dei CARABINIERI
In collaborazione con Servizio Meteorologico dell'Aeronautica militare

SITUAZIONE alle 14:00 del 05/02/2026

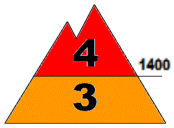

SITUAZIONE TIPO: neve a debole coesione e vento.

SITUAZIONE TIPO: neve a debole coesione e vento.

Quota neve (mslm)	Nord	Sud
	800 - 900	800 - 1100

Altezza Neve (cm)	Neve al suolo	Neve Fresca	Quota (mslm)
	85	17	2119
	78	25	1530

VALANGHE OSSERVATE: Numerose valanghe di medie dimensioni, Valanghe a lastroni di superficie.

PREVISIONI 06/02/2026

GRADO DI PERICOLO: FORTE 4

SITUAZIONE TIPO: neve a debole coesione e vento.



SITUAZIONE TIPO: pioggia su neve.

MANTO NEVOSO: La stabilità del manto nevoso è scarsa su molti punti (aree) per tutte le esposizioni al di sopra di 1400 mslm, possibili valanghe di dimensioni grandi.
La stabilità del manto nevoso è scarsa su molti punti (aree) per tutte le esposizioni al di sotto di 1400 mslm, possibili valanghe di dimensioni medie.

AVVERTENZE

Viste le condizioni del manto nevoso, le attività al di fuori delle piste battute e segnalate richiedono ottime capacità di valutazione del pericolo locale.

SCALA EUROPEA DEL GRADO DI PERICOLO VALANGHE

LEGENDA PROBLEMA

Bollettino realizzato su scala sinottica-regionale (standard EAWS). La sua valutazione non può escludere in alcun modo la necessità di una seria e capace valutazione locale del pericolo (singolo pendio) che può essere anche sensibilmente diverso. Le previsioni meteorologiche sono relative all'orario UTC (per l'Italia +1 in inverno e +2 in estate).

MINISTERO DELLA DIFESA

meteomont
Servizio Nazionale di previsione neve e valanghe

EAWS EUROPEAN AVALANCHE WARNING SERVICES

CARABINIERI

In collaborazione con: arpav

DOLOMITI SETTENTRIONALI

PREVISIONE METEO

Quota		06/02/2026 h6:00	06/02/2026 h12:00	06/02/2026 h18:00
1000	Venti	00 Calma	01 Nodi da Nord	01 Nodi da Nord
	Temperature	-02 °C	+01 °C	+00 °C
	Temp.percepita	-2 °C	1 °C	0 °C
2000	Venti	01 Nodi da Nord	03 Nodi da Nord	03 Nodi da Nord
	Temperature	-03 °C	+00 °C	-01 °C
	Temp.percepita	-3 °C	-2 °C	-3 °C
3000	Venti	05 Nodi da Ovest	05 Nodi da Nord	06 Nodi da Nord
	Temperature	-07 °C	-08 °C	-08 °C
	Temp.percepita	-11 °C	-13 °C	-13 °C
Zero termico		1300-1500 m.	1900-2100 m.	1600-1800 m.
Fenomeno		—	—	—
Stato del cielo				

LEGENDA FENOMENI

— Assenza Fenomeni · Nebbia · Foschia · Pioggia debole · Pioggia moderata · Pioggia forte · Temporali

Nevicata debole · Nevicata moderata · Nevicata forte

STATO DEL CIELO

Sereno · Poco nuvoloso · Nuvoloso · Molto nuvoloso · Coperto

Parametri meteonivometrici registrati presso i campi di rilevamento il 05/02/2026.

Località	Comune	Quota (m.s.l.m.)	Altezza neve (cm)	Neve caduta nelle 24 ore (cm)	Temp. Min (°C)	Temp. Max (°C)	Condizioni del tempo
MISURINA	Auronzo di Cadore (BL)	1759	72	21	-3	-1	Nevicata debole continua
MONTE AGUDO	Auronzo di Cadore (BL)	1530	78	25	-3	-1	Nevicata debole continua
MONTE FALORIA	Cortina d'Ampezzo (BL)	2119	85	17	-5	-1	Nevicata debole continua
COL DELLA TENDA	Comelico Superiore (BL)	1930	99	25	-2	0	Nevicata debole continua
COL PIOMBIN *	San Vito di Cadore (BL)	2263	102	N.P.	N.P.	N.P.	Assenza di precipitazioni

(*) Rilievi fuori campo

L'INFORMAZIONE E' PREVENZIONE - LEGGI L'ATTUALE GRADO DI PERICOLO VALANGHE!

IL CAPO DEL CENTRO NAZIONALE METEOMONT
(Ten. Col. RFI Emanuela Gini)
FIRMA AUTOGRAFA OMESSA AI SENSI
DELL'ART.3 DEL D.LGS N.39/1993

Bollettino realizzato su scala sinottica-regionale (standard EAWS). La sua valutazione non può escludere in alcun modo la necessità di una seria e capace valutazione locale del pericolo (singolo pendio) che può essere anche sensibilmente diverso. Le previsioni meteorologiche sono relative all'orario UTC (per l'Italia +1 in inverno e +2 in estate).