MINISTERO DELLA DIFESA

meteomont Servizio Nazionale di previsione neve e valanghe

EAWS EUROPEAN AVALANCHE WARNING SERVICES

CARABINIERI

In collaborazione con: arpav

PREALPI

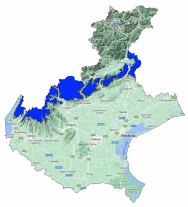

Bollettino Valanghe N. 334/2026 del 06/02/2026 ore 14.00
Validità 48 ore prossima emissione 07/02/2026

A cura del Servizio METEOMONT dell'ARMA dei CARABINIERI
In collaborazione con Servizio Meteorologico dell'Aeronautica militare

SITUAZIONE alle 14:00 del 06/02/2026

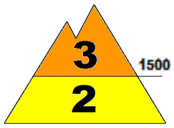

SITUAZIONE TIPO: neve a debole coesione e vento.



SITUAZIONE TIPO: pioggia su neve.

Quota neve (mslm)	Nord	Sud
	1000 - 1100	1000 - 1200

Altezza Neve (cm)	Neve al suolo	Neve Fresca	Quota (mslm)
	90	6	2100
	18	00	1025

VALANGHE OSSERVATE: Nessuna valanga.

PREVISIONI 07/02/2026

GRADO DI PERICOLO: MARCATO 3

SITUAZIONE TIPO: neve a debole coesione e vento.

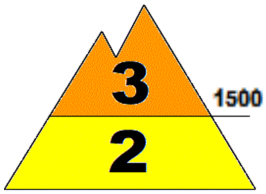



SITUAZIONE TIPO: pioggia su neve.

MANTO NEVOSO: La stabilità del manto nevoso è molto scarsa su molti punti (aree) per tutte le esposizioni al di sopra di 1500 mslm, possibili valanghe di dimensioni medie.
La stabilità del manto nevoso è scarsa su alcuni punti (aree) per tutte le esposizioni al di sotto di 1500 mslm, possibili valanghe di dimensioni medie.

AVVERTENZE

Viste le condizioni del manto nevoso, le attività al di fuori delle piste battute e segnalate richiedono ottime capacità di valutazione del pericolo locale.

SCALA EUROPEA DEL GRADO DI PERICOLO VALANGHE

LEGENDA PROBLEMA

Bollettino realizzato su scala sinottica-regionale (standard EAWS). La sua valutazione non può escludere in alcun modo la necessità di una seria e capace valutazione locale del pericolo (singolo pendio) che può essere anche sensibilmente diverso. Le previsioni meteorologiche sono relative all'orario UTC (per l'Italia +1 in inverno e +2 in estate).

MINISTERO DELLA DIFESA

meteomont
Servizio Nazionale di previsione neve e valanghe

EAWS EUROPEAN AVALANCHE WARNING SERVICES

CARABINIERI

In collaborazione con: arpav

PREALPI

PREVISIONE METEO

Quota		07/02/2026 h6:00	07/02/2026 h12:00	07/02/2026 h18:00
1000	Venti	01 Nodi da Est	01 Nodi da Ovest	01 Nodi da S-Ovest
	Temperature	+04 °C	+04 °C	+03 °C
	Temp.percepita	4 °C	4 °C	3 °C
2000	Venti	02 Nodi da N-Est	02 Nodi da N-Est	02 Nodi da Nord
	Temperature	-02 °C	-02 °C	-02 °C
	Temp.percepita	-2 °C	-2 °C	-2 °C
3000	Venti	02 Nodi da Nord	02 Nodi da N-Est	04 Nodi da N-Est
	Temperature	-08 °C	-09 °C	-08 °C
	Temp.percepita	-8 °C	-9 °C	-12 °C
Zero termico		1600-1800 m.	1500-1700 m.	1500-1700 m.
Fenomeno			—	—
Stato del cielo				

LEGENDA FENOMENI

— Assenza Fenomeni · Nebbia · Foschia · Pioggia debole · Pioggia moderata · Pioggia forte · Temporali

Nevicata debole · Nevicata moderata · Nevicata forte

STATO DEL CIELO

Sereno · Poco nuvoloso · Nuvoloso · Molto nuvoloso · Coperto

Parametri meteonivometrici registrati presso i campi di rilevamento il 06/02/2026.

Località	Comune	Quota (m.s.l.m.)	Altezza neve (cm)	Neve caduta nelle 24 ore (cm)	Temp. Min (°C)	Temp. Max (°C)	Condizioni del tempo
PIAN CANSIGLIO	Tambre (BL)	1025	18	0	0	+4	Pioggia debole intermittente
GALLIO - BUSA FONDA	Gallio (VI)	1460	95	6	+1	+7	Nevicata debole continua
MONTI LESSINI - MALGA SAN GIORGIO	Bosco Chiesanuova (VR)	1461	54	4	0	+6	Nevicata moderata
FILONE DELLA VAL BONA *	Chies d'Alpago (BL)	1887	228	N.P.	N.P.	N.P.	Assenza di precipitazioni
M.TE CORNETTO-SENGIO ALTO *	Vallarsa (TN)	1609	92	11	N.P.	N.P.	Nevicata debole continua

(*) Rilievi fuori campo

L'INFORMAZIONE E' PREVENZIONE - LEGGI L'ATTUALE GRADO DI PERICOLO VALANGHE!

IL CAPO DEL CENTRO NAZIONALE METEOMONT
(Ten. Col. RFI Emanuela Gini)
FIRMA AUTOGRAFA OMESSA AI SENSI
DELL'ART.3 DEL D.LGS N.39/1993

Bollettino realizzato su scala sinottica-regionale (standard EAWS). La sua valutazione non può escludere in alcun modo la necessità di una seria e capace valutazione locale del pericolo (singolo pendio) che può essere anche sensibilmente diverso. Le previsioni meteorologiche sono relative all'orario UTC (per l'Italia +1 in inverno e +2 in estate).