MINISTERO DELLA DIFESA

meteomont
Servizio Nazionale di previsione neve e valanghe

EAWS EUROPEAN AVALANCHE WARNING SERVICES

CARABINIERI

AERONAUTICA MILITARE SERVIZIO METEOROLOGICO

ALPI GRAIE

Bollettino Valanghe N. 337/2026 del 06/02/2026 ore 14.00
Validità 48 ore prossima emissione 07/02/2026

A cura del Servizio METEOMONT dell'ARMA dei CARABINIERI
In collaborazione con Servizio Meteorologico dell'Aeronautica militare

SITUAZIONE alle 14:00 del 06/02/2026

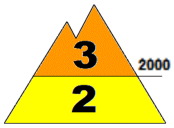

SITUAZIONE TIPO: neve a debole coesione e vento.



SITUAZIONE TIPO: nessuna situazione tipo evidente.

Quota neve (mslm)	Nord	Sud
	600	800

Altezza Neve (cm)	Neve al suolo	Neve Fresca	Quota (mslm)
	140	000	2304
	081	000	1581

VALANGHE OSSERVATE: Alcune valanghe di medie dimensioni, I due tipi di valanghe di neve di superficie.

PREVISIONI 07/02/2026

GRADO DI PERICOLO: MARCATO 3

SITUAZIONE TIPO: neve a debole coesione e vento.

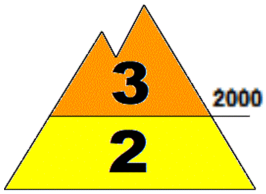

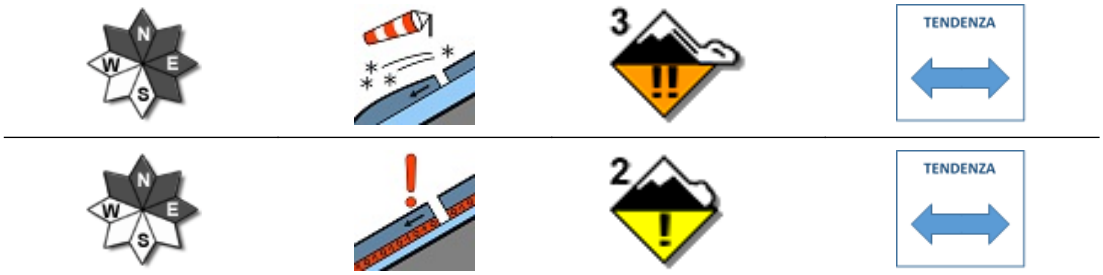

SITUAZIONE TIPO: nessuna situazione tipo evidente.

MANTO NEVOSO: La stabilità del manto nevoso è scarsa su molti punti (aree) per versanti da nord ovest a sud est compresi al di sopra di 2000 mslm, possibili valanghe di dimensioni medie.
La stabilità del manto nevoso è scarsa su alcuni punti (aree) per versanti in ombra al di sotto di 2000 mslm, possibili valanghe di dimensioni medie.

AVVERTENZE

A seguito dell'attività eolica registrata sono da evitare le zone di accumulo, conche, canaloni, cambi di pendenza e pendii sotto vento in genere.

SCALA EUROPEA DEL GRADO DI PERICOLO VALANGHE

LEGENDA PROBLEMA

Bollettino realizzato su scala sinottica-regionale (standard EAWS). La sua valutazione non può escludere in alcun modo la necessità di una seria e capace valutazione locale del pericolo (singolo pendio) che può essere anche sensibilmente diverso. Le previsioni meteorologiche sono relative all'orario UTC (per l'Italia +1 in inverno e +2 in estate).

MINISTERO DELLA DIFESA

meteomont
Servizio Nazionale di previsione neve e valanghe

EAWS EUROPEAN AVALANCHE WARNING SERVICES

CARABINIERI

ALPI GRAIE

PREVISIONE METEO

Quota		07/02/2026 h6:00	07/02/2026 h12:00	07/02/2026 h18:00
1000	Venti	02 Nodi da Ovest	01 Nodi da Est	01 Nodi da Sud
	Temperature	-02 °C	-01 °C	-01 °C
	Temp.percepita	-2 °C	-1 °C	-1 °C
2000	Venti	01 Nodi da S-Ovest	00 Calma	01 Nodi da S-Est
	Temperature	-01 °C	-02 °C	-02 °C
	Temp.percepita	-1 °C	-2 °C	-2 °C
3000	Venti	03 Nodi da Sud	02 Nodi da S-Est	01 Nodi da N-Est
	Temperature	-09 °C	-09 °C	-08 °C
	Temp.percepita	-12 °C	-9 °C	-8 °C
Zero termico		1400-1600 m.	1400-1600 m.	1400-1600 m.
Fenomeno		—		—
Stato del cielo				

LEGENDA FENOMENI

— Assenza Fenomeni · Nebbia · Foschia · Pioggia debole · Pioggia moderata · Pioggia forte · Temporali

Nevicata debole · Nevicata moderata · Nevicata forte

STATO DEL CIELO

Sereno · Poco nuvoloso · Nuvoloso · Molto nuvoloso · Coperto

Parametri meteonivometrici registrati presso i campi di rilevamento il 06/02/2026.

Località	Comune	Quota (m.s.l.m.)	Altezza neve (cm)	Neve caduta nelle 24 ore (cm)	Temp. Min (°C)	Temp. Max (°C)	Condizioni del tempo
CORNETTI	Balme (TO)	1410	104	12	N.P.	N.P.	Assenza di precipitazioni
PIAMPRATO	Valprato Soana (TO)	1550	88	0	-7	+23	Assenza di precipitazioni
PIAN DELLA FOUMA *	Usseglio (TO)	2100	130	15	N.P.	N.P.	Assenza di precipitazioni

(*) Rilievi fuori campo

L'INFORMAZIONE E' PREVENZIONE - LEGGI L'ATTUALE GRADO DI PERICOLO VALANGHE!

IL CAPO DEL CENTRO NAZIONALE METEOMONT
(Ten. Col. RFI Emanuela Gini)
FIRMA AUTOGRAFA OMESSA AI SENSI
DELL'ART.3 DEL D.LGS N.39/1993

Bollettino realizzato su scala sinottica-regionale (standard EAWS). La sua valutazione non può escludere in alcun modo la necessità di una seria e capace valutazione locale del pericolo (singolo pendio) che può essere anche sensibilmente diverso. Le previsioni meteorologiche sono relative all'orario UTC (per l'Italia +1 in inverno e +2 in estate).