MINISTERO DELLA DIFESA

meteomont
Servizio Nazionale di previsione neve e valanghe

EAWS EUROPEAN AVALANCHE WARNING SERVICES

CARABINIERI

GRAN SASSO EST - LAGA EST

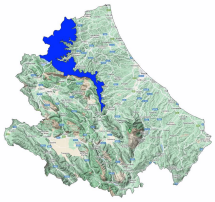

Bollettino Valanghe N. 326/2026 del 06/02/2026 ore 14.00
Validità 48 ore prossima emissione 07/02/2026

A cura del Servizio METEOMONT dell'ARMA dei CARABINIERI
In collaborazione con Servizio Meteorologico dell'Aeronautica militare

SITUAZIONE alle 14:00 del 06/02/2026

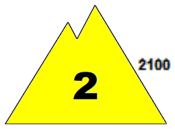

SITUAZIONE TIPO: neve a debole coesione e vento.



SITUAZIONE TIPO: pioggia su neve.

Quota neve (mslm)	Nord	Sud
	1400 - 1500	1500 - 1600

Altezza Neve (cm)	Neve al suolo	Neve Fresca	Quota (mslm)
	075	000	1896
	020	002	1380

VALANGHE OSSERVATE: Nessuna valanga.

PREVISIONI 07/02/2026

GRADO DI PERICOLO: MODERATO 2

SITUAZIONE TIPO: neve a debole coesione e vento.

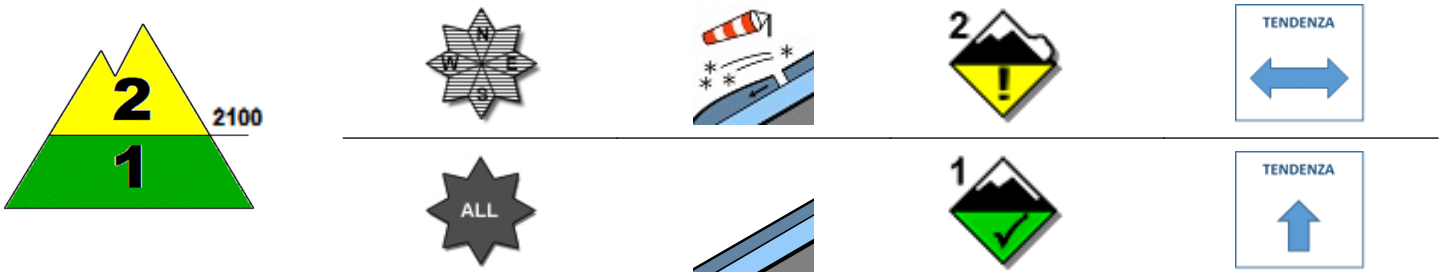

SITUAZIONE TIPO: nessuna situazione tipo evidente.

MANTO NEVOSO: La stabilità del manto nevoso è discreta su alcuni punti (aree) per isolati pendii al di sopra di 2100 mslm, possibili valanghe di dimensioni medie.
La stabilità del manto nevoso è discreta su alcuni punti (aree) per tutte le esposizioni al di sotto di 2100 mslm, possibili valanghe di dimensioni piccole.

AVVERTENZE

A seguito dell'attività eolica registrata sono da evitare le zone di accumulo, conche, canaloni, cambi di pendenza e pendii sotto vento in genere.

SCALA EUROPEA DEL GRADO DI PERICOLO VALANGHE

LEGENDA PROBLEMA

Bollettino realizzato su scala sinottica-regionale (standard EAWS). La sua valutazione non può escludere in alcun modo la necessità di una seria e capace valutazione locale del pericolo (singolo pendio) che può essere anche sensibilmente diverso. Le previsioni meteorologiche sono relative all'orario UTC (per l'Italia +1 in inverno e +2 in estate).

MINISTERO DELLA DIFESA

meteomont
Servizio Nazionale di previsione neve e valanghe

EAWS EUROPEAN AVALANCHE WARNING SERVICES

CARABINIERI

GRAN SASSO EST - LAGA EST

PREVISIONE METEO

Quota		07/02/2026 h6:00	07/02/2026 h12:00	07/02/2026 h18:00
1000	Venti	04 Nodi da S-Ovest	04 Nodi da S-Ovest	02 Nodi da Ovest
	Temperature	+01 °C	+03 °C	+00 °C
	Temp.percepita	-1 °C	1 °C	0 °C
2000	Venti	10 Nodi da S-Ovest	09 Nodi da S-Ovest	06 Nodi da Ovest
	Temperature	-02 °C	-01 °C	-02 °C
	Temp.percepita	-8 °C	-6 °C	-6 °C
3000	Venti	12 Nodi da Ovest	11 Nodi da S-Ovest	11 Nodi da S-Ovest
	Temperature	-07 °C	-08 °C	-07 °C
	Temp.percepita	-14 °C	-15 °C	-14 °C
Zero termico		1600-1800 m.	1700-1900 m.	1400-1600 m.
Fenomeno		—	—	
Stato del cielo				

LEGENDA FENOMENI

— Assenza Fenomeni · Nebbia · Foschia · Pioggia debole · Pioggia moderata · Pioggia forte · Temporali

Nevicata debole · Nevicata moderata · Nevicata forte

STATO DEL CIELO

Sereno · Poco nuvoloso · Nuvoloso · Molto nuvoloso · Coperto

Parametri meteonivometrici registrati presso i campi di rilevamento il 06/02/2026.

Località	Comune	Quota (m.s.l.m.)	Altezza neve (cm)	Neve caduta nelle 24 ore (cm)	Temp. Min (°C)	Temp. Max (°C)	Condizioni del tempo
FAVACCHIOLE	Crognaleto (TE)	1016	0	0	+1	+7	Pioggia debole intermittente
PRATO SELVA	Fano Adriano (TE)	1355	0	0	+0	+6	Pioggia debole continua
RIGOPIANO	Farindola (PE)	1135	0	0	+2	+9	Pioggia debole continua
PIANO SAN PIETRO	Isola del Gran Sasso d'Italia (TE)	950	0	0	N.P.	N.P.	Pioggia debole intermittente
PRATI DI TIVO	Pietracamela (TE)	1380	20	2	+1	+8	Pioggia debole intermittente
CEPPO	Rocca Santa Maria (TE)	1349	2	2 cm di neve fresca mista a pioggia	+2	+8	Assenza di precipitazioni
SAN PAOLO	Acquasanta Terme (AP)	960	0	0	+1	+11	Pioggia debole intermittente
COLLE SAN GIACOMO	Civitella del Tronto (TE)	1075	0	N.P.	+1	+8	Assenza di precipitazioni
PRATI DI TIVO - ARAPIETRA *	Pietracamela (TE)	1896	75	0	N.P.	N.P.	Scaccianeve (tormenta) sulla stazione

(*) Rilievi fuori campo

L'INFORMAZIONE E' PREVENZIONE - LEGGI L'ATTUALE GRADO DI PERICOLO VALANGHE!

IL CAPO DEL CENTRO NAZIONALE METEOMONT
(Ten. Col. RFI Emanuela Gini)
FIRMA AUTOGRAFA OMESSA AI SENSI
DELL'ART.3 DEL D.LGS N.39/1993

Bollettino realizzato su scala sinottica-regionale (standard EAWS). La sua valutazione non può escludere in alcun modo la necessità di una seria e capace valutazione locale del pericolo (singolo pendio) che può essere anche sensibilmente diverso. Le previsioni meteorologiche sono relative all'orario UTC (per l'Italia +1 in inverno e +2 in estate).