MINISTERO DELLA DIFESA

meteomont
Servizio Nazionale di previsione neve e valanghe

EAWS EUROPEAN AVALANCHE WARNING SERVICES

CARABINIERI

GRAN SASSO OVEST

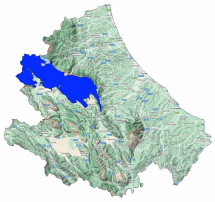

Bollettino Valanghe N. 326/2026 del 05/02/2026 ore 14.00
Validità 48 ore prossima emissione 06/02/2026

A cura del Servizio METEOMONT dell'ARMA dei CARABINIERI
In collaborazione con Servizio Meteorologico dell'Aeronautica militare

SITUAZIONE alle 14:00 del 05/02/2026

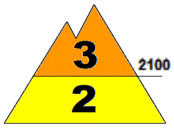

SITUAZIONE TIPO: freddo su caldo / caldo su freddo.

SITUAZIONE TIPO: situazione primaverile.

Quota neve (mslm)	Nord	Sud
	1500 - 1600	1700 - 1800

Altezza Neve (cm)	Neve al suolo	Neve Fresca	Quota (mslm)
	315	010	2215
	102	004	2135

VALANGHE OSSERVATE: Alcune valanghe di medie dimensioni, Valanghe a lastroni di superficie.

PREVISIONI 06/02/2026

GRADO DI PERICOLO: MODERATO 2

SITUAZIONE TIPO: neve a debole coesione e vento.

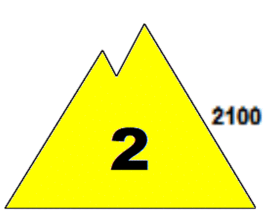



SITUAZIONE TIPO: situazione primaverile.

MANTO NEVOSO: La stabilità del manto nevoso è scarsa su alcuni punti (aree) per versanti da nord ovest a sud est compresi al di sopra di 2100 mslm, possibili valanghe di dimensioni medie.
La stabilità del manto nevoso è discreta su alcuni punti (aree) per tutte le esposizioni al di sotto di 2100 mslm, possibili valanghe di dimensioni medie.

AVVERTENZE

Il previsto rialzo termico potrebbe causare il distacco di cornici con conseguente sovraccarico dei pendii sottostanti.

SCALA EUROPEA DEL GRADO DI PERICOLO VALANGHE

LEGENDA PROBLEMA

Bollettino realizzato su scala sinottica-regionale (standard EAWS). La sua valutazione non può escludere in alcun modo la necessità di una seria e capace valutazione locale del pericolo (singolo pendio) che può essere anche sensibilmente diverso. Le previsioni meteorologiche sono relative all'orario UTC (per l'Italia +1 in inverno e +2 in estate).

MINISTERO DELLA DIFESA

meteomont
Servizio Nazionale di previsione neve e valanghe

EAWS EUROPEAN AVALANCHE WARNING SERVICES

CARABINIERI

GRAN SASSO OVEST

PREVISIONE METEO

Quota		06/02/2026 h6:00	06/02/2026 h12:00	06/02/2026 h18:00
1000	Venti	09 Nodi da Ovest	10 Nodi da Ovest	08 Nodi da Ovest
	Temperature	+04 °C	+02 °C	+02 °C
	Temp.percepita	0 °C	-2 °C	-2 °C
2000	Venti	23 Nodi da Ovest	23 nodi da Ovest	18 nodi da Ovest
	Temperature	+01 °C	-01 °C	-01 °C
	Temp.percepita	-6 °C	-9 °C	-8 °C
3000	Venti	25 Nodi da Ovest	29 nodi da Ovest	21 nodi da Ovest
	Temperature	-06 °C	-06 °C	-05 °C
	Temp.percepita	-16 °C	-17 °C	-14 °C
Zero termico		2000-2200 m.	1700-1900 m.	1700-1900 m.
Fenomeno			—	—
Stato del cielo				

LEGENDA FENOMENI

— Assenza Fenomeni · Nebbia · Foschia · Pioggia debole · Pioggia moderata · Pioggia forte · Temporali

Nevicata debole · Nevicata moderata · Nevicata forte

STATO DEL CIELO

Sereno · Poco nuvoloso · Nuvoloso · Molto nuvoloso · Coperto

Parametri meteonivometrici registrati presso i campi di rilevamento il 05/02/2026.

Località	Comune	Quota (m.s.l.m.)	Altezza neve (cm)	Neve caduta nelle 24 ore (cm)	Temp. Min (°C)	Temp. Max (°C)	Condizioni del tempo
COLLE RUTO	Campotosto (AQ)	1384	0	0	-3	+3	Assenza di precipitazioni
S. DONATO	Castel del Monte (AQ)	1400	0	0	0	+8	Assenza di precipitazioni
CAMPO IMPERATORE	L'Aquila (AQ)	2135	102	4	-3	0	Nevicata debole intermittente
MONTE AQUILA (SELLA) *	L'Aquila (AQ)	2215	315	10	N.P.	N.P.	Nevicata debole intermittente

(*) Rilievi fuori campo

L'INFORMAZIONE E' PREVENZIONE - LEGGI L'ATTUALE GRADO DI PERICOLO VALANGHE!

IL CAPO DEL CENTRO NAZIONALE METEOMONT
(Ten. Col. RFI Emanuela Gini)
FIRMA AUTOGRAFA OMESSA AI SENSI
DELL'ART.3 DEL D.LGS N.39/1993

Bollettino realizzato su scala sinottica-regionale (standard EAWS). La sua valutazione non può escludere in alcun modo la necessità di una seria e capace valutazione locale del pericolo (singolo pendio) che può essere anche sensibilmente diverso. Le previsioni meteorologiche sono relative all'orario UTC (per l'Italia +1 in inverno e +2 in estate).