# VELINO - SIRENTE

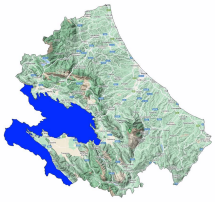

Bollettino Valanghe N. 310/2026 del 06/02/2026 ore 14.00
Validità 48 ore prossima emissione 07/02/2026

**A cura del Servizio METEOMONT dell'ARMA dei CARABINIERI**
**In collaborazione con Servizio Meteorologico dell'Aeronautica militare**

## SITUAZIONE alle 14:00 del 06/02/2026

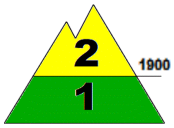


**SITUAZIONE TIPO: neve a debole coesione e vento.**

**SITUAZIONE TIPO: pioggia su neve.**

| Quota neve (mslm) | Nord | Sud |
|---|---|---|
| | 1500 - 1600 | 1500 - 1700 |

| Altezza Neve (cm) | Neve al suolo | Neve Fresca | Quota (mslm) |
|---|---|---|---|
| | 070 | 010 | 1850 |
| | 002 | 000 | 1573 |

**VALANGHE OSSERVATE: Nessuna valanga.**

## PREVISIONI 07/02/2026

## GRADO DI PERICOLO: MODERATO 2

## SITUAZIONE TIPO: neve pallottolare sepolta.



**MANTO NEVOSO: La stabilità del manto nevoso è discreta su alcuni punti (aree) per tutte le esposizioni, possibili valanghe di dimensioni medie.**

## AVVERTENZE

In considerazione delle avverse condizioni meteorologiche previste, e della scarsa visibilità, risulterà difficoltosa l'individuazione dell'itinerario e della valutazione del singolo pendio.

## SCALA EUROPEA DEL GRADO DI PERICOLO VALANGHE

## LEGENDA PROBLEMA

**Bollettino realizzato su scala sinottica-regionale (standard EAWS). La sua valutazione non può escludere in alcun modo la necessità di una seria e capace valutazione locale del pericolo (singolo pendio) che può essere anche sensibilmente diverso. Le previsioni meteorologiche sono relative all'orario UTC (per l'Italia +1 in inverno e +2 in estate).**

MINISTERO DELLA DIFESA

meteomont
Servizio Nazionale di previsione neve e valanghe

EAWS EUROPEAN AVALANCHE WARNING SERVICES

CARABINIERI

# VELINO - SIRENTE

## PREVISIONE METEO

| Quota | | 07/02/2026 h6:00 | 07/02/2026 h12:00 | 07/02/2026 h18:00 |
|---|---|---|---|---|
| 1000 | Venti | 07 Nodi da S-Ovest | 07 Nodi da S-Ovest | 03 Nodi da S-Ovest |
| | Temperature | -01 °C | -01 °C | -01 °C |
| | Temp.percepita | -5 °C | -5 °C | -3 °C |
| 2000 | Venti | 11 Nodi da S-Ovest | 10 Nodi da S-Ovest | 05 Nodi da S-Ovest |
| | Temperature | -02 °C | -02 °C | -01 °C |
| | Temp.percepita | -8 °C | -8 °C | -4 °C |
| 3000 | Venti | 13 Nodi da Ovest | 14 Nodi da S-Ovest | 14 Nodi da Ovest |
| | Temperature | -07 °C | -08 °C | -08 °C |
| | Temp.percepita | -15 °C | -16 °C | -16 °C |
| Zero termico | | 1600-1800 m. | 1700-1900 m. | 1700-1900 m. |
| Fenomeno | | | | |
| Stato del cielo | | | | |

## LEGENDA FENOMENI

Assenza Fenomeni · Nebbia · Foschia · Pioggia debole · Pioggia moderata · Pioggia forte · Temporali

Nevicata debole · Nevicata moderata · Nevicata forte

## STATO DEL CIELO

Sereno · Poco nuvoloso · Nuvoloso · Molto nuvoloso · Coperto

## Parametri meteonivometrici registrati presso i campi di rilevamento il 06/02/2026.

| Località | Comune | Quota (m.s.l.m.) | Altezza neve (cm) | Neve caduta nelle 24 ore (cm) | Temp. Min (°C) | Temp. Max (°C) | Condizioni del tempo |
|---|---|---|---|---|---|---|---|
| PASSO LE FORCHE | Magliano de' Marsi (AQ) | 1276 | 0 | 0 | +2 | +11 | Pioggia debole intermittente |
| SANT'ELIA * | Collelongo (AQ) | 1470 | 10 | N.P. | N.P. | N.P. | Pioggia debole intermittente |
| MARSIA | Tagliacozzo (AQ) | 1450 | 7 | 0 | +1 | +6 | Pioggia debole continua |
| LA CROCETTA | Lucoli (AQ) | 1573 | 2 | 0 | -1 | +4 | Pioggia debole intermittente |
| ARRIVO IMPIANTI OVINDOLI * | Ovindoli (AQ) | 1850 | 70 | 10 | N.P. | N.P. | Temporale con grandine o neve granulosa |

(*) Rilievi fuori campo

**L'INFORMAZIONE E' PREVENZIONE - LEGGI L'ATTUALE GRADO DI PERICOLO VALANGHE!**

IL CAPO DEL CENTRO NAZIONALE METEOMONT
(Ten. Col. RFI Emanuela Gini)
FIRMA AUTOGRAFA OMESSA AI SENSI
DELL'ART.3 DEL D.LGS N.39/1993

Bollettino realizzato su scala sinottica-regionale (standard EAWS). La sua valutazione non può escludere in alcun modo la necessità di una seria e capace valutazione locale del pericolo (singolo pendio) che può essere anche sensibilmente diverso. Le previsioni meteorologiche sono relative all'orario UTC (per l'Italia +1 in inverno e +2 in estate).