TERMINILLO MONTI REATINI E LAGA OVEST

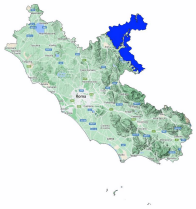

Bollettino Valanghe N. 279/2026 del 06/02/2026 ore 14.00
Validità 48 ore prossima emissione 07/02/2026

A cura del Servizio METEOMONT dell'ARMA dei CARABINIERI
In collaborazione con Servizio Meteorologico dell'Aeronautica militare

SITUAZIONE alle 14:00 del 06/02/2026

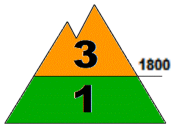

SITUAZIONE TIPO: neve a debole coesione e vento.

SITUAZIONE TIPO: pioggia su neve.

Quota neve (mslm)	Nord	Sud
	1400 - 1500	1600 - 1700

Altezza Neve (cm)	Neve al suolo	Neve Fresca	Quota (mslm)
	043	000	1825
	010	003	1350

VALANGHE OSSERVATE: Nessuna valanga.

PREVISIONI 07/02/2026

GRADO DI PERICOLO: MODERATO 2

SITUAZIONE TIPO: neve a debole coesione e vento.

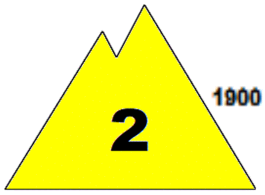

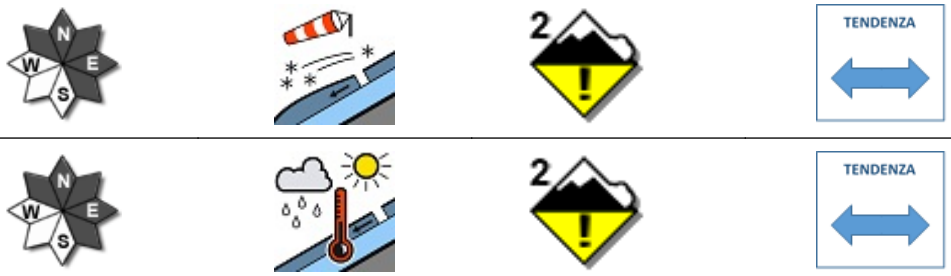

SITUAZIONE TIPO: pioggia su neve.

MANTO NEVOSO: La stabilità del manto nevoso è scarsa su alcuni punti (aree) per versanti da nord ovest a sud est compresi al di sopra di 1900 mslm, possibili valanghe di dimensioni medie.
La stabilità del manto nevoso è scarsa su pochi punti (aree) per versanti da nord ovest a sud est compresi al di sotto di 1900 mslm, possibili valanghe di dimensioni medie.

AVVERTENZE

In considerazione delle avverse condizioni meteorologiche previste, e della scarsa visibilità, risulterà difficoltosa l'individuazione dell'itinerario e della valutazione del singolo pendio.

SCALA EUROPEA DEL GRADO DI PERICOLO VALANGHE

5 - MOLTO FORTE | 4 - FORTE | 3 - MARCATO | 2 - MODERATO | 1 - DEBOLE | NO NEVE | NO INFO

LEGENDA PROBLEMA

NEVE FRESCA | LASTRONI DA VENTO | STRATI DEBOLI PERSISTENTI | NEVE BAGNATA | SLITTAMENTO | CORNICI | NESSUN PROBLEMA VALANGHIVO EVIDENTE | NO_INFO

Bollettino realizzato su scala sinottica-regionale (standard EAWS). La sua valutazione non può escludere in alcun modo la necessità di una seria e capace valutazione locale del pericolo (singolo pendio) che può essere anche sensibilmente diverso. Le previsioni meteorologiche sono relative all'orario UTC (per l'Italia +1 in inverno e +2 in estate).

MINISTERO DELLA DIFESA

meteomont
Servizio Nazionale di previsione neve e valanghe

EAWS EUROPEAN AVALANCHE WARNING SERVICES

CARABINIERI

TERMINILLO MONTI REATINI E LAGA OVEST

PREVISIONE METEO

Quota		07/02/2026 h6:00	07/02/2026 h12:00	07/02/2026 h18:00
1000	Venti	05 Nodi da S-Ovest	04 Nodi da S-Ovest	04 Nodi da S-Ovest
	Temperature	+02 °C	+02 °C	+02 °C
	Temp.percepita	-1 °C	-0 °C	-0 °C
2000	Venti	11 Nodi da S-Ovest	11 Nodi da S-Ovest	10 Nodi da S-Ovest
	Temperature	-01 °C	-01 °C	-02 °C
	Temp.percepita	-7 °C	-7 °C	-8 °C
3000	Venti	10 Nodi da Ovest	11 Nodi da S-Ovest	14 Nodi da Ovest
	Temperature	-07 °C	-07 °C	-08 °C
	Temp.percepita	-14 °C	-14 °C	-16 °C
Zero termico		1700-1900 m.	1700-1900 m.	1700-1900 m.
Fenomeno		—	—	
Stato del cielo				

LEGENDA FENOMENI

— Assenza Fenomeni · Nebbia · Foschia · Pioggia debole · Pioggia moderata · Pioggia forte · Temporali

Nevicata debole · Nevicata moderata · Nevicata forte

STATO DEL CIELO

Sereno · Poco nuvoloso · Nuvoloso · Molto nuvoloso · Coperto

Parametri meteonivometrici registrati presso i campi di rilevamento il 06/02/2026.

Località	Comune	Quota (m.s.l.m.)	Altezza neve (cm)	Neve caduta nelle 24 ore (cm)	Temp. Min (°C)	Temp. Max (°C)	Condizioni del tempo
PESCHIERE	Amatrice (RI)	1270	0	0	+1	+9	Assenza di precipitazioni
M. CAIDURO	Cittareale (RI)	1300	10	3	0	+9	Assenza di precipitazioni
RIFUGIO SEBASTIANI	Micigliano (RI)	1825	43	0	N.P.	N.P.	Nebbia con cielo non visibile

(*) Rilievi fuori campo

L'INFORMAZIONE E' PREVENZIONE - LEGGI L'ATTUALE GRADO DI PERICOLO VALANGHE!

IL CAPO DEL CENTRO NAZIONALE METEOMONT
(Ten. Col. RFI Emanuela Gini)
FIRMA AUTOGRAFA OMESSA AI SENSI
DELL'ART.3 DEL D.LGS N.39/1993