RÉPUBLIQUE FRANÇAISE
Liberté Égalité Fraternité

METEO FRANCE
À VOS CÔTÉS, DANS UN CLIMAT QUI CHANGE

Bulletin d'estimation du risque d'avalanche
(valable en dehors des pistes balisées et ouvertes)

MASSIF : Aravis

Rédigé le vendredi 6 février 2026 à 16h

Estimation des risques pour le : SAMEDI 07 FÉVRIER

3

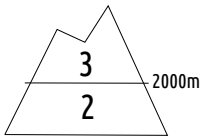

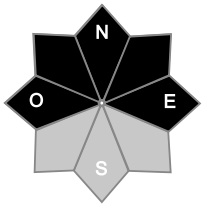

Au-dessus de 2000m indice de risque marqué, plus bas indice limité.

Départs spontanés : coulées au fil de l'ensoleillement

Déclenchements provoqués : plaques friables/nouvelles ou dures/anciennes

Indices de risque : 5 très fort - 4 fort - 3 marqué - 2 limité - 1 faible -- En noir : les pentes les plus dangereuses

Stabilité du manteau neigeux

Situation avalancheuse typique : neige ventée couche fragile persistante

Déclenchements provoqués :
* **Plaques friables dans la neige récente.** Formées depuis jeudi dans la nouvelle neige travaillée par le vent de SW. Surtout situées au-dessus de 1800/2000 m, principalement dans les versants NW,N, NE, E, où l'adhérence est plus précaire sur l'ancienne neige restée froide. Pas très nombreuses mais assez sensibles. Taille 1 à 2 (petite à moyenne). Observables : changement de qualité de neige sur une courte distance (par exemple poudreuse légère puis soudain dense).
* Plus rares, nettement moins probables, mais potentiellement piégeuses : **plaques dures sur couche fragile persistante**. Cette ancienne couche fragile enfouie, assez peu réactive actuellement, est présente dans les pentes E, N, W au-dessus de 1800 m. Difficilement déclenchable par un skieur, mais dans une configuration d'**avalanches en cascade** (une première avalanche en déclenche une seconde), cassure épaisse (60/90 cm) et large. Taille 2 (moyenne), voire 3 (grande) possible.

Départs spontanés :
* Petites avalanches ponctuelles dans les adrets raides, au fil de l'ensoleillement. Surtout près des falaises/rochers. Taille 1, rarement 2.

Qualité de la neige

Enneigement : légèrement déficitaire en dessous de 1600/1800 m, correct plus haut, sauf vers les crêtes soufflées. On peut chausser les skis vers 1000/1200 m. Pas de sous-couche sous 1400/1500 m, gare aux cailloux masqués.

Qualité de la neige ce samedi : fine couche de neige fraîche, un peu lourde sous 1600 m, plus froide et légère en altitude (15/20 cm sur fond meuble ou cartonné), mais localement soufflée/travaillée au-dessus de 2200 m environ.
Attention aux **corniches;** formées récemment et sensibles près des crêtes.

Aperçu météo pour le samedi 07 février

	nuit	matin	après-midi	soir

Soleil voilé, voile devenant plus épais l'après-midi. A 2000 m : -3 puis -1 DG.

Pluie-Neige	1 200 m			
Iso 0 °C	1 500 m	1 700 m	1 700 m	1 700 m
Vent 2000 m	↑ 10 km/h	↑ 5 km/h	↑ 5 km/h	↑ 5 km/h
Vent 2500 m	→ 20 km/h	↑ 10 km/h	↑ 10 km/h	↑ 10 km/h

Épaisseur de neige hors-piste

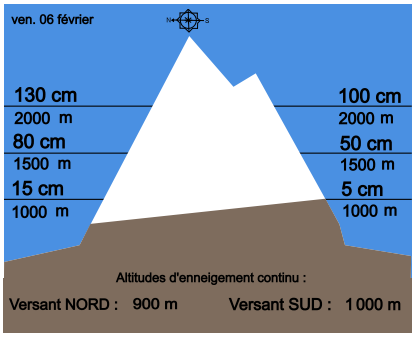

Précipitations à 1800 m

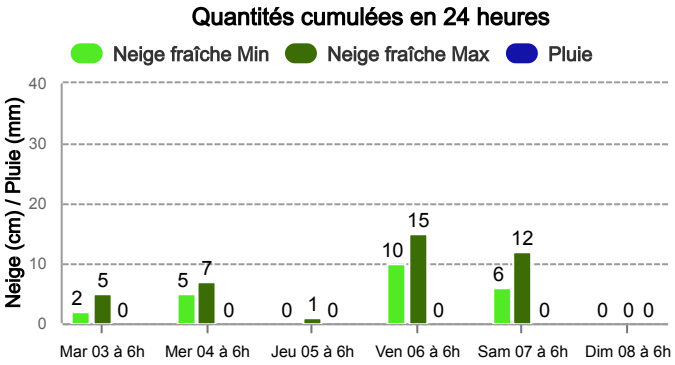

Tendance du dimanche 08 février

2

Indice de risque limité

Tassement des couches superficielles, encore des couches fragiles persistantes enfouies. Risque en légère baisse.

Pour consulter la vigilance en cours, veuillez vous rendre sur le site https://vigilance.meteofrance.fr/fr

Météo-France - 73 avenue de Paris, 94165 Saint-Mandé cedex - Contact : contact@meteo.fr

Rédigé par Météo-France avec la contribution des observateurs du réseau nivo-météorologiques. Partenariat : ANMSM (Maires de Stations de Montagne), DSF (Domaines Skiables de France), ADSP (Directeurs de Pistes et de la Sécurité des Stations de Sports d'Hiver) et autres acteurs de la montagne.

Bulletin neige & avalanches par téléphone au
0 892 68 10 20 Service 0,35 € / min + prix appel

RÉPUBLIQUE FRANÇAISE
Liberté Égalité Fraternité

METEO FRANCE
À VOS CÔTÉS, DANS UN CLIMAT QUI CHANGE

Bulletin d'estimation du risque d'avalanche

(valable en dehors des pistes balisées et ouvertes)

MASSIF : Aravis

Rédigé le vendredi 6 février 2026 à 16h

Conditions nivo-météo des 7 derniers jours

	sam. 31/01				dim. 01/02				lun. 02/02				mar. 03/02				mer. 04/02				jeu. 05/02				ven. 06/02			
	03h	09h	15h	21h	03h	09h	15h	21h	03h	09h	15h	21h	03h	09h	15h	21h	03h	09h	15h	21h	03h	09h	15h	21h	03h	09h	15h	21h
Météo																												
Vent (km/h)	30	15	10	10	10	20	25	30	40	55	60	65	70	60	55	45	35	35	25	25	30	35	50	45	50	50	40	30
à 2500m																												
Vent (km/h)	20	10	5	5	5	10	15	20	25	30	40	45	50	40	25	15	15	20	15	15	20	25	25	25	25	30	30	20
à 2000m																												

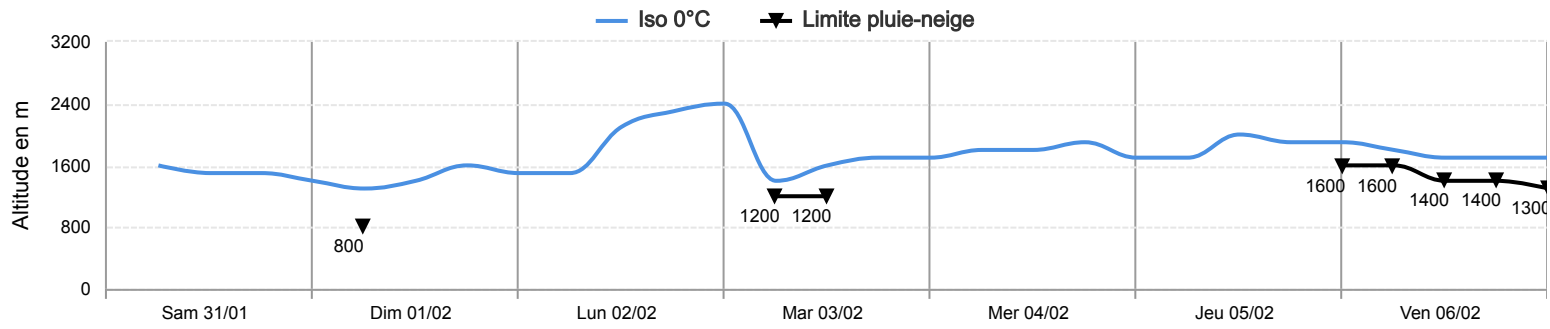

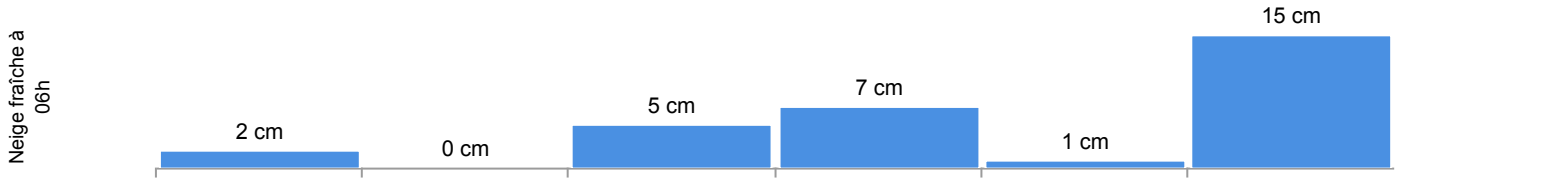

Risque d'avalanche	sam. 31/01	dim. 01/02	lun. 02/02	mar. 03/02	mer. 04/02	jeu. 05/02	ven. 06/02
	3	3	3	3	3	3	3

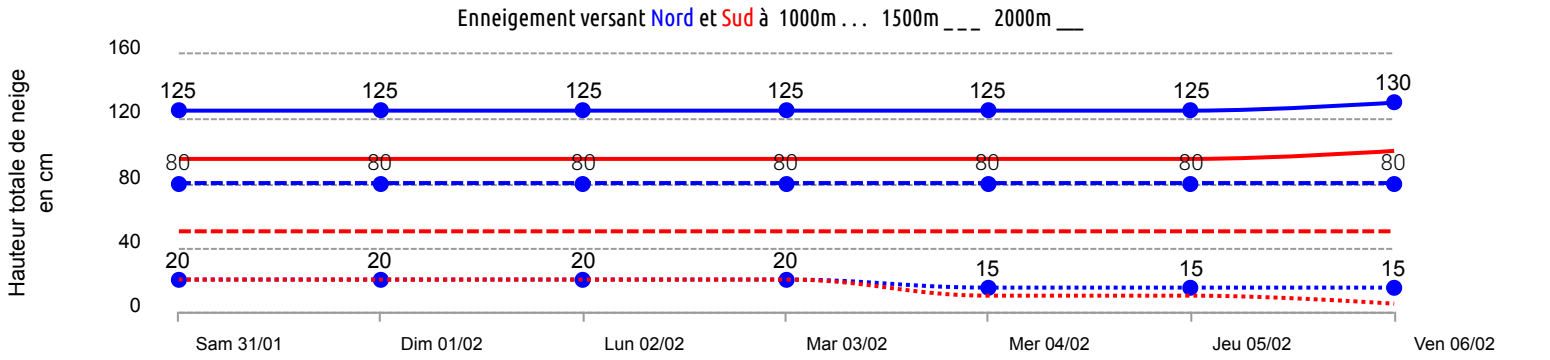

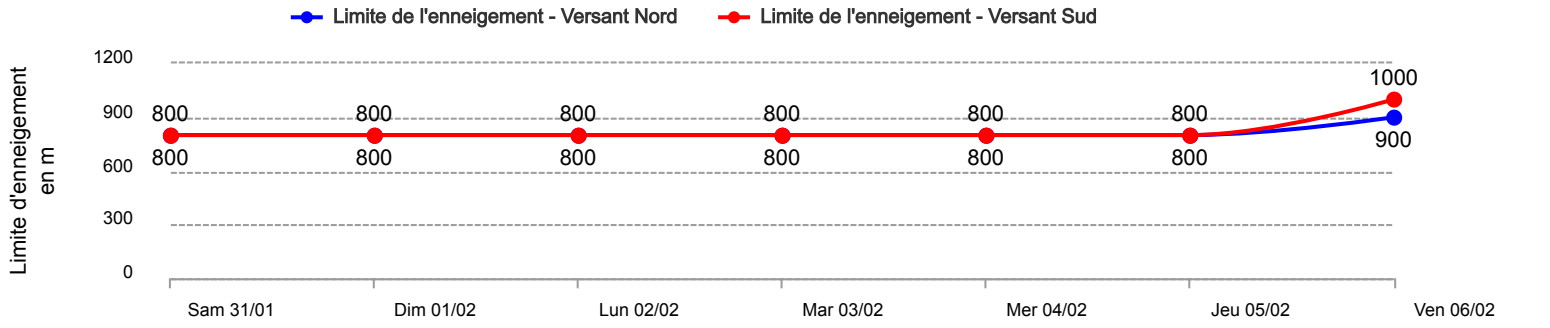

Pour consulter la vigilance en cours, veuillez vous rendre sur le site https://vigilance.meteofrance.fr/fr

Météo-France - 73 avenue de Paris, 94165 Saint-Mandé cedex - Contact : contact@meteo.fr

Rédigé par Météo-France avec la contribution des observateurs du réseau nivo-météorologiques. Partenariat : ANMSM (Maires de Stations de Montagne), DSF (Domaines Skiables de France), ADSP (Directeurs de Pistes et de la Sécurité des Stations de Sports d'Hiver) et autres acteurs de la montagne.

Bulletin neige & avalanches par téléphone au
0 892 68 10 20 Service 0,35 € / min + prix appel