# Bulletin d'estimation du risque d'avalanche
(valable en dehors des pistes balisées et ouvertes)

# MASSIF : Bauges

Rédigé le vendredi 6 février 2026 à 16h

## Estimation des risques pour le : SAMEDI 07 FÉVRIER

2

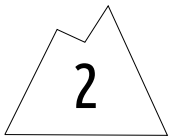


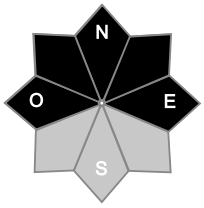


Indice de risque limité.

**Départs spontanés :** coulées au fil de l'ensoleillement

**Déclenchements provoqués :** plaques dans la neige récente

Indices de risque : 5 très fort - 4 fort - 3 marqué - 2 limité - 1 faible -- En noir : les pentes les plus dangereuses

## Stabilité du manteau neigeux

**Situation avalancheuse typique :** neige ventée

**Déclenchements provoqués :**
* **Plaques dans la neige récente,** majoritairement **friables.** Pas très nombreuses mais plutôt réactives sous les skis. Surtout en versants NW, N, NE, E, au-dessus de 1600/1800 m. A fortiori dans les secteurs où la neige a pu être travaillée par les vents de SW/W, près des crêtes mais aussi au beau milieu des pentes. Taille 1 à 2 (petite à moyenne).

**Départs spontanés :**
* Petites avalanches ponctuelles en adrets au fil de l'ensoleillement. Dans les pentes raides réchauffées, surtout près des rochers/falaises. Taille 1, rarement 2.

## Qualité de la neige

Enneigement : un peu déficitaire. On peut chausser les skis ou raquettes vers 1000 m environ (plutôt 1200 m en versants S). Peu de sous-couche sous 1500 m. Cailloux vers les crêtes peu enneigées.

Qualité de la neige ce samedi : fine couche de neige fraîche, 5/10 cm vers 1500 m, 20 cm à 2000 m. Elle repose sur une neige humidifié/croûtée en dessous de 1600/1800 m, et un fond plus meuble au-dessus de 1600/1800 m (sauf vers les crêtes : fond soufflé/carton).

## Aperçu météo pour le samedi 07 février

| nuit | matin | après-midi | soir |
|---|---|---|---|
| | | | |

Soleil voilé, voile devenant plus épais l'après-midi. A 2000 m : -3 puis -1 DG.

| Pluie-Neige | | | | |
|---|---|---|---|---|
| Iso 0 °C | 1700 m | 1700 m | 1700 m | 1700 m |
| Vent 1500 m | ↑ 10 km/h | ↓ 5 km/h | ↘ 5 km/h | ↙ 5 km/h |
| Vent 2000 m | ↗ 20 km/h | ↗ 10 km/h | ↘ 10 km/h | ↙ 10 km/h |

## Épaisseur de neige hors-piste

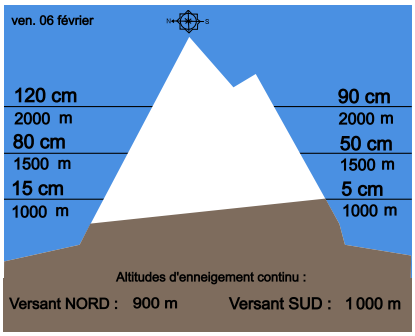


## Précipitations à 1800 m

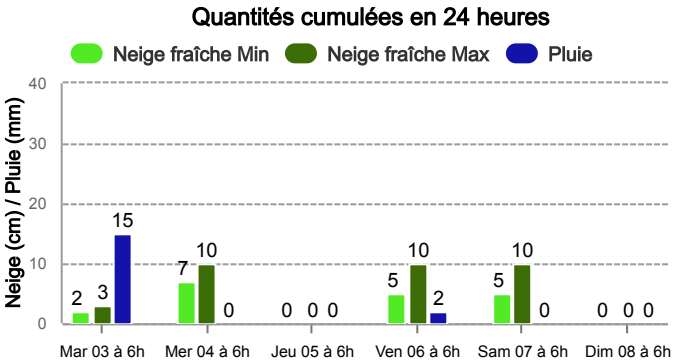


## Tendance du dimanche 08 février

2

**Indice de risque limité**

Tassement des couches superficielles, encore des couches fragiles persistantes enfouies. Risque stationnaire ou en légère baisse.

Pour consulter la vigilance en cours, veuillez vous rendre sur le site https://vigilance.meteofrance.fr/fr

Météo-France - 73 avenue de Paris, 94165 Saint-Mandé cedex - Contact : contact@meteo.fr

Rédigé par Météo-France avec la contribution des observateurs du réseau nivo-météorologiques. Partenariat : ANMSM (Maires de Stations de Montagne), DSF (Domaines Skiables de France), ADSP (Directeurs de Pistes et de la Sécurité des Stations de Sports d'Hiver) et autres acteurs de la montagne.

Bulletin neige & avalanches par téléphone au
0 892 68 10 20 Service 0,35 € / min + prix appel

RÉPUBLIQUE FRANÇAISE
*Liberté Égalité Fraternité*

METEO FRANCE
À VOS CÔTÉS, DANS UN CLIMAT QUI CHANGE

# Bulletin d'estimation du risque d'avalanche

## (valable en dehors des pistes balisées et ouvertes)

# MASSIF : Bauges

Rédigé le vendredi 6 février 2026 à 16h

## Conditions nivo-météo des 7 derniers jours

| | sam. 31/01 | | | | dim. 01/02 | | | | lun. 02/02 | | | | mar. 03/02 | | | | mer. 04/02 | | | | jeu. 05/02 | | | | ven. 06/02 | | | |
|---|---|---|---|---|---|---|---|---|---|---|---|---|---|---|---|---|---|---|---|---|---|---|---|---|---|---|---|---|
| | 03h | 09h | 15h | 21h | 03h | 09h | 15h | 21h | 03h | 09h | 15h | 21h | 03h | 09h | 15h | 21h | 03h | 09h | 15h | 21h | 03h | 09h | 15h | 21h | 03h | 09h | 15h | 21h |
| Météo | | | | | | | | | | | | | | | | | | | | | | | | | | | | |
| Vent (km/h) | 20 | 10 | 10 | 10 | 15 | 10 | 20 | 30 | 30 | 40 | 50 | 55 | 55 | 45 | 35 | 30 | 20 | 20 | 25 | 35 | 30 | 30 | 30 | 25 | 30 | 30 | 25 | 20 |
| à 2000m | | | | | | | | | | | | | | | | | | | | | | | | | | | | |
| Vent (km/h) | 15 | 5 | 5 | 5 | 10 | 5 | 10 | 15 | 20 | 25 | 30 | 30 | 40 | 35 | 25 | 20 | 10 | 10 | 15 | 25 | 20 | 20 | 20 | 20 | 25 | 25 | 20 | 10 |
| à 1500m | | | | | | | | | | | | | | | | | | | | | | | | | | | | |

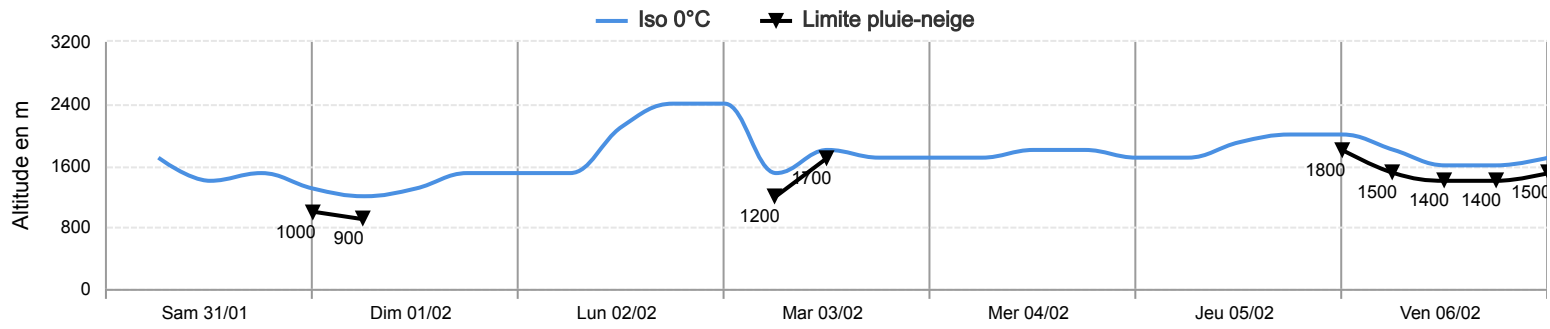


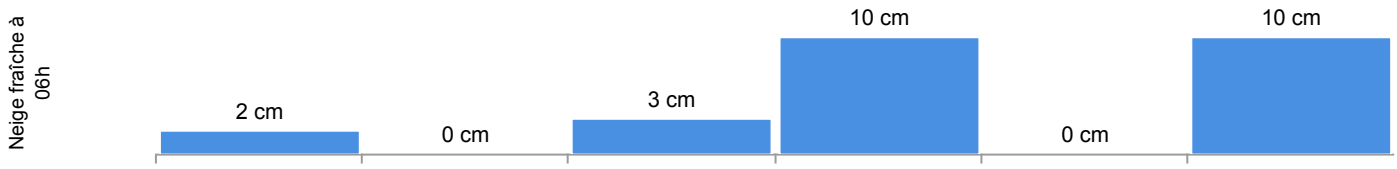


| Risque d'avalanche | sam. 31/01 | dim. 01/02 | lun. 02/02 | mar. 03/02 | mer. 04/02 | jeu. 05/02 | ven. 06/02 |
|---|---|---|---|---|---|---|---|
| | 2 | 2 | 2 | 3 | 3 | 3 | 3 |

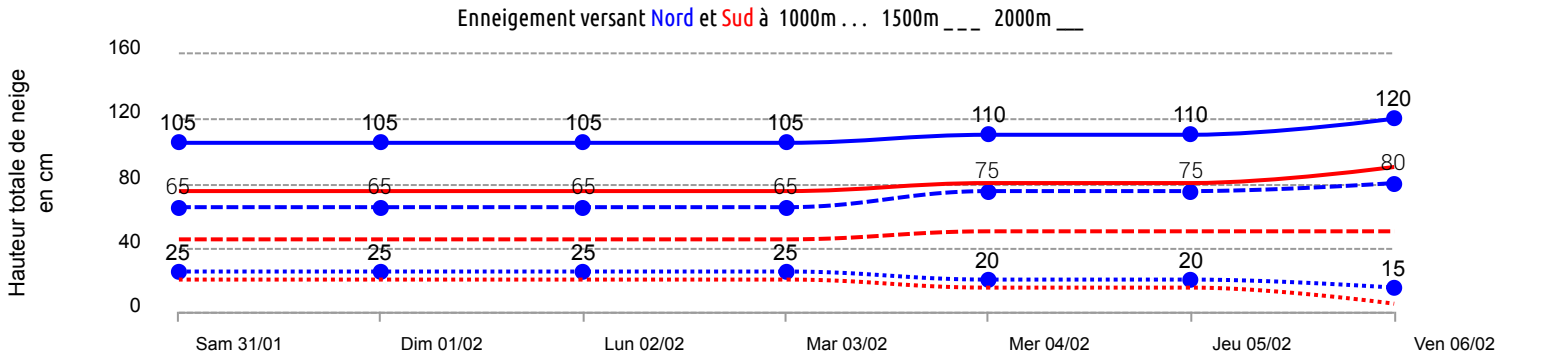


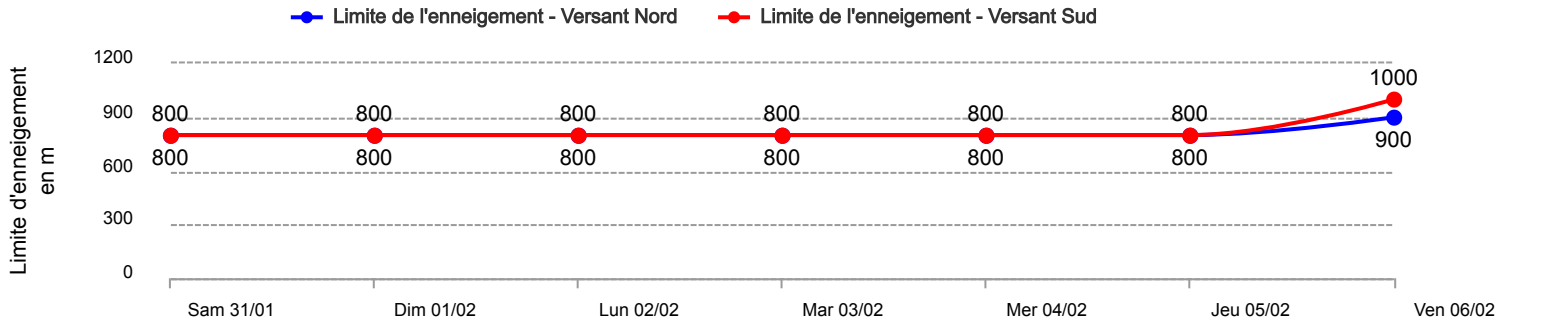


Pour consulter la vigilance en cours, veuillez vous rendre sur le site https://vigilance.meteofrance.fr/fr


**Météo-France - 73 avenue de Paris, 94165 Saint-Mandé cedex - Contact : contact@meteo.fr**



Rédigé par Météo-France avec la contribution des observateurs du réseau nivo-météorologiques. Partenariat : ANMSM (Maires de Stations de Montagne), DSF (Domaines Skiables de France), ADSP (Directeurs de Pistes et de la Sécurité des Stations de Sports d'Hiver) et autres acteurs de la montagne.



Bulletin neige & avalanches par téléphone au
0 892 68 10 20 Service 0,35 € / min + prix appel