Bulletin d'estimation du risque d'avalanche

(valable en dehors des pistes balisées et ouvertes)

MASSIF : Beaufortain

Rédigé le vendredi 6 février 2026 à 16h

Estimation des risques pour le : SAMEDI 07 FÉVRIER

NOMBREUSES PLAQUES D'ASPECT POUDREUX.

3

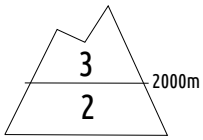

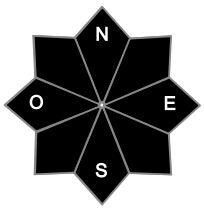

Au-dessus de 2000m indice de risque marqué, plus bas indice limité.

Départs spontanés : départs ponctuels au gré des éclaircies.

Déclenchements provoqués : nombreuses plaques poudreuses.

Indices de risque : 5 très fort - 4 fort - 3 marqué - 2 limité - 1 faible -- En noir : les pentes les plus dangereuses

Stabilité du manteau neigeux

Situation avalancheuse typique : neige fraîche couche fragile persistante

Déclenchements provoqués : de nombreuses **plaques friables d'aspect poudreux** sont en place près des crêtes comme dans les pentes. Elles restent réactives en journée dans les versants Est, Nord et Ouest, et vivent leur dernières heures dans les versants ensoleillés (Sud Est à Sud Ouest). Elles occasionnent des cassures de ~40 cm et des avalanches de taille 1 à 2 (petite à moyenne). **Observables :** accumulation de neige fraiche supérieure à la moyenne environnante, neige dense en surface et plus molle en dessous, fissures devant les skis.

Au-dessus de 2000m et en versants froids (Est/Nord/Ouest) des couches fragiles persistantes enfouies profondément dans le manteau pourront être localement déclenchées, en cascade par ces plaques de surface et alors **engendrer de plus grandes et larges avalanches taille 3.**

Départs spontanés : au gré de la course du Soleil, des départs ponctuels (avalanches en poire) ou linéaires (cassures) s'observent dans les pentes raides d'altitude, au départ des rochers. Taille 1, au pire 2 si la topographie s'y prête.

Qualité de la neige

Enneigement : Un peu en dessous des normales de saison mais les chutes à venir (dans la semaine) devraient améliorer nettement l'enneigement

Limite skiable : Les versants froids voyant pas ou peu le soleil ont gardé de la neige à basse altitude, skiable sur l'herbe ou sur pistes forestières dès 700 à 900m. Sous bois skiables dès 1200m. En versant sud skiable dès 1300/1400m en prairies pas trop raides, 1600/1700m en Sud raide.

Qualité de la neige : au réveil, la neige récente est croutée jusqu'à ~2000 m ? Plus haut dans certains secteurs ... Encore plus haut, elle est poudreuse, légèrement travaillée par le vent à l'approche des crêtes. Dans les versants "chauds" (Sud Est à Sud Ouest), elle chauffe au gré de la course du Soleil. A basse altitude, la croute ramollie. Plus haut, la neige se met à coller. Gare au bottage !

Aperçu météo pour le samedi 07 février

	nuit	matin	après-midi	soir
Beau à voilé.				
Pluie-Neige				
Iso 0 °C	1 600 m	1 900 m	1 900 m	1 700 m
Vent 2000 m	5 km/h	5 km/h	0 km/h	0 km/h
Vent 3000 m	15 km/h	10 km/h	5 km/h	5 km/h

Épaisseur de neige hors-piste

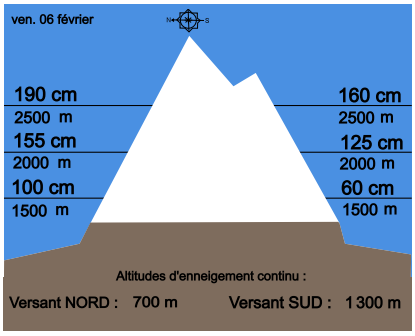

Précipitations à 1800 m

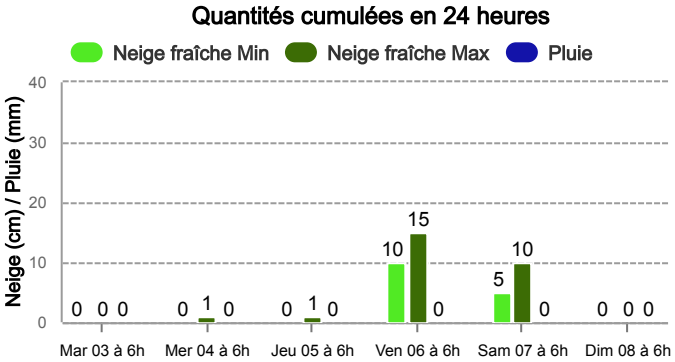

Tendance du dimanche 08 février

2

Indice de risque limité

Stabilisation des plaques "de surface". La couche fragile persistante enfouie est difficilement sollicitable.

Pour consulter la vigilance en cours, veuillez vous rendre sur le site https://vigilance.meteofrance.fr/fr

Météo-France - 73 avenue de Paris, 94165 Saint-Mandé cedex - Contact : contact@meteo.fr

Rédigé par Météo-France avec la contribution des observateurs du réseau nivo-météorologiques. Partenariat : ANMSM (Maires de Stations de Montagne), DSF (Domaines Skiables de France), ADSP (Directeurs de Pistes et de la Sécurité des Stations de Sports d'Hiver) et autres acteurs de la montagne.

Bulletin neige & avalanches par téléphone au 0 892 68 10 20 Service 0,35 € / min + prix appel

Bulletin d'estimation du risque d'avalanche

(valable en dehors des pistes balisées et ouvertes)

MASSIF : Beaufortain

Rédigé le vendredi 6 février 2026 à 16h

Conditions nivo-météo des 7 derniers jours

	sam. 31/01				dim. 01/02				lun. 02/02				mar. 03/02				mer. 04/02				jeu. 05/02				ven. 06/02			
	03h	09h	15h	21h	03h	09h	15h	21h	03h	09h	15h	21h	03h	09h	15h	21h	03h	09h	15h	21h	03h	09h	15h	21h	03h	09h	15h	21h
Météo																												
Vent (km/h)	25	20	15	15	10	10	15	20	35	35	50	65	70	65	50	45	60	30	20	20	30	25	25	30	40	35	25	20
à 3000m																												
Vent (km/h)	15	10	10	10	5	5	10	10	20	20	40	55	60	50	30	20	50	20	10	10	15	15	15	25	25	20	15	10
à 2000m																												

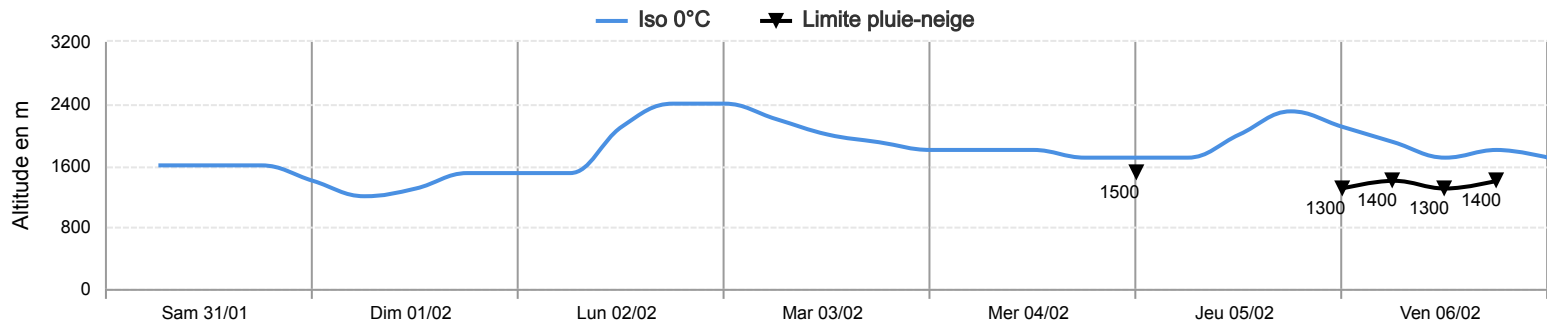



Risque d'avalanche	sam. 31/01	dim. 01/02	lun. 02/02	mar. 03/02	mer. 04/02	jeu. 05/02	ven. 06/02
	3	3	3	3	3	2	3

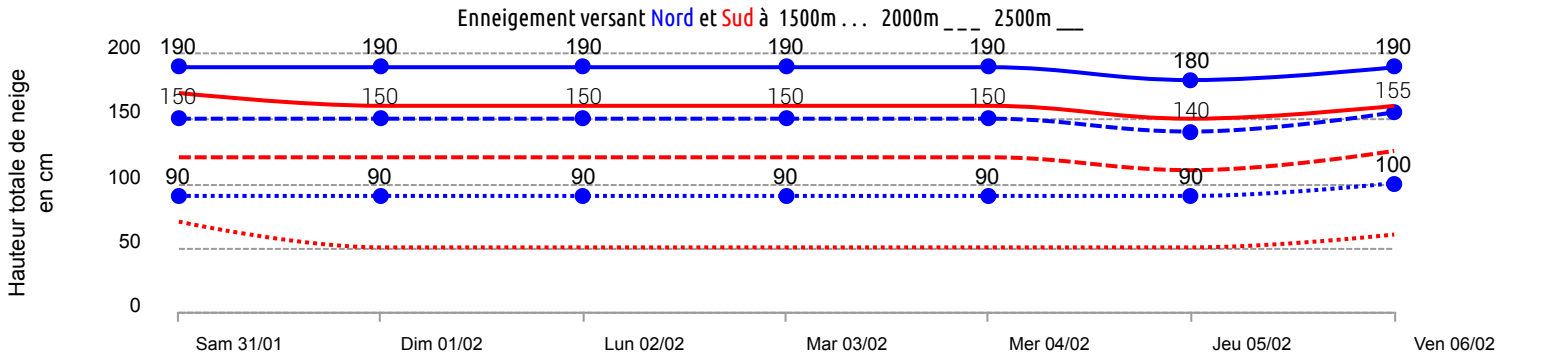

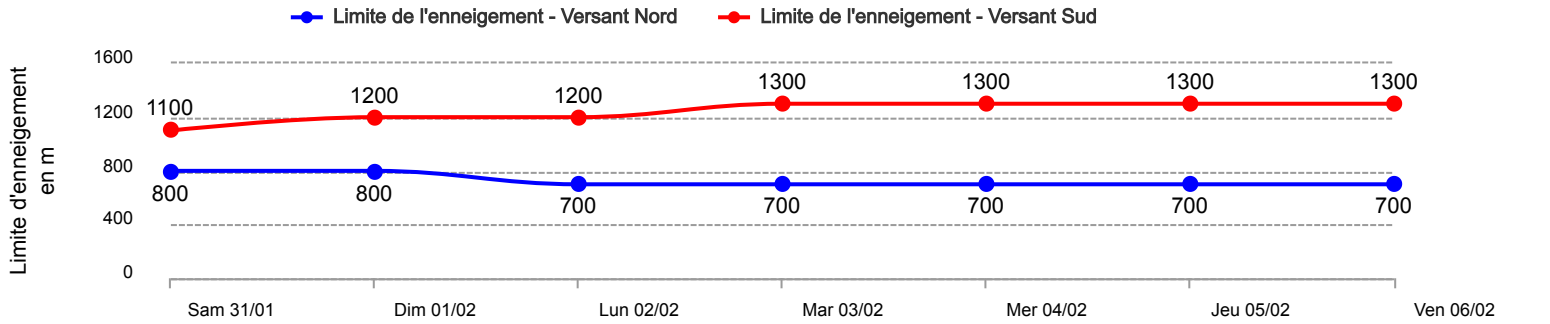

Pour consulter la vigilance en cours, veuillez vous rendre sur le site https://vigilance.meteofrance.fr/fr

Météo-France - 73 avenue de Paris, 94165 Saint-Mandé cedex - Contact : contact@meteo.fr

Rédigé par Météo-France avec la contribution des observateurs du réseau nivo-météorologiques. Partenariat : ANMSM (Maires de Stations de Montagne), DSF (Domaines Skiables de France), ADSP (Directeurs de Pistes et de la Sécurité des Stations de Sports d'Hiver) et autres acteurs de la montagne.

Bulletin neige & avalanches par téléphone au

0 892 68 10 20 Service 0,35 € / min + prix appel