Bulletin d'estimation du risque d'avalanche

(valable en dehors des pistes balisées et ouvertes)

MASSIF : Capcir Puymorens

Rédigé le vendredi 6 février 2026 à 16h

Estimation des risques pour le : SAMEDI 07 FÉVRIER

PERSISTANCE DE QUELQUES INSTABILITÉS EN ALTITUDE

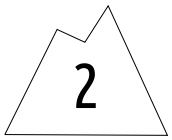

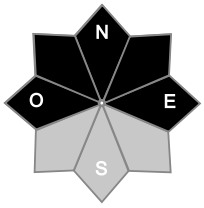

Indice de risque limité.

Départs spontanés : En neige humide

Déclenchements provoqués : Persistance de plaques à vent près des cols et crêtes

Indices de risque : 5 très fort - 4 fort - 3 marqué - 2 limité - 1 faible -- En noir : les pentes les plus dangereuses

Stabilité du manteau neigeux

Situation avalancheuse typique : couche fragile persistante neige humide

Déclenchements provoqués :

* Au-dessus de 2000m dans les secteurs à l'abri du vent de sud, des déclenchements d'avalanches de taille moyenne (T2), voire de grande taille (T3) dans les secteurs les plus défavorables de haute montagne, sont à attendre. En effet, des structures de plaques non encore complètement stabilisées y sont présentes. Ces plaques d'aspect variable, généralement peu épaisses sont encore facilement déclenchables en haute montagne et dans les pentes bien raides (observables : neige sèche en surface, bruits d'effondrement au sein du manteau neigeux ou fissures qui se propagent devant les skis).

Facteur aggravant : il subsiste au moins par endroits des couches fragiles persistantes dans un large secteur nord, maintenant assez profondément enfouies. Elles sont difficilement sollicitables au passage d'un pratiquant, éventuellement en abord de couloir ou dans des ruptures de pente, mais elles peuvent aussi être sollicitées en cascade par un premier départ de plaque peu épaisse. D'importants volumes peuvent alors être mobilisés.

* En dessous de 2000m, là où croûtes de regel et neige bien humidifiée prédominent en surface, le risque de départ accidentel est plus faible.

Départs spontanés :

* Départs ponctuels en surface (tailles 1 voire 2) en neige humide possibles dans les secteurs ensoleillés;
* Avalanches de glissement possibles en pentes herbeuses ou sur des dalles rocheuses en toutes orientations (Taille 1 ou 2). (observables : présence de gueules de baleine, reptations).

Qualité de la neige

Enneigement :

L'enneigement est excellent et nettement excédentaire pour la saison. La limite de skiabillité se situe vers 1500 m dans les meilleures configurations.

État de la neige :

En matinée, on pourra trouver un petit saupoudrage de la nuit par endroits jusque vers 1600m. Ailleurs, la neige devrait être dure ou croutée à basse et moyenne altitude. Neige encore sèche ou froide au-delà de 2000/2100m dans les secteurs ombragés. Neige souvent dure et regelée sur les crêtes des avants monts.

En journée, nouveau cycle d'humidification jusqu'au moins 2100/2200m dans les versants raides ensoleillés.

Aperçu météo pour le samedi 07 février

Après le petit passage perturbé de la nuit n'apportant que peu de neige, belle journée dans une atmosphère un peu rafraîchie

	nuit	matin	après-midi	soir
Pluie-Neige	1 600 m			
Iso 0 °C	2 000 m	1 800 m	2 000 m	2 000 m
Vent 2000 m	↑ 20 km/h	↘ 15 km/h	↘ 15 km/h	→ 25 km/h
Vent 3000 m	↘ 30 km/h	↘ 20 km/h	↘ 20 km/h	→ 35 km/h

Épaisseur de neige hors-piste

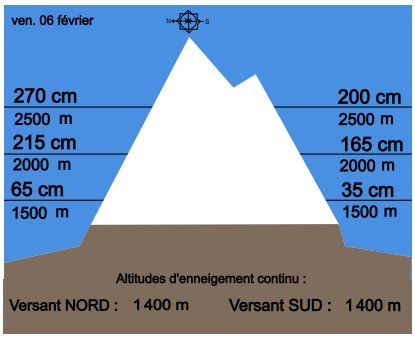

Précipitations à 1800 m

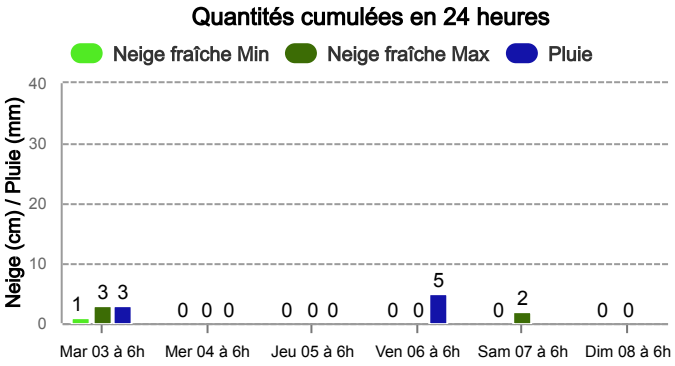

Tendance du dimanche 08 février

Indice de risque limité

Au vu des chutes de neige prévues dimanche, maintien a minima du risque 2.

Pour consulter la vigilance en cours, veuillez vous rendre sur le site https://vigilance.meteofrance.fr/fr

Météo-France - 73 avenue de Paris, 94165 Saint-Mandé cedex - Contact : contact@meteo.fr

Rédigé par Météo-France avec la contribution des observateurs du réseau nivo-météorologiques. Partenariat : ANMSM (Maires de Stations de Montagne), DSF (Domaines Skiables de France), ADSP (Directeurs de Pistes et de la Sécurité des Stations de Sports d'Hiver) et autres acteurs de la montagne.

Bulletin neige & avalanches par téléphone au

0 892 68 10 20 Service 0,35 € / min + prix appel

RÉPUBLIQUE FRANÇAISE
Liberté Égalité Fraternité

METEO FRANCE
À VOS CÔTÉS, DANS UN CLIMAT QUI CHANGE

Bulletin d'estimation du risque d'avalanche

(valable en dehors des pistes balisées et ouvertes)

MASSIF : Capcir Puymorens

Rédigé le vendredi 6 février 2026 à 16h

Conditions nivo-météo des 7 derniers jours

	sam. 31/01				dim. 01/02				lun. 02/02				mar. 03/02				mer. 04/02				jeu. 05/02				ven. 06/02			
	03h	09h	15h	21h	03h	09h	15h	21h	03h	09h	15h	21h	03h	09h	15h	21h	03h	09h	15h	21h	03h	09h	15h	21h	03h	09h	15h	21h
Météo																												
Vent (km/h)	55	85	80	70	55	35	35	30	60	80	100	65	50	35	40	30	40	55	50	40	65	80	75	55	40	25	25	30
à 3000m																												
Vent (km/h)	35	65	65	50	35	25	20	15	20	50	75	45	35	25	30	25	30	45	35	30	45	60	55	40	25	15	15	20
à 2000m																												

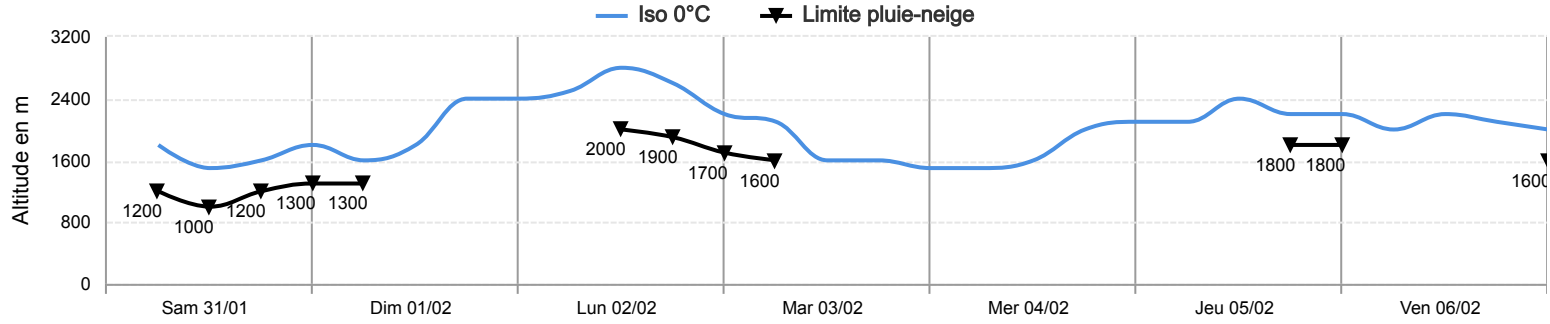

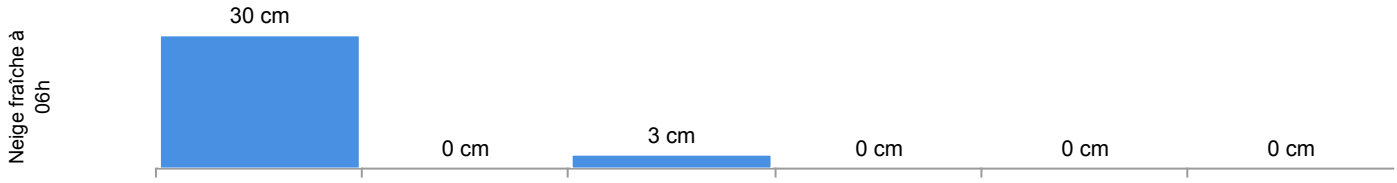

Risque d'avalanche	sam. 31/01	dim. 01/02	lun. 02/02	mar. 03/02	mer. 04/02	jeu. 05/02	ven. 06/02
	3	4	3	3	3	3	2

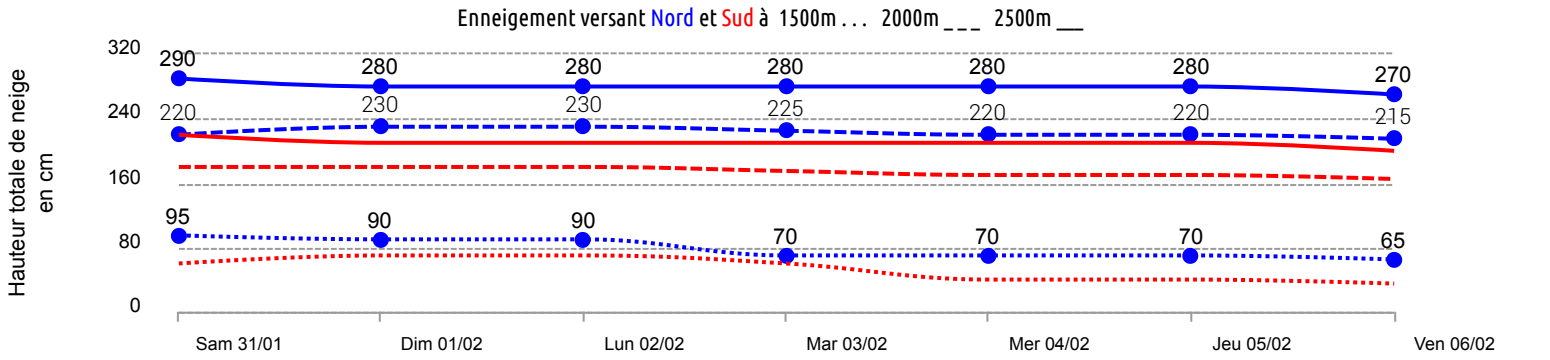

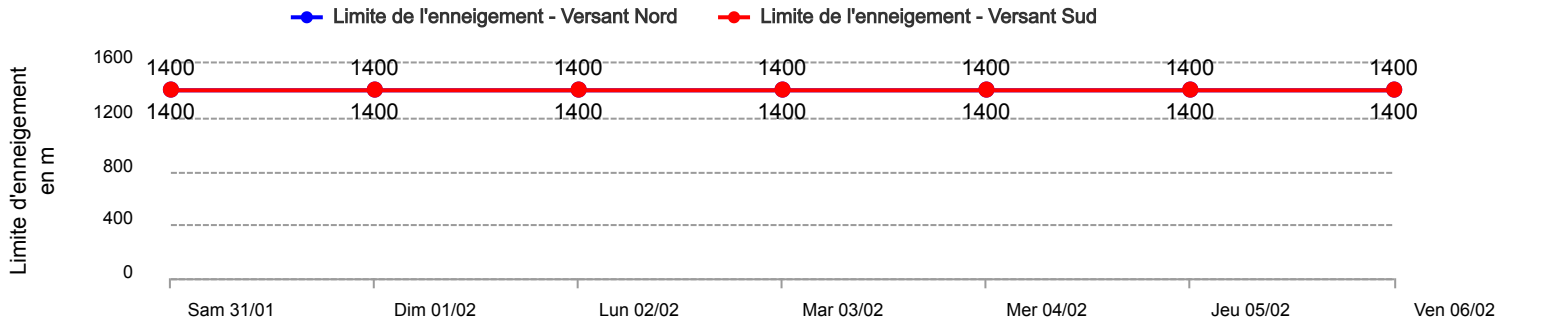

Pour consulter la vigilance en cours, veuillez vous rendre sur le site https://vigilance.meteofrance.fr/fr

Météo-France - 73 avenue de Paris, 94165 Saint-Mandé cedex - Contact : contact@meteo.fr

Rédigé par Météo-France avec la contribution des observateurs du réseau nivo-météorologiques. Partenariat : ANMSM (Maires de Stations de Montagne), DSF (Domaines Skiables de France), ADSP (Directeurs de Pistes et de la Sécurité des Stations de Sports d'Hiver) et autres acteurs de la montagne.

Bulletin neige & avalanches par téléphone au

0 892 68 10 20 Service 0,35 € / min + prix appel