Bulletin d'estimation du risque d'avalanche
(valable en dehors des pistes balisées et ouvertes)

MASSIF : Champsaur

Rédigé le vendredi 6 février 2026 à 16h

Estimation des risques pour le : SAMEDI 07 FÉVRIER

PLAQUES FACILES À DÉCLENCHER DANS LA NEIGE RÉCENTE - QUELQUES CASSURES VOLUMINEUSES POSSIBLES

3

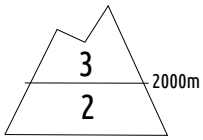

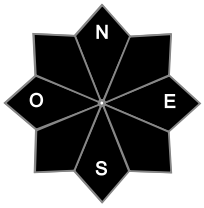

Au-dessus de 2000m indice de risque marqué, plus bas indice limité.

Départs spontanés : en neige récente humidifiée, voire en plaque.

Déclenchements provoqués : plaques faciles à déclencher.

Indices de risque : 5 très fort - 4 fort - 3 marqué - 2 limité - 1 faible -- En noir : les pentes les plus dangereuses

Stabilité du manteau neigeux

Situation avalancheuse typique : neige fraîche couche fragile persistante

Déclenchements provoqués : les plaques d'aspect souvent poudreux formées lors des dernières chutes de neige restent encore faciles à déclencher dans de nombreuses pentes, surtout au-dessus de 2000 m. Cassures parfois larges quand la topographie est favorable. Le déclenchement de ces plaques provoque des avalanches souvent moyennes (taille 2).
Dans les ubacs (orientations ouest, nord à est), des cassures épaisses (> 1 m) sont envisageables, en cas de rupture sur une couche fragile persistante enfouie en profondeur dans le manteau neigeux. Déclenchement plus difficile, mais pouvant être facilité par le départ d'une première plaque de surface. Avalanches moyennes à grandes (taille 2 à 3).

Départs spontanés : quelques départs de neige récente humidifiée dans les pentes raides au soleil près des rochers. Avalanches petites à moyennes (taille 1 à 2), en poire. Ces départs ponctuels peuvent déclencher des avalanches de plaques sur leur trajet, avec les caractéristiques décrites au paragraphe des déclenchements provoqués.

Qualité de la neige

L'enneigement est désormais excédentaire pour un début février.
Données observées jeudi : 40 cm au hameau des Portes dans le Valgaudemar à 1270 m, 115 cm à la Nivôse d'Orcières à 2280 m, et 150 cm au-dessus de Prapic à 2480 m.

Limite d'enneigement skiable : la plupart des itinéraires sont skiables dès les fonds de vallées.

État de la neige de surface : 20/30 cm de neige fraîche en général, tombée humide sous 1800/2000 m. Elle est plus légère au-dessus, parfois densifiée ou cartonnée par le vent près des crêtes. Fine croûte le matin sous 2000/2100 m en général, s'humidifiant au soleil en journée.

Aperçu météo pour le samedi 07 février

nuit	matin	après-midi	soir

Temps sec, voilé à nuageux, mais les sommets restent hors de la couche nuageuse. Vent faible à toute altitude.

Pluie-Neige				
Iso 0 °C	1 600 m	1 700 m	1 800 m	1 800 m
Vent 2000 m	5 km/h	5 km/h	5 km/h	10 km/h
Vent 3000 m	20 km/h	15 km/h	10 km/h	10 km/h

Épaisseur de neige hors-piste

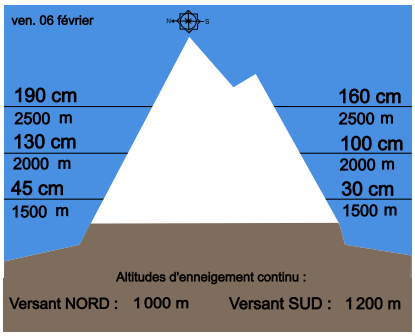

Précipitations à 1800 m

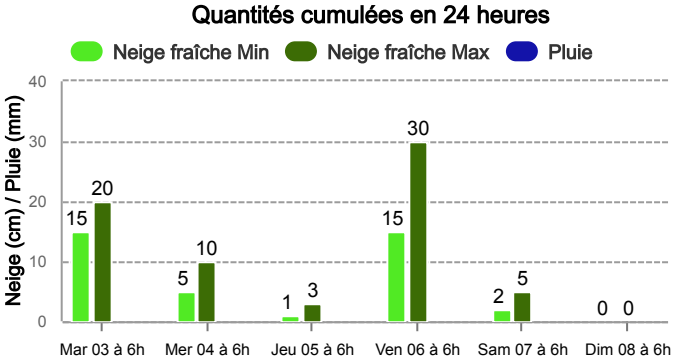

Tendance du dimanche 08 février

3

Indice de risque marqué

Lente stabilisation du manteau neigeux, avec encore des plaques pouvant céder au passage d'un skieur. Maintien d'un risque marqué.

Pour consulter la vigilance en cours, veuillez vous rendre sur le site https://vigilance.meteofrance.fr/fr

Météo-France - 73 avenue de Paris, 94165 Saint-Mandé cedex - Contact : contact@meteo.fr

Rédigé par Météo-France avec la contribution des observateurs du réseau nivo-météorologiques. Partenariat : ANMSM (Maires de Stations de Montagne), DSF (Domaines Skiables de France), ADSP (Directeurs de Pistes et de la Sécurité des Stations de Sports d'Hiver) et autres acteurs de la montagne.

Bulletin neige & avalanches par téléphone au
0 892 68 10 20 Service 0,35 € / min + prix appel

RÉPUBLIQUE FRANÇAISE
Liberté Égalité Fraternité

METEO FRANCE
À VOS CÔTÉS, DANS UN CLIMAT QUI CHANGE

Bulletin d'estimation du risque d'avalanche

(valable en dehors des pistes balisées et ouvertes)

MASSIF : Champsaur

Rédigé le vendredi 6 février 2026 à 16h

Conditions nivo-météo des 7 derniers jours

	sam. 31/01				dim. 01/02				lun. 02/02				mar. 03/02				mer. 04/02				jeu. 05/02				ven. 06/02			
	03h	09h	15h	21h	03h	09h	15h	21h	03h	09h	15h	21h	03h	09h	15h	21h	03h	09h	15h	21h	03h	09h	15h	21h	03h	09h	15h	21h
Météo																												
Vent (km/h)	20	20	10	10	10	10	25	45	35	25	50	80	100	70	50	35	35	30	20	15	35	30	60	20	50	50	50	30
à 3000m																												
Vent (km/h)	10	10	10	10	10	10	15	20	20	10	20	35	50	35	20	15	20	20	15	10	10	10	20	5	30	40	30	20
à 2000m																												

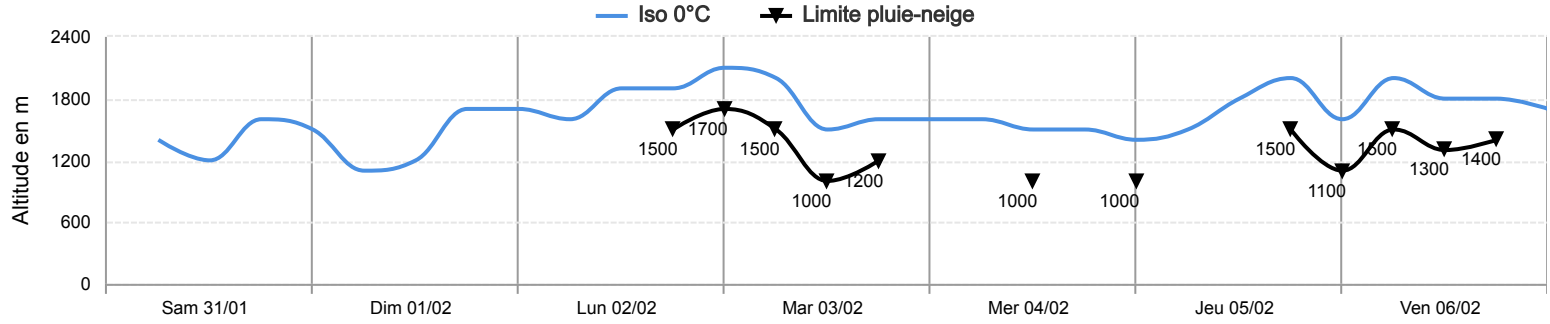

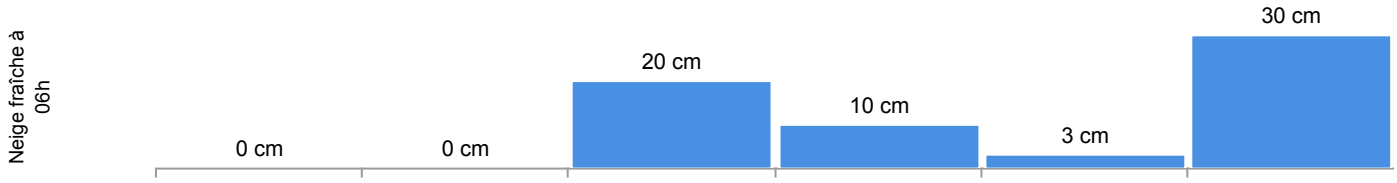

Risque d'avalanche	sam. 31/01	dim. 01/02	lun. 02/02	mar. 03/02	mer. 04/02	jeu. 05/02	ven. 06/02
	3	3	3	4	3	3	4

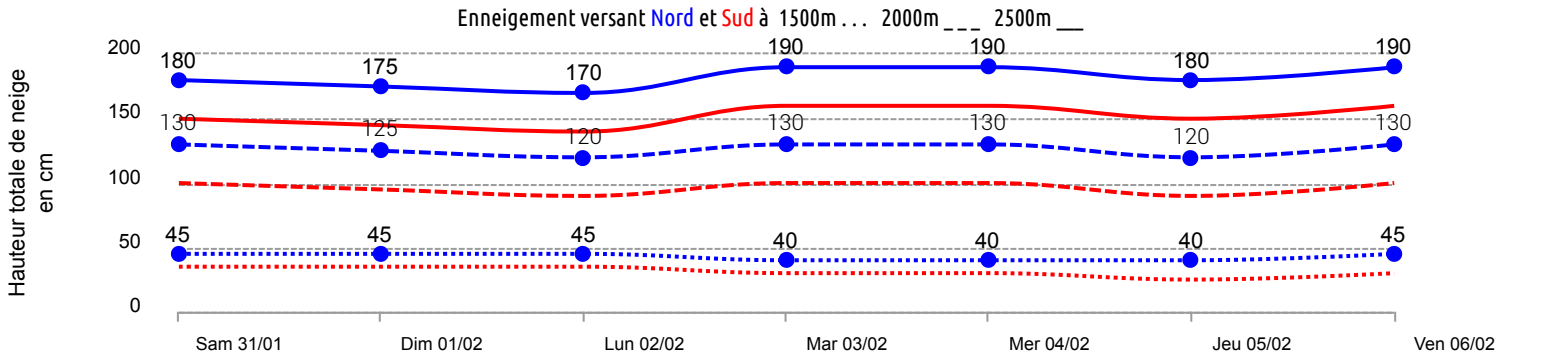

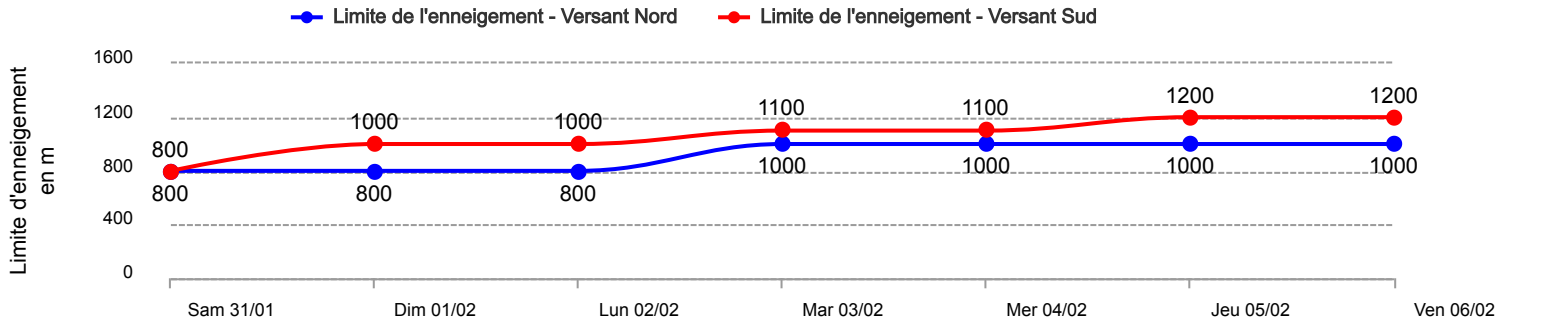

Pour consulter la vigilance en cours, veuillez vous rendre sur le site https://vigilance.meteofrance.fr/fr

Météo-France - 73 avenue de Paris, 94165 Saint-Mandé cedex - Contact : contact@meteo.fr

Rédigé par Météo-France avec la contribution des observateurs du réseau nivo-météorologiques. Partenariat : ANMSM (Maires de Stations de Montagne), DSF (Domaines Skiables de France), ADSP (Directeurs de Pistes et de la Sécurité des Stations de Sports d'Hiver) et autres acteurs de la montagne.

Bulletin neige & avalanches par téléphone au
0 892 68 10 20 Service 0,35 € / min + prix appel