Bulletin d'estimation du risque d'avalanche
(valable en dehors des pistes balisées et ouvertes)

MASSIF : Chartreuse

Rédigé le vendredi 6 février 2026 à 16h

Estimation des risques pour le : SAMEDI 07 FÉVRIER

QUELQUES INSTABILITÉS LOCALISÉES PRÈS DES CRÊTES LES PLUS HAUTES.

2

2

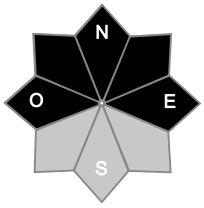

Indice de risque limité.

Départs spontanés : Rares purges dans les pentes au soleil.

Déclenchements provoqués : Rares plaques sur la partie haute du massif.

Indices de risque : 5 très fort - 4 fort - 3 marqué - 2 limité - 1 faible -- En noir : les pentes les plus dangereuses

Stabilité du manteau neigeux

Situation avalancheuse typique : neige ventée

Déclenchements provoqués : le risque concerne soit une plaque friable dans les pentes sommitales des ubacs où l'humidification et le tassement du manteau neigeux ne se seraient pas encore produits (taille1), soit bien plus rarement la rupture d'une plaque plus dure reposant sur une couche fragile présente en profondeur dans le manteau neigeux (taille 2).

Départs spontanés : des purges de taille 1, plus rarement 2, se sont déjà produites ce vendredi. L'activité avalancheuse naturelle s'annonce plus modeste samedi avec seulement quelques départs spontanés de neige humide en pentes raides encore vierges.

Qualité de la neige

Qualification de l'enneigement : l'enneigement est bon pour la saison, sauf aux altitudes les plus basses.

Limites skiables : vers 1100/1400 m.

Qualité de la neige samedi : Neige récente humidifiée en surface, croûtée en début de journée.

Aperçu météo pour le samedi 07 février

	nuit	matin	après-midi	soir
Pluie-Neige	1 300 m			
Iso 0 °C	1 600 m	1 800 m	1 700 m	1 700 m
Vent 1500 m	10 km/h	5 km/h	10 km/h	10 km/h
Vent 2000 m	15 km/h	15 km/h	5 km/h	5 km/h

Épaisseur de neige hors-piste

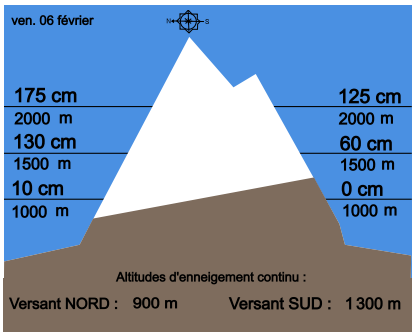

Précipitations à 1800 m

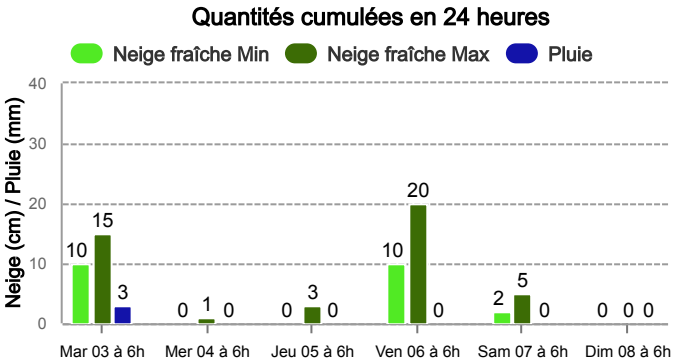

Tendance du dimanche 08 février

2

Indice de risque limité

Dimanche, poursuite de la stabilisation du manteau neigeux. Risques en baisse.

Pour consulter la vigilance en cours, veuillez vous rendre sur le site https://vigilance.meteofrance.fr/fr

Météo-France - 73 avenue de Paris, 94165 Saint-Mandé cedex - Contact : contact@meteo.fr

Rédigé par Météo-France avec la contribution des observateurs du réseau nivo-météorologiques. Partenariat : ANMSM (Maires de Stations de Montagne), DSF (Domaines Skiables de France), ADSP (Directeurs de Pistes et de la Sécurité des Stations de Sports d'Hiver) et autres acteurs de la montagne.

Bulletin neige & avalanches par téléphone au 0 892 68 10 20 Service 0,35 € / min + prix appel

RÉPUBLIQUE FRANÇAISE
Liberté Égalité Fraternité

METEO FRANCE
À VOS CÔTÉS, DANS UN CLIMAT QUI CHANGE

Bulletin d'estimation du risque d'avalanche

(valable en dehors des pistes balisées et ouvertes)

MASSIF : Chartreuse

Rédigé le vendredi 6 février 2026 à 16h

Conditions nivo-météo des 7 derniers jours

	sam. 31/01				dim. 01/02				lun. 02/02				mar. 03/02				mer. 04/02				jeu. 05/02				ven. 06/02			
	03h	09h	15h	21h	03h	09h	15h	21h	03h	09h	15h	21h	03h	09h	15h	21h	03h	09h	15h	21h	03h	09h	15h	21h	03h	09h	15h	21h
Météo																												
Vent (km/h)	25	15	20	20	20	20	20	25	30	55	80	110	110	100	95	90	75	55	35	35	35	45	65	50	60	35	30	20
à 2000m																												
Vent (km/h)	15	10	15	10	10	10	10	15	15	35	60	90	90	80	75	70	55	40	25	20	20	20	40	25	30	20	15	10
à 1500m																												

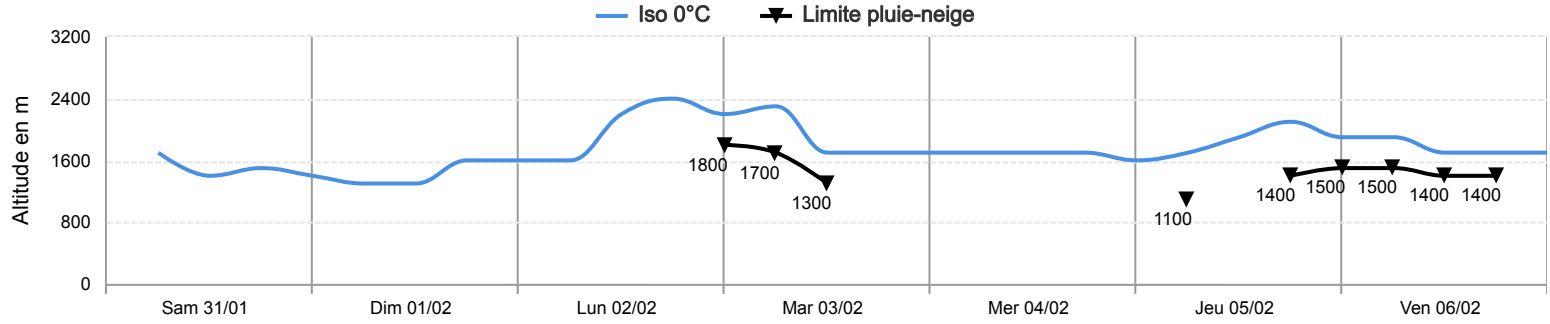

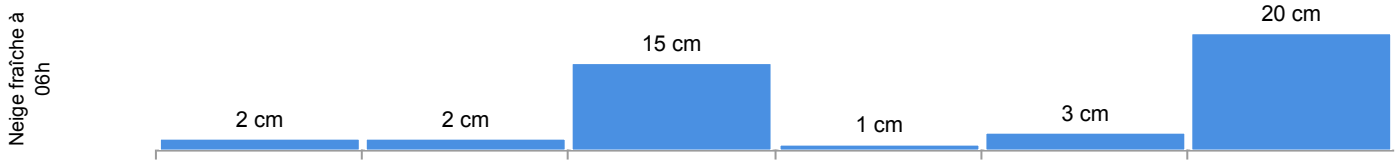

Risque d'avalanche	sam. 31/01	dim. 01/02	lun. 02/02	mar. 03/02	mer. 04/02	jeu. 05/02	ven. 06/02
	2	2	3	3	3	3	3

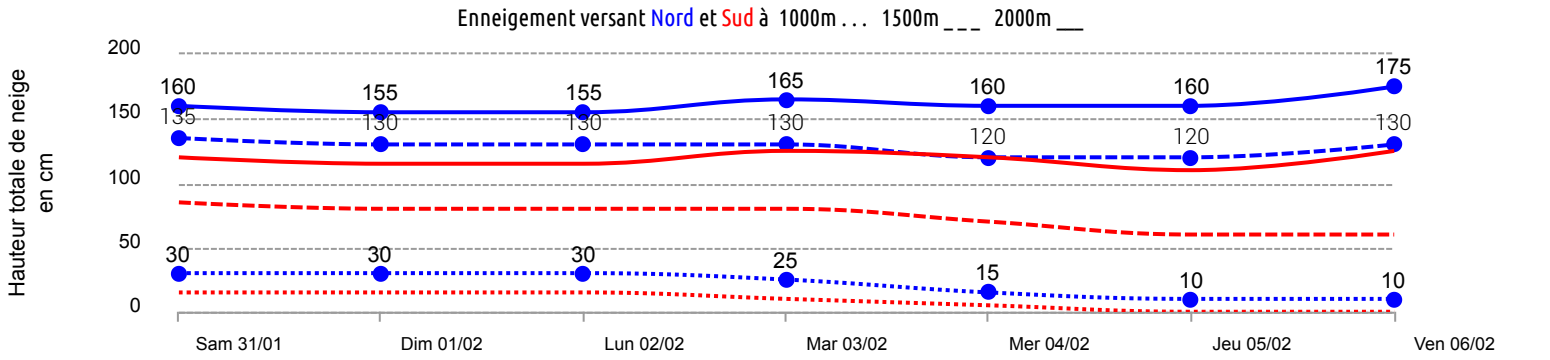

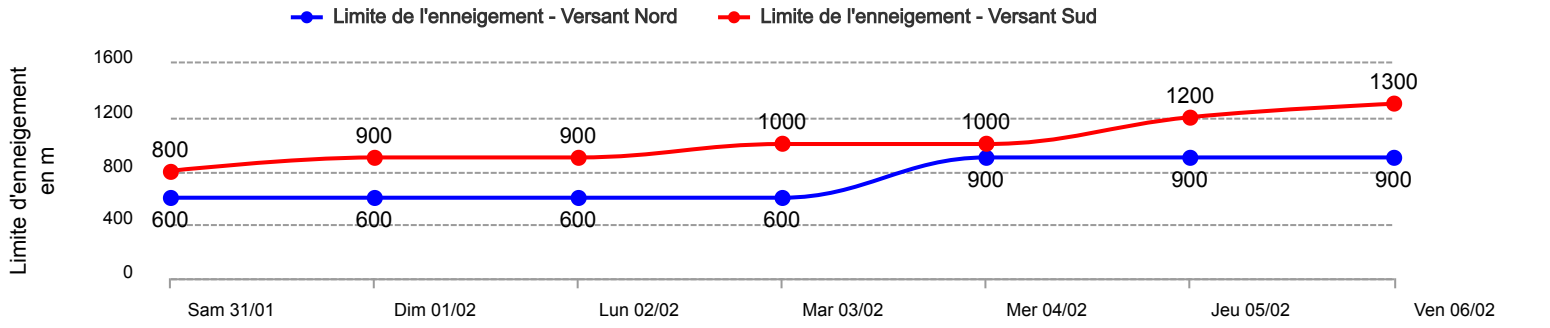

Pour consulter la vigilance en cours, veuillez vous rendre sur le site https://vigilance.meteofrance.fr/fr

Météo-France - 73 avenue de Paris, 94165 Saint-Mandé cedex - Contact : contact@meteo.fr

Rédigé par Météo-France avec la contribution des observateurs du réseau nivo-météorologiques. Partenariat : ANMSM (Maires de Stations de Montagne), DSF (Domaines Skiables de France), ADSP (Directeurs de Pistes et de la Sécurité des Stations de Sports d'Hiver) et autres acteurs de la montagne.

Bulletin neige & avalanches par téléphone au

0 892 68 10 20 Service 0,35 € / min + prix appel