Bulletin d'estimation du risque d'avalanche

(valable en dehors des pistes balisées et ouvertes)

MASSIF : Cinto Rotondo

Rédigé le vendredi 6 février 2026 à 16h

Estimation des risques pour le : SAMEDI 07 FÉVRIER

NOUVELLES CHUTES DE NEIGE AVEC FORMATION DE PLAQUES EN ALTITUDE

3

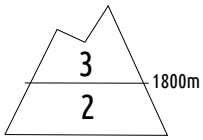

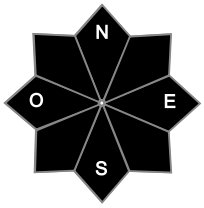

Au-dessus de 1800m indice de risque marqué, plus bas indice limité.

Départs spontanés : Avalanches de neige fraîche

Déclenchements provoqués : Plaques en altitude

Indices de risque : 5 très fort - 4 fort - 3 marqué - 2 limité - 1 faible -- En noir : les pentes les plus dangereuses

Stabilité du manteau neigeux

Situation avalancheuse typique : neige fraîche couche fragile persistante

Déclenchements provoqués : au-dessus de 1800 m, des plaques en place dans l'épaisse couche de neige récente sont présentes en toutes orientations. Ces plaques se situent souvent dans des pentes ombragées, parfois loin des crêtes. De plus, le fort vent d'ouest a formé de nouvelles plaques durant les récentes chutes de neige, principalement dans les pentes orientées Nord à Est. Faciles à déclencher par un seul skieur, toutes plaques pourraient générer des avalanches de taille moyenne à grande. En dessous de 1800 m, les plaques sont plus rares, peu épaisses et généralement plus difficiles à solliciter.

Départs spontanés : les chutes de neige se poursuivent ce samedi. Au fil des heures, la neige s'accumule et des coulée et avalanches sont attendues, parfois de grande taille due aux accumulations. Ces avalanches peuvent également atteindre des pentes peu raides et moins enneigées.

Qualité de la neige

Qualification de l'enneigement : l'enneigement est excellent pour la saison à toutes altitudes, avec des cumuls de neige récente atteignant ponctuellement 40 à 60 cm en moyenne montagne. On relève 2m75 sur la Maniccia à 2350 m dans le massif du Rotondo.

Limite d'enneigement skiable : 1400 à 1500 m.

État de la neige : la neige récente est encore sèche et plutôt légère, localement humidifiée ou croûtée en dessous de 1800 m. Le vent soutenu rend l'enneigement toujours très hétérogène. La neige est froide et poudreuse à l'abri du vent, elle devient plus compacte, voire cartonnée dans les secteurs ventés. Des anciennes surfaces, souvent dures et glacées, réapparaissent près des crêtes.

Aperçu météo pour le samedi 07 février

	nuit	matin	après-midi	soir
Temps perturbé et venteux				
Pluie-Neige		1 400 m	1 400 m	1 300 m
Iso 0 °C	2 100 m	2 200 m	1 800 m	2 000 m
Vent 1500 m	↗ 55 km/h	↗ 30 km/h	→ 45 km/h	→ 35 km/h
Vent 3000 m	↗ 65 km/h	↗ 45 km/h	→ 60 km/h	→ 45 km/h

Épaisseur de neige hors-piste

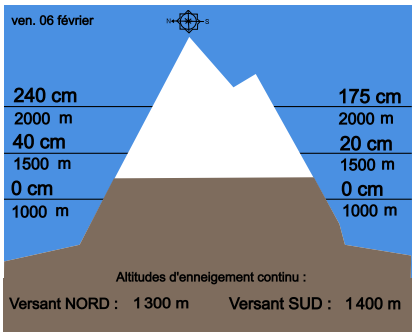

Précipitations à 1800 m

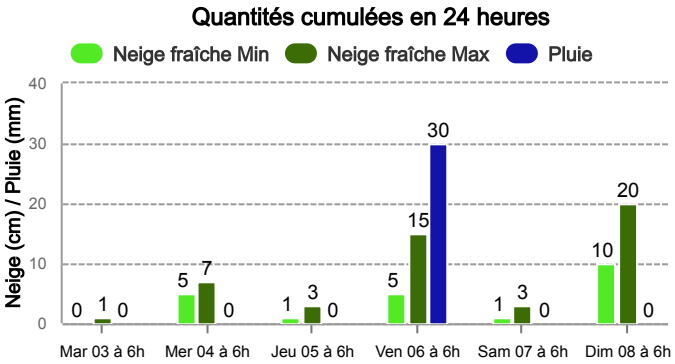

Tendance du dimanche 08 février

3

Indice de risque marqué

Poursuite d'un temps perturbé. Pas d'évolution notable en termes de risque.

Pour consulter la vigilance en cours, veuillez vous rendre sur le site https://vigilance.meteofrance.fr/fr

Météo-France - 73 avenue de Paris, 94165 Saint-Mandé cedex - Contact : contact@meteo.fr

Rédigé par Météo-France avec la contribution des observateurs du réseau nivo-météorologiques. Partenariat : ANMSM (Maires de Stations de Montagne), DSF (Domaines Skiables de France), ADSP (Directeurs de Pistes et de la Sécurité des Stations de Sports d'Hiver) et autres acteurs de la montagne.

Bulletin neige & avalanches par téléphone au

0 892 68 10 20 Service 0,35 € / min + prix appel

RÉPUBLIQUE FRANÇAISE
Liberté Égalité Fraternité

METEO FRANCE
À VOS CÔTÉS, DANS UN CLIMAT QUI CHANGE

Bulletin d'estimation du risque d'avalanche

(valable en dehors des pistes balisées et ouvertes)

MASSIF : Cinto Rotondo

Rédigé le vendredi 6 février 2026 à 16h

Conditions nivo-météo des 7 derniers jours

	sam. 31/01				dim. 01/02				lun. 02/02				mar. 03/02				mer. 04/02				jeu. 05/02				ven. 06/02			
	03h	09h	15h	21h	03h	09h	15h	21h	03h	09h	15h	21h	03h	09h	15h	21h	03h	09h	15h	21h	03h	09h	15h	21h	03h	09h	15h	21h
Météo																												
Vent (km/h)	50	25	30	20	25	20	30	40	50	40	40	50	60	60	35	20	15	60	50	20	35	50	45	65	100	85	80	65
à 3000m																												
Vent (km/h)	30	30	25	15	25	15	15	15	30	20	20	25	40	50	30	15	15	30	25	15	25	35	30	50	80	70	70	55
à 1500m																												

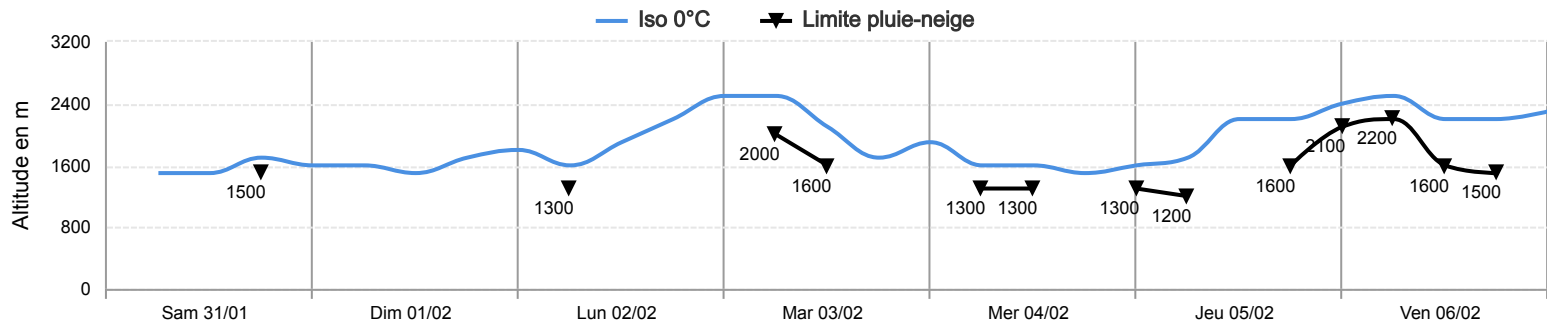

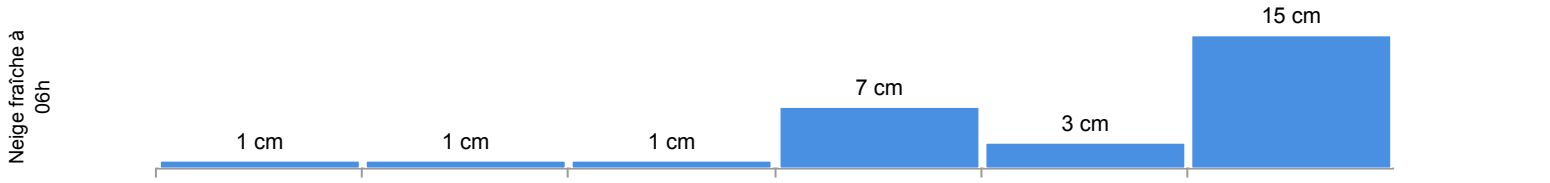

Risque d'avalanche	sam. 31/01	dim. 01/02	lun. 02/02	mar. 03/02	mer. 04/02	jeu. 05/02	ven. 06/02
	3	3	3	3	3	3	3

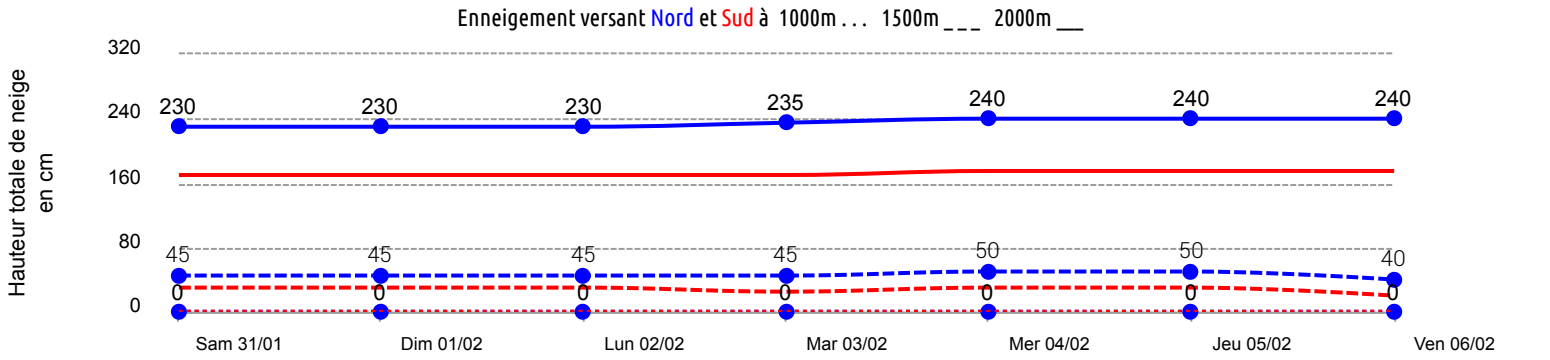

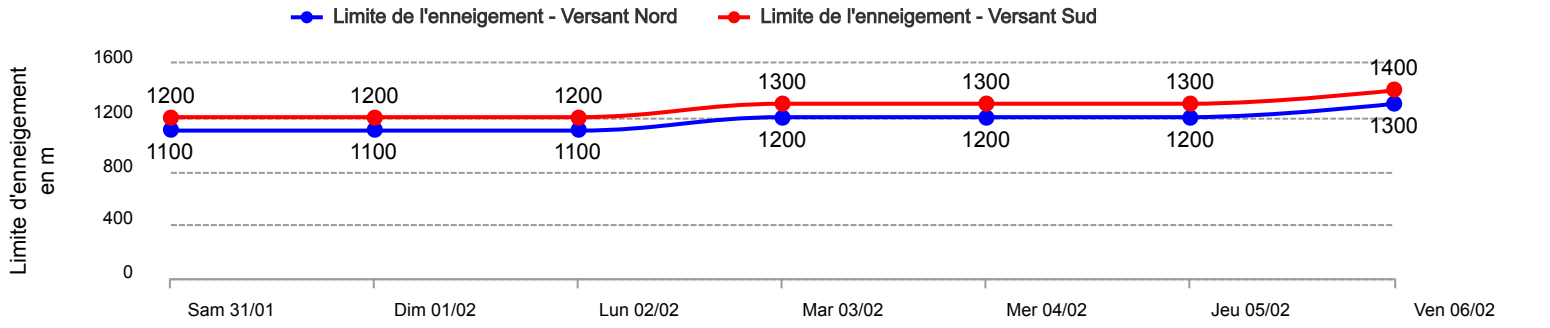

Pour consulter la vigilance en cours, veuillez vous rendre sur le site https://vigilance.meteofrance.fr/fr

Météo-France - 73 avenue de Paris, 94165 Saint-Mandé cedex - Contact : contact@meteo.fr

Rédigé par Météo-France avec la contribution des observateurs du réseau nivo-météorologiques. Partenariat : ANMSM (Maires de Stations de Montagne), DSF (Domaines Skiables de France), ADSP (Directeurs de Pistes et de la Sécurité des Stations de Sports d'Hiver) et autres acteurs de la montagne.

Bulletin neige & avalanches par téléphone au
0 892 68 10 20 Service 0,35 € / min + prix appel