RÉPUBLIQUE FRANÇAISE
Liberté Égalité Fraternité

METEO FRANCE
À VOS CÔTÉS, DANS UN CLIMAT QUI CHANGE

Bulletin d'estimation du risque d'avalanche
(valable en dehors des pistes balisées et ouvertes)
MASSIF : Grandes-Rousses

Rédigé le vendredi 6 février 2026 à 16h

Estimation des risques pour le : SAMEDI 07 FÉVRIER

PRÉSENCE DE PLAQUES FRIABLES DANS LA NEIGE RÉCENTE.

3

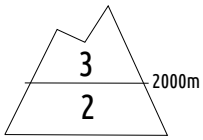

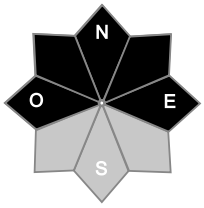

Au-dessus de 2000m indice de risque marqué, plus bas indice limité.

Départs spontanés : Rares purges de neige récente au soleil.

Déclenchements provoqués : Couche de neige récente encore mal stabilisée.

Indices de risque : 5 très fort - 4 fort - 3 marqué - 2 limité - 1 faible -- En noir : les pentes les plus dangereuses

Stabilité du manteau neigeux

Situation avalancheuse typique : neige ventée couche fragile persistante

Le manteau neigeux a subi une humidification significative et un tassement important en dessous de 2000/2200 m selon les versants, consolidant efficacement les dernières chutes de neige. A plus haute altitude, la neige sèche est encore insuffisamment stabilisée.

Déclenchements provoqués : les plaques d'aspect poudreux formées très récemment sont en cours de stabilisation, mais restent encore réactives au passage d'un skieur. Plusieurs observations indiquent des déclenchements faciles de plaques d'ampleur limitée (taille 1 à 2 avec des cassures de 20/40 cm), mais avec des propagations à distance Le risque est surtout présent en versants froids à plus de 2000 m. Ponctuellement, il est toujours possible qu'une avalanche sollicite une couche fragile enfouie plus profondément dans le manteau neigeux lors de son trajet, entraînant alors des volumes de neige bien plus conséquents.

Départs spontanés : de nombreuses purges de taille 1, plus rarement 2, se sont déjà produites ce vendredi. L'activité avalancheuse naturelle s'annonce plus modeste samedi avec seulement quelques départs spontanés de neige humide en pentes raides encore vierges.

Qualité de la neige

Qualification de l'enneigement : l'enneigement est bon pour la saison, sauf aux altitudes les plus basses.

Limites skiables : vers 1100/1400 m.

Qualité de la neige samedi : En dessous de 2000 m et dans les versants au soleil, neige humidifiée en surface, croûtée en début de journée. Dans les ubacs à plus de 2000 m, petite couche de neige récente, parfois soufflée.

Aperçu météo pour le samedi 07 février

	nuit	matin	après-midi	soir
Pluie-Neige				
Iso 0 °C	1 700 m	1 800 m	1 800 m	1 700 m
Vent 2000 m	5 km/h	10 km/h	10 km/h	5 km/h
Vent 3000 m	20 km/h	10 km/h	10 km/h	10 km/h

Épaisseur de neige hors-piste

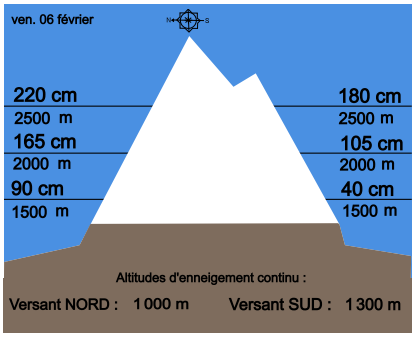

Précipitations à 1800 m

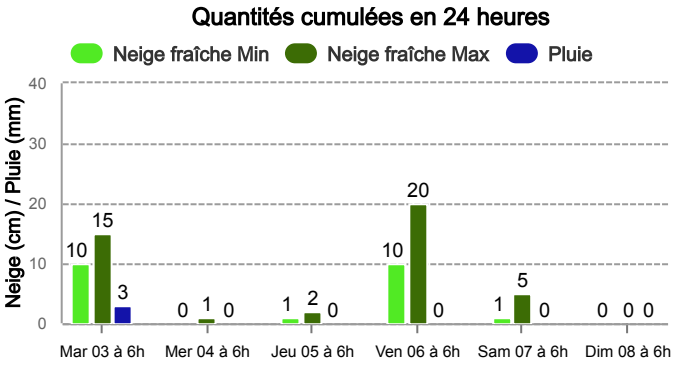

Tendance du dimanche 08 février

3

Indice de risque marqué

Dimanche, poursuite de la stabilisation du manteau neigeux. Risques en baisse.

Pour consulter la vigilance en cours, veuillez vous rendre sur le site https://vigilance.meteofrance.fr/fr

Météo-France - 73 avenue de Paris, 94165 Saint-Mandé cedex - Contact : contact@meteo.fr

Rédigé par Météo-France avec la contribution des observateurs du réseau nivo-météorologiques. Partenariat : ANMSM (Maires de Stations de Montagne), DSF (Domaines Skiables de France), ADSP (Directeurs de Pistes et de la Sécurité des Stations de Sports d'Hiver) et autres acteurs de la montagne.

Bulletin neige & avalanches par téléphone au
0 892 68 10 20 Service 0,35 € / min + prix appel

RÉPUBLIQUE FRANÇAISE
Liberté Égalité Fraternité

METEO FRANCE
À VOS CÔTÉS, DANS UN CLIMAT QUI CHANGE

Bulletin d'estimation du risque d'avalanche

(valable en dehors des pistes balisées et ouvertes)

MASSIF : Grandes-Rousses

Rédigé le vendredi 6 février 2026 à 16h

Conditions nivo-météo des 7 derniers jours

	sam. 31/01				dim. 01/02				lun. 02/02				mar. 03/02				mer. 04/02				jeu. 05/02				ven. 06/02			
	03h	09h	15h	21h	03h	09h	15h	21h	03h	09h	15h	21h	03h	09h	15h	21h	03h	09h	15h	21h	03h	09h	15h	21h	03h	09h	15h	21h
Météo																												
Vent (km/h)	20	15	20	15	20	20	20	20	25	40	65	105	100	95	80	65	35	35	35	25	25	45	45	45	45	30	25	20
à 3000m																												
Vent (km/h)	10	10	15	10	10	10	10	10	15	25	50	90	80	75	60	35	25	30	20	10	15	30	30	30	20	20	20	10
à 2000m																												

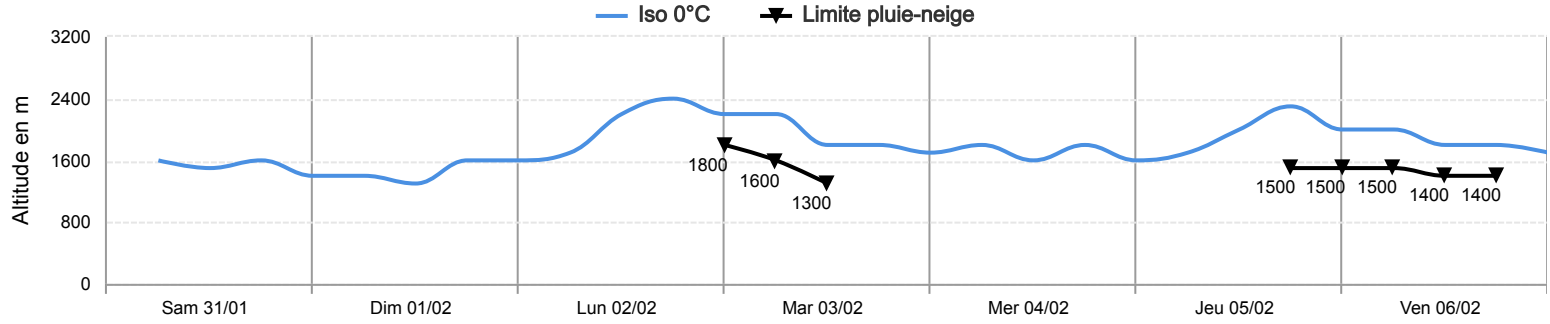

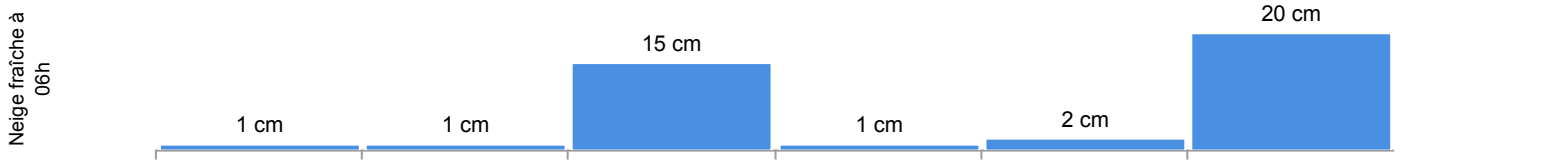

Risque d'avalanche	sam. 31/01	dim. 01/02	lun. 02/02	mar. 03/02	mer. 04/02	jeu. 05/02	ven. 06/02
	3	3	3	4	4	3	3

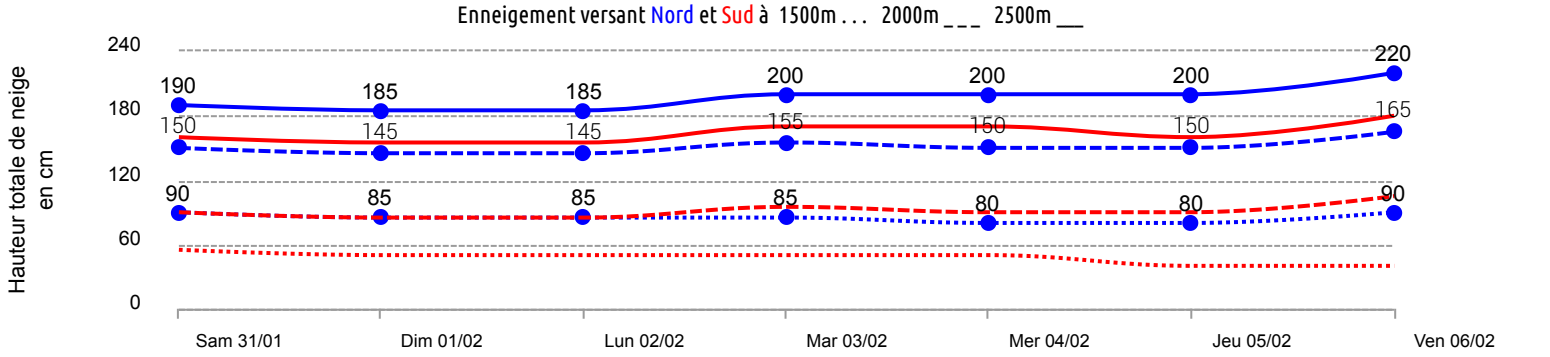

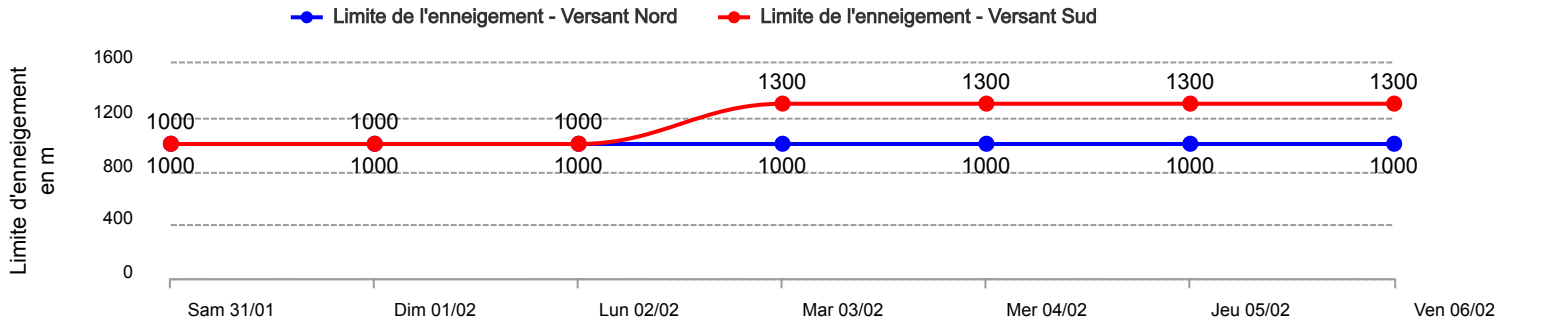

Pour consulter la vigilance en cours, veuillez vous rendre sur le site https://vigilance.meteofrance.fr/fr

Météo-France - 73 avenue de Paris, 94165 Saint-Mandé cedex - Contact : contact@meteo.fr

Rédigé par Météo-France avec la contribution des observateurs du réseau nivo-météorologiques. Partenariat : ANMSM (Maires de Stations de Montagne), DSF (Domaines Skiables de France), ADSP (Directeurs de Pistes et de la Sécurité des Stations de Sports d'Hiver) et autres acteurs de la montagne.

Bulletin neige & avalanches par téléphone au
0 892 68 10 20 Service 0,35 € / min + prix appel