Bulletin d'estimation du risque d'avalanche
(valable en dehors des pistes balisées et ouvertes)

MASSIF : Haut-Var Haut-Verdon

Rédigé le vendredi 6 février 2026 à 16h

Estimation des risques pour le : SAMEDI 07 FÉVRIER

RISQUE MARQUÉ DÉCLENCHEMENT SKIEUR EN ALTITUDE . INSTABILITÉS, LOCALEMENT VOLUMINEUSES.

3

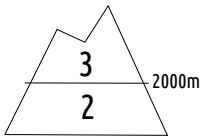

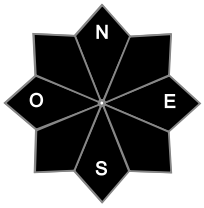

Au-dessus de 2000m indice de risque marqué, plus bas indice limité.

Départs spontanés : éventuels départs ponctuels superficiels en neige humide

Déclenchements provoqués : Plaques surtout en altitude. Faciles à déclencher, parfois à distance.

Indices de risque : 5 très fort - 4 fort - 3 marqué - 2 limité - 1 faible -- En noir : les pentes les plus dangereuses

Stabilité du manteau neigeux

Situation avalancheuse typique : neige fraîche couche fragile persistante

Déclenchements provoqués : principalement au-dessus de 2000 m environ, instabilités possiblement présentes en toute orientation. Elles peuvent être difficiles à détecter car d'aspect poudreux, sinon durcies par le vent dans les secteurs exposés. Déclenchement encore facile par un skieur ou randonneur, parfois à distance, engendrant généralement une avalanche de plaque de taille petite à moyenne dans la neige fraiche/récente. Toutefois, en versants est, nord et ouest, possibles avalanches de plaque de grande taille emportant une grande partie du manteau neigeux, parfois sur de grandes distances. Toutefois, leur déclenchement semble plus difficile car dans ces orientations la couche fragile persistante est souvent enfouie. Sollicitation plutôt sous une forte contrainte comme le déclenchement d'une première avalanche en surface.
Sous 2000 m, le risque de déclenchement est plus limité.

Départs spontanés : en journée de samedi, en pente raide ensoleillée, éventuels départs ponctuels en neige humide, généralement de petite taille, voire moyenne. Pouvant très localement, déclencher une plaque par surcharge.

Qualité de la neige

Enneigement bon voire excédentaire jusqu'à basse altitude pour un début février.
Données observées vers 2000 m en fond de vallon : 150 à 170 cm.

Enneigement skiable dès 1300/1400 m en terrain favorable, mais peu de sous-couche sous 1600 m en général.

État de la neige en surface : neige croutée en adrets jusque vers 2200/2400 m, plus bas en ubacs, s'humidifiant en journée. Sinon neige fraiche/récente en quantité, poudreuse, localement densifiée par le vent. Corniches et congères parfois volumineuses en place.

Aperçu météo pour le samedi 07 février

nuit	matin	après-midi	soir
S'ennuageant en journée. Vent faible.			

Pluie-Neige				
Iso 0 °C	1 900 m	1 800 m	1 700 m	1 800 m
Vent 2000 m	20 km/h	10 km/h	10 km/h	10 km/h
Vent 3000 m	35 km/h	15 km/h	15 km/h	10 km/h

Épaisseur de neige hors-piste

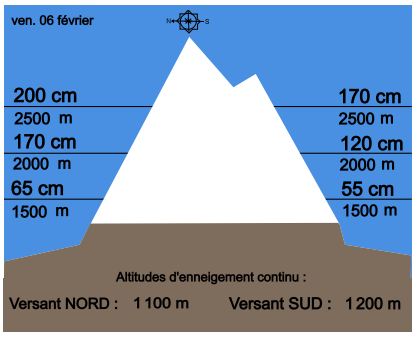

Précipitations à 1800 m

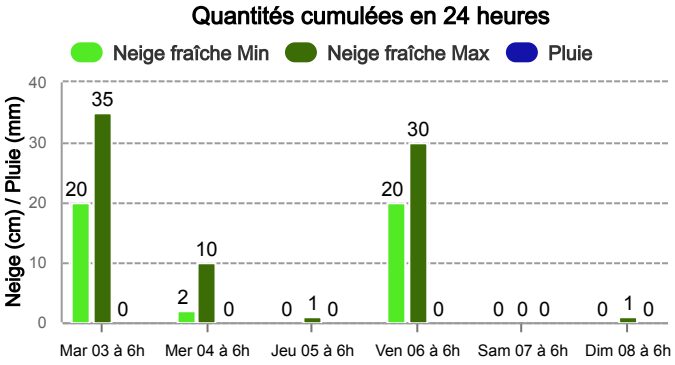

Tendance du dimanche 08 février

3 **Indice de risque marqué**

Instabilités encore faciles à déclencher.
Risque Marqué.

Pour consulter la vigilance en cours, veuillez vous rendre sur le site https://vigilance.meteofrance.fr/fr

Météo-France - 73 avenue de Paris, 94165 Saint-Mandé cedex - Contact : contact@meteo.fr

Rédigé par Météo-France avec la contribution des observateurs du réseau nivo-météorologiques. Partenariat : ANMSM (Maires de Stations de Montagne), DSF (Domaines Skiables de France), ADSP (Directeurs de Pistes et de la Sécurité des Stations de Sports d'Hiver) et autres acteurs de la montagne.

Bulletin neige & avalanches par téléphone au
0 892 68 10 20 Service 0,35 € / min + prix appel

RÉPUBLIQUE FRANÇAISE
Liberté Égalité Fraternité

METEO FRANCE
À VOS CÔTÉS, DANS UN CLIMAT QUI CHANGE

Bulletin d'estimation du risque d'avalanche

(valable en dehors des pistes balisées et ouvertes)

MASSIF : Haut-Var Haut-Verdon

Rédigé le vendredi 6 février 2026 à 16h

Conditions nivo-météo des 7 derniers jours

	sam. 31/01				dim. 01/02				lun. 02/02				mar. 03/02				mer. 04/02				jeu. 05/02				ven. 06/02			
	03h	09h	15h	21h	03h	09h	15h	21h	03h	09h	15h	21h	03h	09h	15h	21h	03h	09h	15h	21h	03h	09h	15h	21h	03h	09h	15h	21h
Météo																												
Vent (km/h)	20	20	20	15	20	15	15	15	20	25	40	65	75	50	35	20	25	25	25	20	35	30	40	50	50	45	45	30
à 3000m	←	←	↘	↘	↘	↓	↘	↘	↘	↑	↖	↖	↑	↑	↑	↖	↖	↖	↖	↘	↘	↘	↗	↑	↘	↘	↘	↘
Vent (km/h)	15	15	15	15	10	10	15	10	10	10	20	30	35	30	20	15	15	20	20	10	15	15	20	20	25	35	35	20
à 2000m	←	↙	↘	↘	↓	↗	↓	↓	↘	→	↖	↖	↖	↑	↑	↖	←	↖	↖	↙	↘	→	↑	←	←	↘	↘	↘

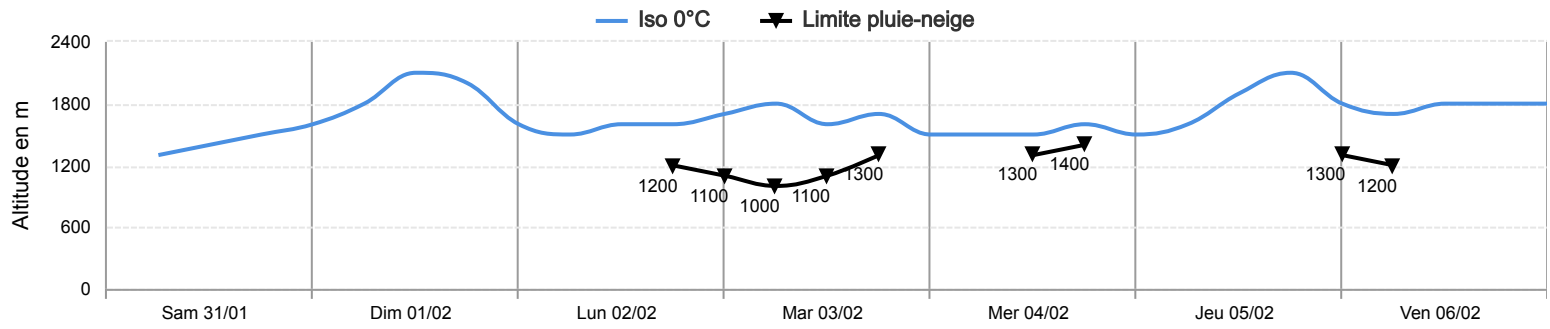

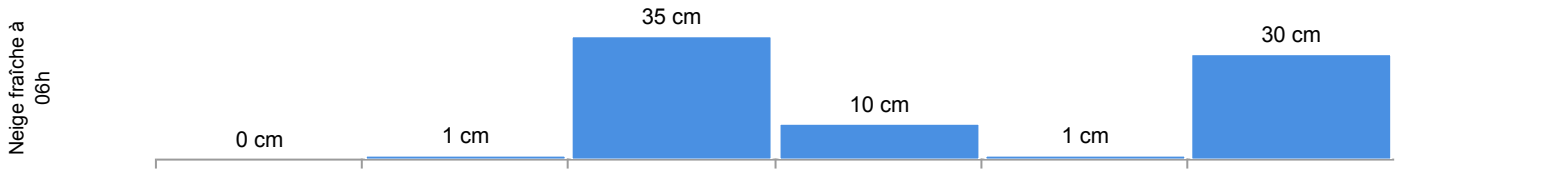

Risque d'avalanche	sam. 31/01	dim. 01/02	lun. 02/02	mar. 03/02	mer. 04/02	jeu. 05/02	ven. 06/02
	3	3	3	4	3	3	4

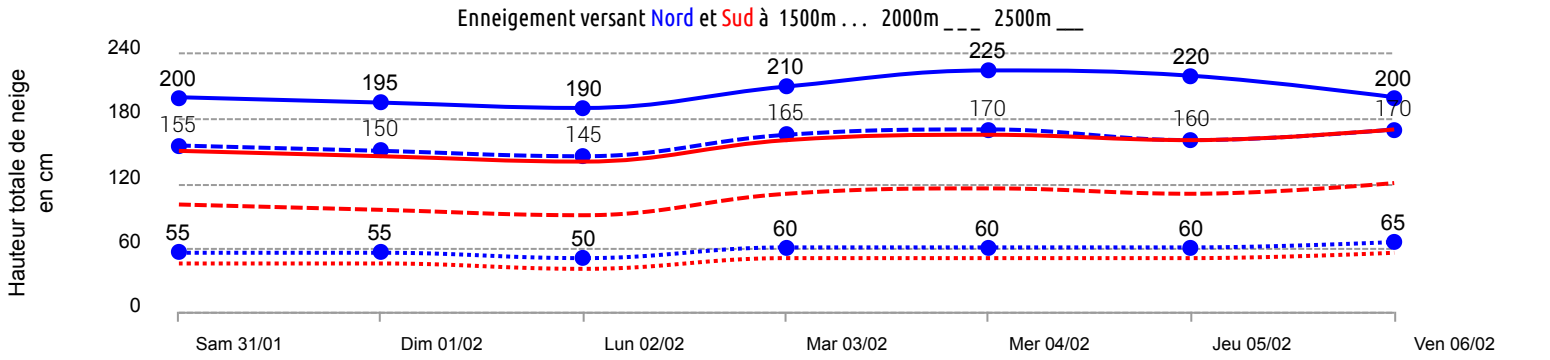

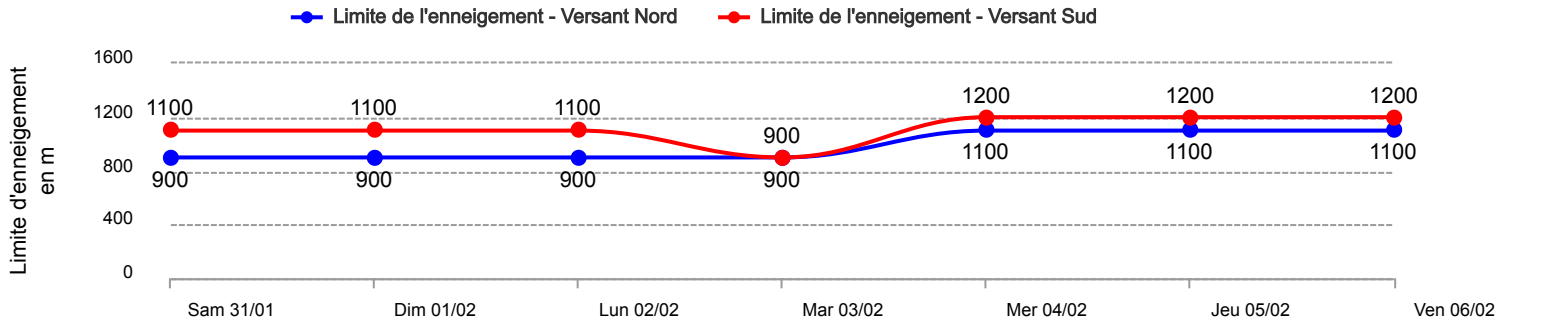

Pour consulter la vigilance en cours, veuillez vous rendre sur le site https://vigilance.meteofrance.fr/fr

Météo-France - 73 avenue de Paris, 94165 Saint-Mandé cedex - Contact : contact@meteo.fr

Rédigé par Météo-France avec la contribution des observateurs du réseau nivo-météorologiques. Partenariat : ANMSM (Maires de Stations de Montagne), DSF (Domaines Skiables de France), ADSP (Directeurs de Pistes et de la Sécurité des Stations de Sports d'Hiver) et autres acteurs de la montagne.

Bulletin neige & avalanches par téléphone au

0 892 68 10 20 Service 0,35 € / min + prix appel