Bulletin d'estimation du risque d'avalanche
(valable en dehors des pistes balisées et ouvertes)

MASSIF : Haute-Tarentaise

Rédigé le vendredi 6 février 2026 à 16h

Estimation des risques pour le : SAMEDI 07 FÉVRIER

NOMBREUSES PLAQUES D'ASPECT POUDREUX. GRANDES AVALANCHES TOUJOURS POSSIBLES.

3

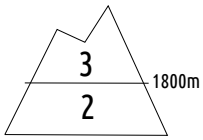

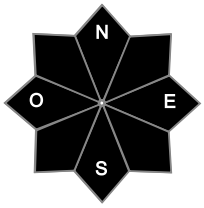

Au-dessus de 1800m indice de risque marqué, plus bas indice limité.

Départs spontanés : départs ponctuels ou linéaires au gré des éclaircies.

Déclenchements provoqués : nombreuses plaques poudreuses. Grandes avalanches possibles.

Indices de risque : 5 très fort - 4 fort - 3 marqué - 2 limité - 1 faible -- En noir : les pentes les plus dangereuses

Stabilité du manteau neigeux

Situation avalancheuse typique : neige fraîche couche fragile persistante

Déclenchements provoqués : de nombreuses **plaques friables d'aspect poudreux** sont en place près des crêtes comme dans les pentes. Elles restent réactives en journée dans les versants Est, Nord et Ouest, et vivent leur dernières heures dans les versants ensoleillés (Sud Est à Sud Ouest). Elles occasionnent des cassures de ~30 cm et des avalanches de taille 1 à 2 (petite à moyenne) - plus épaisses et plus grosses en haute montagne. **Observables :** accumulation de neige fraiche supérieure à la moyenne environnante, neige dense en surface et plus molle en dessous, fissures devant les skis.
Facteur aggravant, au dessus de 1800m et en versants froids (Est/Nord/Ouest) mais **aussi en Sud à haute altitude, des couches fragiles persistantes enfouies** dans le manteau pourront réagir au passage d'un skieur ou en cascade grâce aux plaques friables. Elles **engendrent de plus grandes et larges avalanches : taille 3**
Observables : woumfs en ce qui concerne les couches fragiles persistantes enfouies.

Départs spontanés : au gré de la course du Soleil, des départs ponctuels (avalanches en poire) ou linéaires (cassures) s'observent dans les pentes raides d'altitude, au départ des rochers. Taille 1, au pire 2 si la topographie s'y prête.

Qualité de la neige

Enneigement : un peu en dessous des normales de saison mais les chutes à venir (dans la semaine) devraient améliorer nettement l'enneigement

Limite skiable : dans les secteurs soumis au foehn les limites skiables sont remontées au delà de 1600m en Sud. A l'abri du foehn on peut encore chausser localement en Nord vers 1000/1100m .

Qualité de la neige : au réveil, la neige récente est croutée jusqu'à ~1800 m ? Encore plus haut, elle est poudreuse sur ~15 cm, travaillée par le vent à l'approche des crêtes. Dans les versants "chauds" (Sud Est à Sud Ouest), elle chauffe au gré de la course du Soleil : à basse altitude, la croute ramollie. Plus haut, la neige se met à coller. Gare au bottage !

Aperçu météo pour le samedi 07 février

	nuit	matin	après-midi	soir
Beau à voilé.				
Pluie-Neige				
Iso 0 °C	1 600 m	1 800 m	1 900 m	1 600 m
Vent 2500 m	→ 5 km/h	5 km/h	↗ 5 km/h	5 km/h
Vent 3500 m	→ 15 km/h	↗ 15 km/h	↗ 15 km/h	↗ 15 km/h

Épaisseur de neige hors-piste

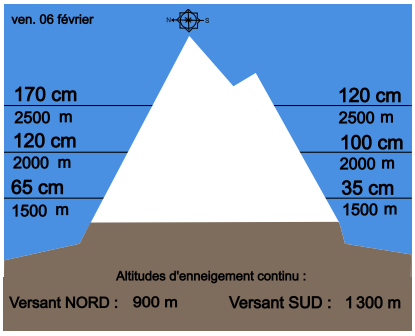

Précipitations à 1800 m

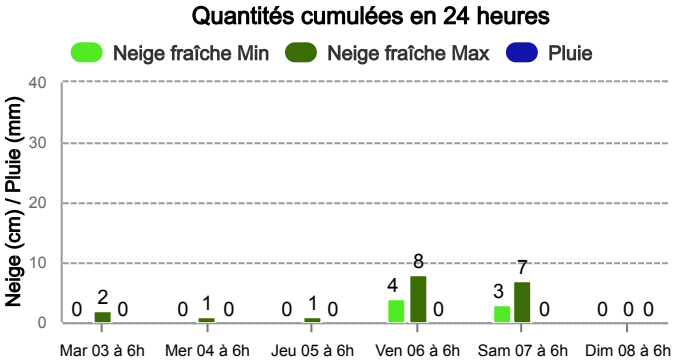

Tendance du dimanche 08 février

3

Indice de risque marqué

Les plaques "de surface" se stabilisent. Les couches fragiles persistantes enfouies demeurent problématiques.

Pour consulter la vigilance en cours, veuillez vous rendre sur le site https://vigilance.meteofrance.fr/fr

Météo-France - 73 avenue de Paris, 94165 Saint-Mandé cedex - Contact : contact@meteo.fr

Rédigé par Météo-France avec la contribution des observateurs du réseau nivo-météorologiques. Partenariat : ANMSM (Maires de Stations de Montagne), DSF (Domaines Skiables de France), ADSP (Directeurs de Pistes et de la Sécurité des Stations de Sports d'Hiver) et autres acteurs de la montagne.

Bulletin neige & avalanches par téléphone au **0 892 68 10 20** Service 0,35 € / min + prix appel

RÉPUBLIQUE FRANÇAISE
Liberté Égalité Fraternité

METEO FRANCE
À VOS CÔTÉS, DANS UN CLIMAT QUI CHANGE

Bulletin d'estimation du risque d'avalanche

(valable en dehors des pistes balisées et ouvertes)

MASSIF : Haute-Tarentaise

Rédigé le vendredi 6 février 2026 à 16h

Conditions nivo-météo des 7 derniers jours

	sam. 31/01				dim. 01/02				lun. 02/02				mar. 03/02				mer. 04/02				jeu. 05/02				ven. 06/02			
	03h	09h	15h	21h	03h	09h	15h	21h	03h	09h	15h	21h	03h	09h	15h	21h	03h	09h	15h	21h	03h	09h	15h	21h	03h	09h	15h	21h
Météo																												
Vent (km/h)	30	20	20	20	20	20	30	30	40	45	60	85	90	75	50	50	55	30	30	35	35	35	40	40	40	45	45	20
à 3500m																												
Vent (km/h)	10	10	10	10	10	10	10	10	10	25	45	70	75	55	35	25	35	30	20	10	15	20	25	30	30	35	35	15
à 2500m																												

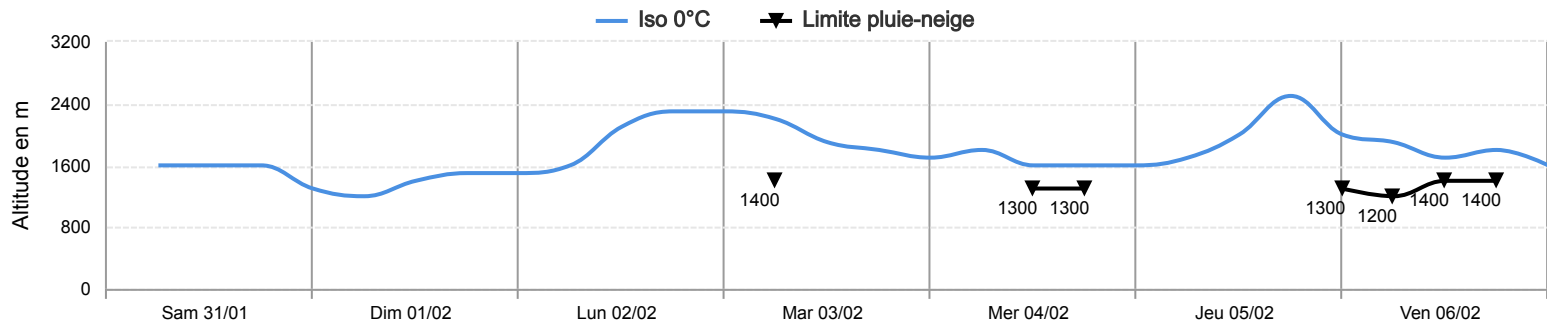

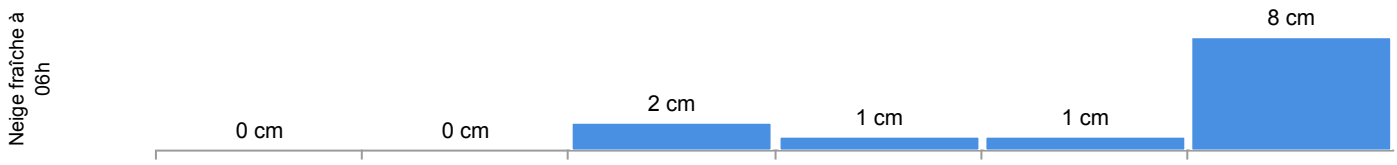

Risque d'avalanche	sam. 31/01	dim. 01/02	lun. 02/02	mar. 03/02	mer. 04/02	jeu. 05/02	ven. 06/02
	3	3	3	3	3	3	3

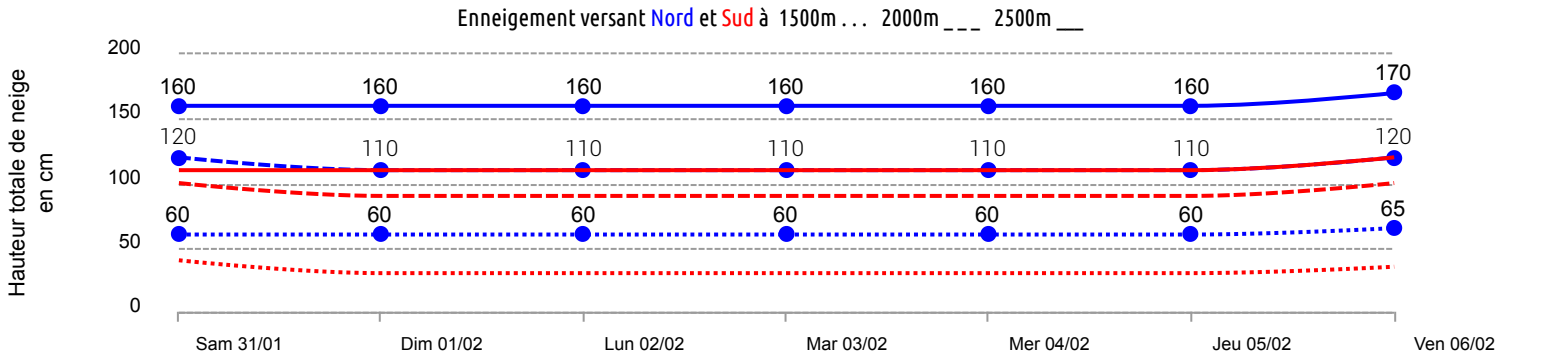

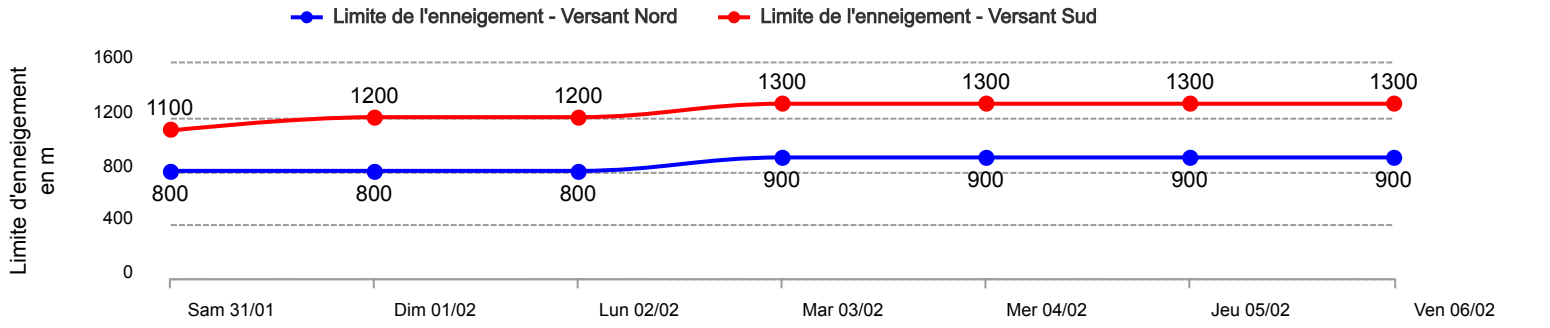

Pour consulter la vigilance en cours, veuillez vous rendre sur le site https://vigilance.meteofrance.fr/fr

Météo-France - 73 avenue de Paris, 94165 Saint-Mandé cedex - Contact : contact@meteo.fr

Rédigé par Météo-France avec la contribution des observateurs du réseau nivo-météorologiques. Partenariat : ANMSM (Maires de Stations de Montagne), DSF (Domaines Skiables de France), ADSP (Directeurs de Pistes et de la Sécurité des Stations de Sports d'Hiver) et autres acteurs de la montagne.

Bulletin neige & avalanches par téléphone au

0 892 68 10 20 Service 0,35 € / min + prix appel