Bulletin d'estimation du risque d'avalanche

(valable en dehors des pistes balisées et ouvertes)

MASSIF : Luchonnais

Rédigé le vendredi 6 février 2026 à 16h

Estimation des risques pour le : SAMEDI 07 FÉVRIER

NEIGE VENTEE EN ALTITUDE, HUMIDIFICATION LENTE PLUS BAS.

2

2

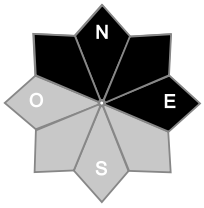

Neige ventée.

Indice de risque limité.

Départs spontanés : Ponctuels en neige humide, cassures linéaires en neige ventée.

Déclenchements provoqués : Plaques instables au-dessus de 2000m en nord à est.

Indices de risque : 5 très fort - 4 fort - 3 marqué - 2 limité - 1 faible -- En noir : les pentes les plus dangereuses

Stabilité du manteau neigeux

Situation avalancheuse typique : neige humide neige ventée

Déclenchements provoqués : Plaques **formées loin des crêtes, cols et sommets** dans les secteurs déventés Nord-à Est, déclenchables par **faible sollicitation sur le haut du massif. Avalanches possibles de taille 1, localement de taille 2.**
Mais en de rares secteurs frontaliers : **Avalanches de taille 3 possibles:** si déclenchement d'une plaque initiant une avalanche de taille 2, celle-ci peut entraîner des couches épaisses et anciennes plus difficilement déclenchables en contrebas et **abonder l'avalanche initiale**.
Dans tous les autres secteurs et sous 2000 m, neige moins travaillée par le vent, quelques plaques s'humidifiant en journée, devenant plus difficilement déclenchables.
Manteau humidifié jusqu'à 1900 m jeudi puis quelques plaques formées au-dessus de 1600 m en après-midi en secteurs Nord à Est.

Départs spontanés : départs **fréquents en pentes raides.**
- **en neige sèche dans les versants Nord à Est** : En secteurs Nord à Nord-Est déventés : surtout en secteur frontalier, avalanches de taille petites à moyenne en départs **ponctuels au-dessus de 1900 à 2100 m**, de même rares **cassures linéaires** souvent de **petite taille (1) à moyennes (2).**
- **en neige humide** : En versants ensoleillés, l'humidification peut déclencher des départs ponctuels de neige alourdie ou d'avalanche de fond de taille 1 à 2 en journée, rarement de taille 3 par emport de la totalité du manteau neigeux (avalanches de fond en tous secteurs et moments), préférentiellement en versants ensoleillés ou sous 2000 m en toutes orientations.

Qualité de la neige

Enneigement : Correct pour la saison, mais les crêtes, cols et sommets sont souvent pelés par le vent dans les expositions ouest. Le manteau neigeux s'humidifie en journée sous 2000 m ou avec les éclaircies. Accumulations plus importantes en secteurs frontaliers.
Limites skiables : manteau neigeux skiable à partir de 1500 /1600 m avec sous couche portante.
État de la neige : neige récente avec croûte parfois portante au petit matin. Neige qui se ramollit en surface par l'humidification en journée samedi sous 2000 m ou en versants ensoleillés. Neige très frittée près des cols, crêtes et sommets de haute montagne. Peu d'évolution en journée du manteau neigeux en ombrée au-dessus de 2000 m.

Aperçu météo pour le samedi 07 février

Ciel peu nuageux, quelques nuages frontaliers, voilé en après-midi, nuageux en soirée et la nuit suivante avec quelques faibles précipitations.

	nuit	matin	après-midi	soir
Pluie-Neige	1 300 m			1 300 m
Iso 0 °C	1 400 m	1 700 m	1 600 m	1 600 m
Vent 2000 m	30 km/h	10 km/h	20 km/h	15 km/h
Vent 3000 m	40 km/h	40 km/h	40 km/h	50 km/h

Épaisseur de neige hors-piste

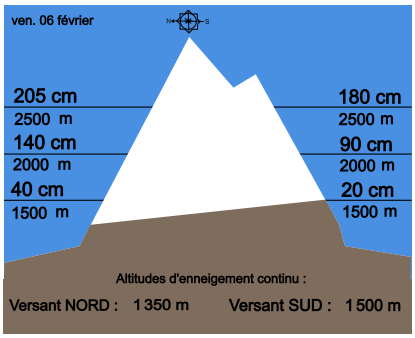

Précipitations à 1800 m

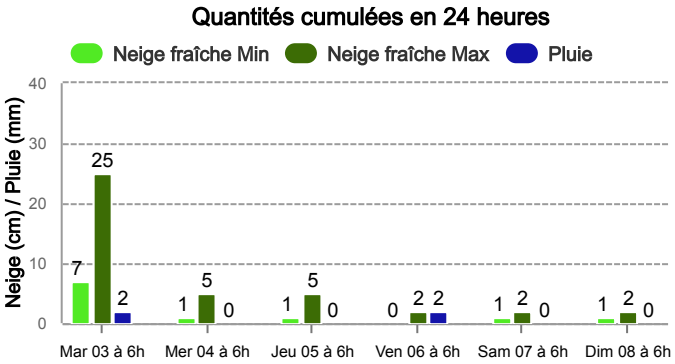

Tendance du dimanche 08 février

2

Indice de risque limité

Quelques plaques en formation.

Pour consulter la vigilance en cours, veuillez vous rendre sur le site https://vigilance.meteofrance.fr/fr

Météo-France - 73 avenue de Paris, 94165 Saint-Mandé cedex - Contact : contact@meteo.fr

Rédigé par Météo-France avec la contribution des observateurs du réseau nivo-météorologiques. Partenariat : ANMSM (Maires de Stations de Montagne), DSF (Domaines Skiables de France), ADSP (Directeurs de Pistes et de la Sécurité des Stations de Sports d'Hiver) et autres acteurs de la montagne.

Bulletin neige & avalanches par téléphone au 0 892 68 10 20 Service 0,35 € / min + prix appel

RÉPUBLIQUE FRANÇAISE
Liberté Égalité Fraternité

METEO FRANCE
À VOS CÔTÉS, DANS UN CLIMAT QUI CHANGE

Bulletin d'estimation du risque d'avalanche

(valable en dehors des pistes balisées et ouvertes)

MASSIF : Luchonnais

Rédigé le vendredi 6 février 2026 à 16h

Conditions nivo-météo des 7 derniers jours

	sam. 31/01				dim. 01/02				lun. 02/02				mar. 03/02				mer. 04/02				jeu. 05/02				ven. 06/02			
	03h	09h	15h	21h	03h	09h	15h	21h	03h	09h	15h	21h	03h	09h	15h	21h	03h	09h	15h	21h	03h	09h	15h	21h	03h	09h	15h	21h
Météo																												
Vent (km/h)	100	100	100	70	40	40	45	50	70	125	120	80	55	45	40	90	95	100	60	55	75	130	95	70	70	70	60	50
à 3000m																												
Vent (km/h)	60	60	70	40	20	20	20	35	50	95	95	50	35	40	30	60	70	55	25	25	55	100	75	55	50	55	45	30
à 2000m																												

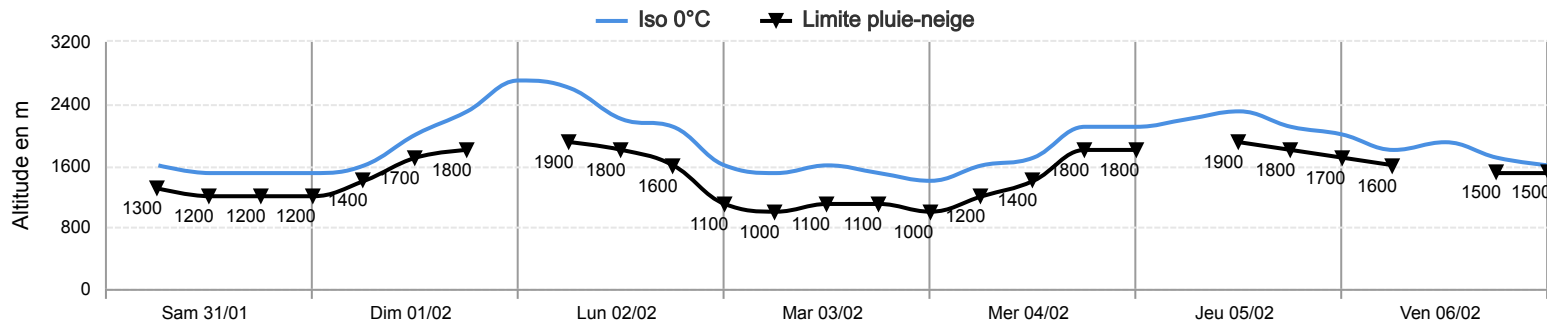

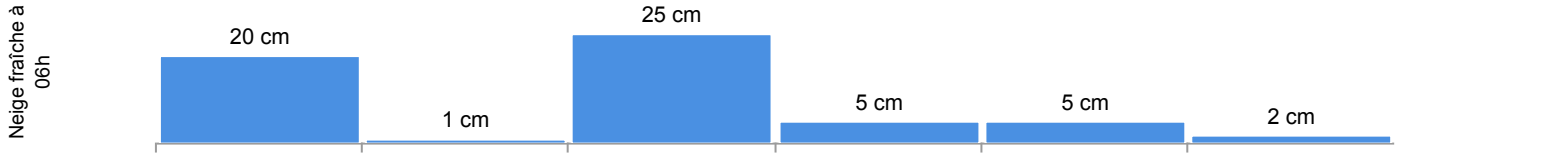

Risque d'avalanche							
	sam. 31/01	dim. 01/02	lun. 02/02	mar. 03/02	mer. 04/02	jeu. 05/02	ven. 06/02

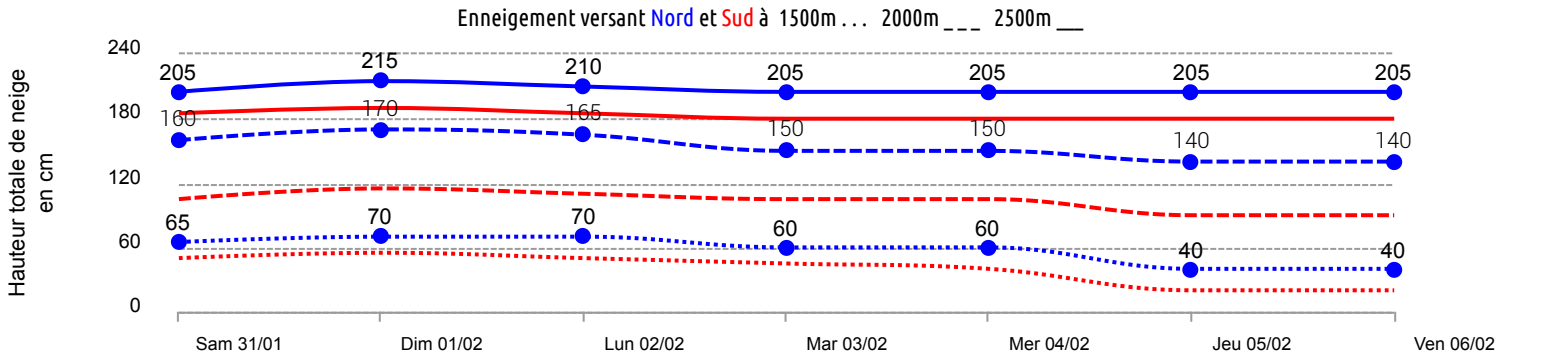

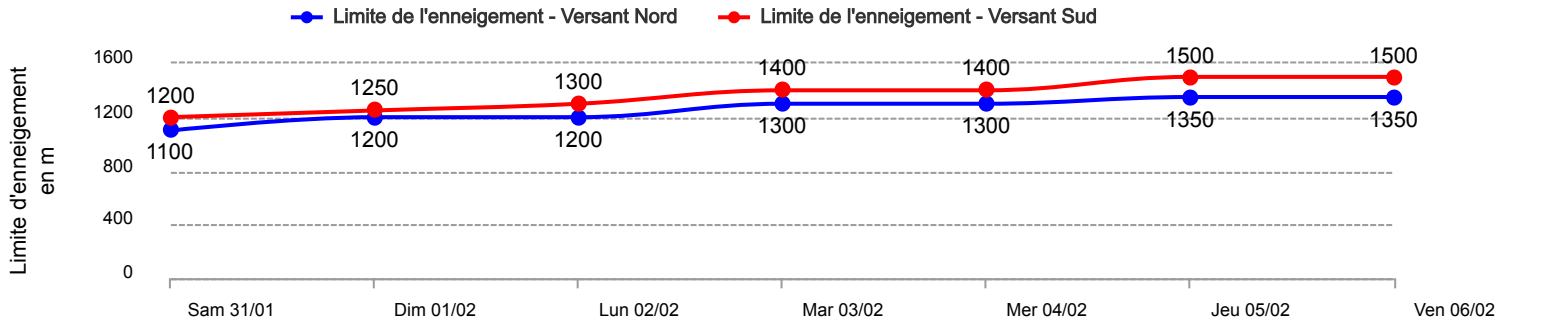

Pour consulter la vigilance en cours, veuillez vous rendre sur le site https://vigilance.meteofrance.fr/fr

Météo-France - 73 avenue de Paris, 94165 Saint-Mandé cedex - Contact : contact@meteo.fr

Rédigé par Météo-France avec la contribution des observateurs du réseau nivo-météorologiques. Partenariat : ANMSM (Maires de Stations de Montagne), DSF (Domaines Skiables de France), ADSP (Directeurs de Pistes et de la Sécurité des Stations de Sports d'Hiver) et autres acteurs de la montagne.

Bulletin neige & avalanches par téléphone au
0 892 68 10 20 Service 0,35 € / min + prix appel