Bulletin d'estimation du risque d'avalanche

(valable en dehors des pistes balisées et ouvertes)

MASSIF : Mercantour

Rédigé le vendredi 6 février 2026 à 16h

Estimation des risques pour le : SAMEDI 07 FÉVRIER

RISQUE MARQUÉ DÉCLENCHEMENT SKIEUR. INSTABILITÉS, LOCALEMENT VOLUMINEUSES.

3

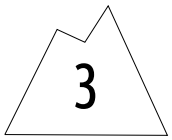

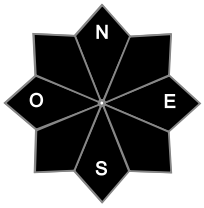

Indice de risque marqué.

Départs spontanés : éventuels départs ponctuels superficiels en neige humide

Déclenchements provoqués : Plaques, faciles à déclencher, aussi à distance

Indices de risque : 5 très fort - 4 fort - 3 marqué - 2 limité - 1 faible -- En noir : les pentes les plus dangereuses

Stabilité du manteau neigeux

Situation avalancheuse typique : neige fraîche couche fragile persistante

Déclenchements provoqués : instabilités possiblement présentes en toute orientation. Elles peuvent être difficiles à détecter car d'aspect poudreux, sinon durcies par le vent dans les secteurs exposés. Déclenchement encore facile par un skieur ou randonneur, parfois à distance, engendrant généralement une avalanche de plaque de taille petite à moyenne, ponctuellement grande en Vésubie / Roya, dans la neige fraiche/récente. Toutefois, en versants est, nord et ouest au-dessus de 1800/2000 m, possibles avalanches de plaque de grande taille emportant une grande partie du manteau neigeux, parfois sur de grandes distances. Toutefois, leur déclenchement semble plus difficile car dans ces orientations la couche fragile persistante est souvent enfouie. Sollicitation plutôt sous une forte contrainte comme le déclenchement d'une première avalanche en surface.

Départs spontanés : en journée de samedi, en pente raide ensoleillée, éventuels départs ponctuels en neige humide, généralement de petite taille, voire moyenne. Pouvant très localement, déclencher une plaque par surcharge.

Qualité de la neige

Enneigement bon voire excédentaire jusqu'à basse altitude pour un début février. Données observées : 135 cm à la nivôse de Millefonts à 2400 m, 126 cm à Isola 2000 à 1912m.

Enneigement skiable dès 1200/1300 m en terrain favorable, mais peu de sous-couche sous 1600 m en général.

État de la neige en surface : neige croutée en adrets jusque vers 1900/2200 m, plus bas en ubacs, s'humidifiant en journée. Sinon neige fraiche/récente en quantité, poudreuse, localement densifiée par le vent. Corniches et congères parfois volumineuses en place.

Aperçu météo pour le samedi 07 février

nuit	matin	après-midi	soir
S'ennuageant en journée. Vent faible.			

Pluie-Neige				
Iso 0 °C	2 000 m	1 800 m	1 700 m	1 800 m
Vent 2000 m	↘ 15 km/h	↖ 10 km/h	↓ 15 km/h	↓ 15 km/h
Vent 3000 m	↘ 35 km/h	↖ 15 km/h	↖ 15 km/h	↘ 15 km/h

Épaisseur de neige hors-piste

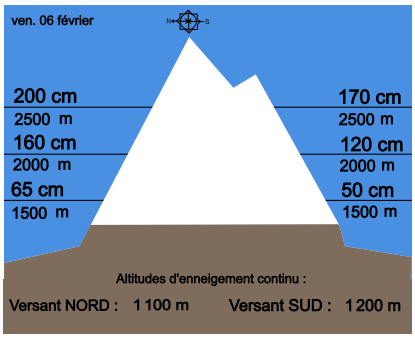

Précipitations à 1800 m

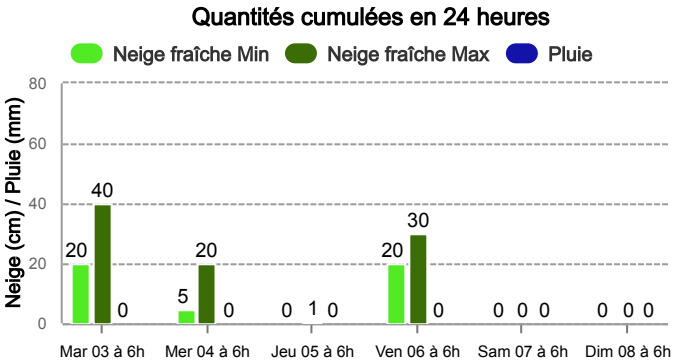

Tendance du dimanche 08 février

3

Indice de risque marqué

Instabilités encore faciles à déclencher, localement volumineuses. Risque Marqué.

Pour consulter la vigilance en cours, veuillez vous rendre sur le site https://vigilance.meteofrance.fr/fr

Météo-France - 73 avenue de Paris, 94165 Saint-Mandé cedex - Contact : contact@meteo.fr

Rédigé par Météo-France avec la contribution des observateurs du réseau nivo-météorologiques. Partenariat : ANMSM (Maires de Stations de Montagne), DSF (Domaines Skiables de France), ADSP (Directeurs de Pistes et de la Sécurité des Stations de Sports d'Hiver) et autres acteurs de la montagne.

Bulletin neige & avalanches par téléphone au 0 892 68 10 20 Service 0,35 € / min + prix appel

RÉPUBLIQUE FRANÇAISE
Liberté Égalité Fraternité

METEO FRANCE
À VOS CÔTÉS, DANS UN CLIMAT QUI CHANGE

Bulletin d'estimation du risque d'avalanche

(valable en dehors des pistes balisées et ouvertes)

MASSIF : Mercantour

Rédigé le vendredi 6 février 2026 à 16h

Conditions nivo-météo des 7 derniers jours

	sam. 31/01				dim. 01/02				lun. 02/02				mar. 03/02				mer. 04/02				jeu. 05/02				ven. 06/02			
	03h	09h	15h	21h	03h	09h	15h	21h	03h	09h	15h	21h	03h	09h	15h	21h	03h	09h	15h	21h	03h	09h	15h	21h	03h	09h	15h	21h
Météo																												
Vent (km/h)	20	20	30	20	15	15	20	20	25	35	45	60	75	50	35	30	35	20	25	25	35	40	40	45	40	45	40	30
à 3000m	←	↖	↓	↘	↘	↗	→	→	→	↑	↑	↑	↑	↑	↗	↗	↗	←	↗	→	↘	↗	↗	↑	↘	↘	↘	↘
Vent (km/h)	10	15	20	10	15	10	10	10	10	10	20	25	25	40	25	15	15	25	15	10	15	15	25	20	35	20	20	15
à 2000m	→	↓	↓	↘	↓	↖	↘	→	→	↗	↑	↑	↖	↗	↗	↑	↓	↙	↗	→	↘	↘	↗	↓	↓	↘	↘	↘

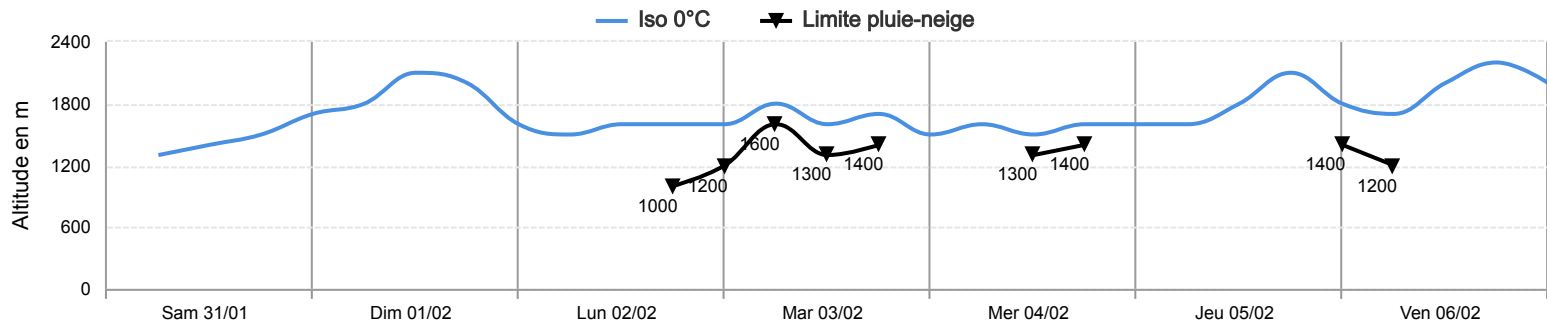

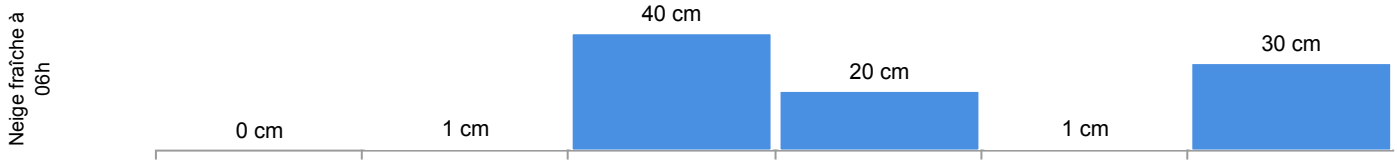

Risque d'avalanche	sam. 31/01	dim. 01/02	lun. 02/02	mar. 03/02	mer. 04/02	jeu. 05/02	ven. 06/02
	3	3	3	4	4	3	4

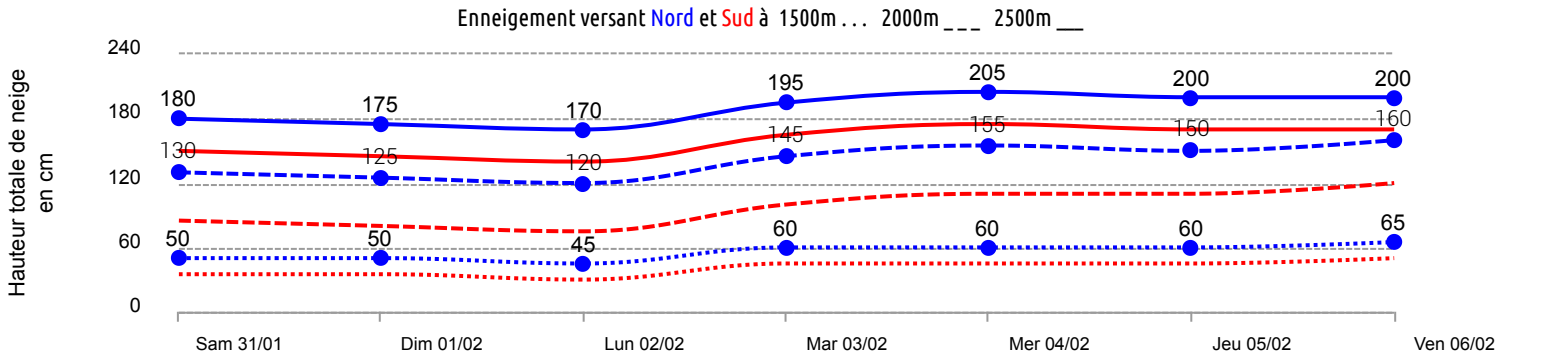

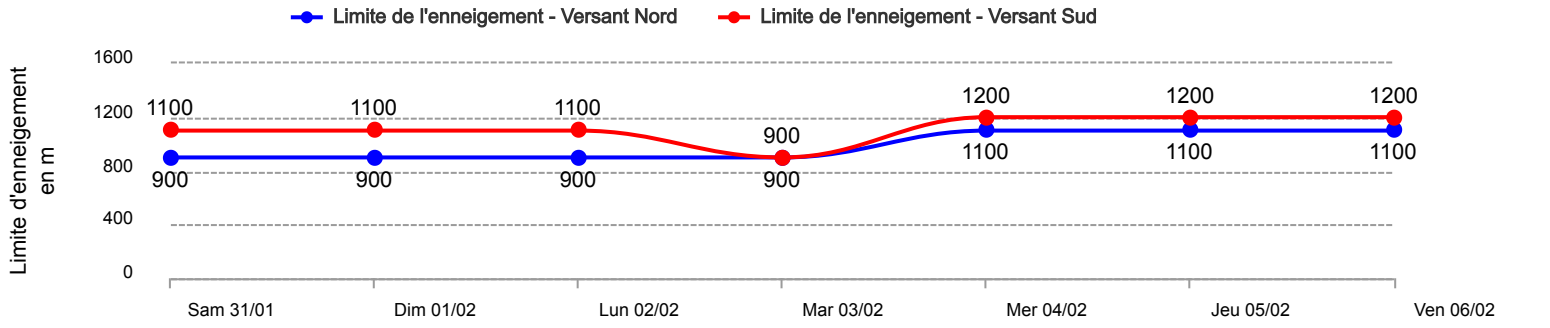

Pour consulter la vigilance en cours, veuillez vous rendre sur le site https://vigilance.meteofrance.fr/fr

Météo-France - 73 avenue de Paris, 94165 Saint-Mandé cedex - Contact : contact@meteo.fr

Rédigé par Météo-France avec la contribution des observateurs du réseau nivo-météorologiques. Partenariat : ANMSM (Maires de Stations de Montagne), DSF (Domaines Skiables de France), ADSP (Directeurs de Pistes et de la Sécurité des Stations de Sports d'Hiver) et autres acteurs de la montagne.

Bulletin neige & avalanches par téléphone au

0 892 68 10 20 Service 0,35 € / min + prix appel