Bulletin d'estimation du risque d'avalanche
(valable en dehors des pistes balisées et ouvertes)

MASSIF : Pays-Basque

Rédigé le vendredi 6 février 2026 à 16h

Estimation des risques pour le : SAMEDI 07 FÉVRIER

QUELQUES PLAQUES SUR MANTEAU HUMIDE

2

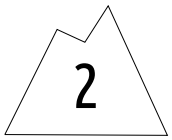

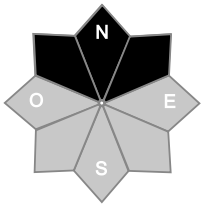

Indice de risque limité.

Départs spontanés : Ponctuels en neige humide, rares cassures linéaires en neige ventée.

Déclenchements provoqués : Plaques peu épaisses en Nord à Est au-dessus de 1800 m.

Indices de risque : 5 très fort - 4 fort - 3 marqué - 2 limité - 1 faible -- En noir : les pentes les plus dangereuses

Stabilité du manteau neigeux

Situation avalancheuse typique : neige humide neige ventée

Déclenchements provoqués : Manteau humidifié jusqu'à 1800/2000 m sur lequel quelques plaques sont formées au-dessus de 1600 m principalement en **versants Nord à Est** : Plaques déclenchables par **faible sollicitation**. Avec le vent fort, ces plaques se sont **formées loin des crêtes, cols et sommets** dans les secteurs déventés, **Avalanche possible de taille 1, très localement de taille 2** .
Dans tous les autres secteurs et plus bas, neige très travaillée par le vent, les plaques présentes s'humidifient en journée et deviennent rapidement difficilement déclenchables.

Départs spontanés : Avalanches de fond ou neige humide.
- **en neige sèche dans les versants Nord à Est** : rares départs **ponctuels de coulées ou petites avalanches (taille 1)** en neige sèche en pentes raides au-dessus de 1800/2000 m.
- **en neige humide** : l'humidification est à l'origine de départs ponctuels de neige alourdie plus fréquents à toutes altitudes et versants généralement de taille 1, des avalanches de glissement sur l''herbe pouvant être de taille 2.

Qualité de la neige

Enneigement : bon pour la saison, mais les crêtes, cols et sommets sont souvent pelés par le vent dans les expositions ouest. La neige fraîche au sol s'humidifie en journée au soleil jusqu'en haut du massif, sous 1800/2000 m en versants ombrés.
Limites skiables : manteau neigeux skiable à partir de 1600 /1700 m avec sous-couche portante.
État de la neige : Neige croutée au matin pouvant être portante. La neige devient molle et humide au soleil en journée.

Aperçu météo pour le samedi 07 février

	nuit	matin	après-midi	soir
	Ciel peu nuageux, quelques nuages frontaliers, voilé en après-midi, nuageux en soirée avec quelques précipitations.			
Pluie-Neige				1 300 m
Iso 0 °C	1 400 m	1 700 m	1 600 m	1 600 m
Vent 1000 m	↗ 55 km/h	↗ 55 km/h	↑ 60 km/h	↑ 50 km/h
Vent 2000 m	↗ 70 km/h	↗ 70 km/h	↑ 80 km/h	↑ 75 km/h

Épaisseur de neige hors-piste

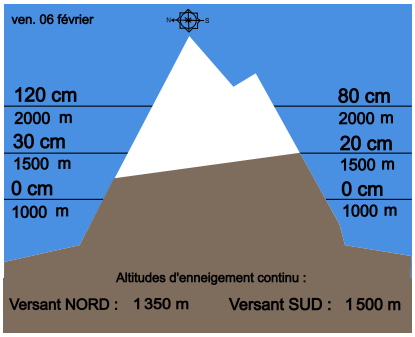

Précipitations à 1800 m

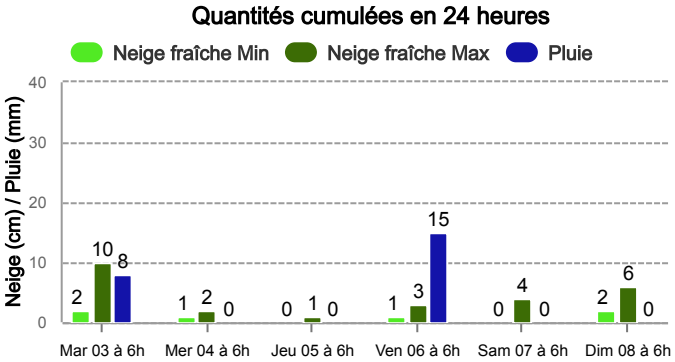

Tendance du dimanche 08 février

2

Indice de risque limité

Précipitations neigeuses, plaques en formation.

Pour consulter la vigilance en cours, veuillez vous rendre sur le site https://vigilance.meteofrance.fr/fr

Météo-France - 73 avenue de Paris, 94165 Saint-Mandé cedex - Contact : contact@meteo.fr

Rédigé par Météo-France avec la contribution des observateurs du réseau nivo-météorologiques. Partenariat : ANMSM (Maires de Stations de Montagne), DSF (Domaines Skiables de France), ADSP (Directeurs de Pistes et de la Sécurité des Stations de Sports d'Hiver) et autres acteurs de la montagne.

Bulletin neige & avalanches par téléphone au **0 892 68 10 20** Service 0,35 € / min + prix appel

RÉPUBLIQUE FRANÇAISE
Liberté Égalité Fraternité

METEO FRANCE
À VOS CÔTÉS, DANS UN CLIMAT QUI CHANGE

Bulletin d'estimation du risque d'avalanche
(valable en dehors des pistes balisées et ouvertes)
MASSIF : Pays-Basque

Rédigé le vendredi 6 février 2026 à 16h

Conditions nivo-météo des 7 derniers jours

	sam. 31/01				dim. 01/02				lun. 02/02				mar. 03/02				mer. 04/02				jeu. 05/02				ven. 06/02			
	03h	09h	15h	21h	03h	09h	15h	21h	03h	09h	15h	21h	03h	09h	15h	21h	03h	09h	15h	21h	03h	09h	15h	21h	03h	09h	15h	21h
Météo																												
Vent (km/h)	70	90	90	60	70	45	50	80	95	120	120	80	80	80	65	80	100	85	65	70	90	130	95	90	95	95	80	70
à 2000m	↑	→	↘	↘	↘	↗	↗	↑	↑	↑	↑	↗	↗	↑	↑	↑	↑	↗	→	↗	↑	↑	↑	↗	↗	↗	↗	↗
Vent (km/h)	50	70	70	35	30	30	40	60	60	90	90	55	55	55	40	45	50	40	45	60	80	90	65	60	75	70	60	50
à 1000m	→	→	→	→	→	↑	↑	↑	↑	↑	↑	↗	↑	↑	↑	↑	↑	↑	↑	↑	↑	↑	↗	↗	↗	↗	↑	↑

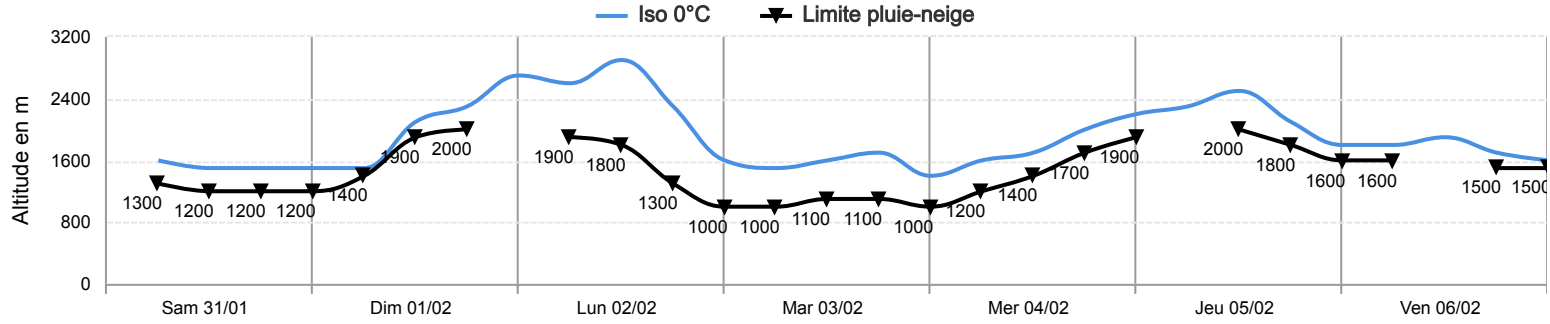

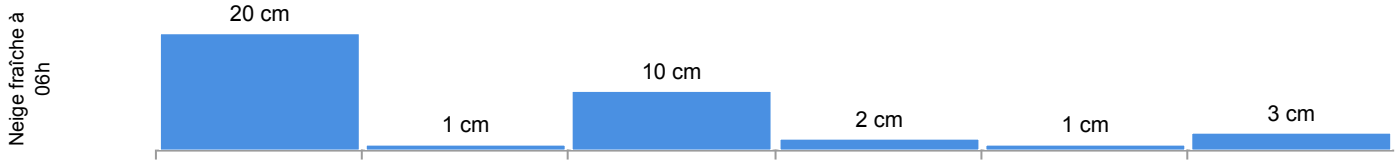

Risque d'avalanche							
	4	3	3	2	2	2	2
	sam. 31/01	dim. 01/02	lun. 02/02	mar. 03/02	mer. 04/02	jeu. 05/02	ven. 06/02

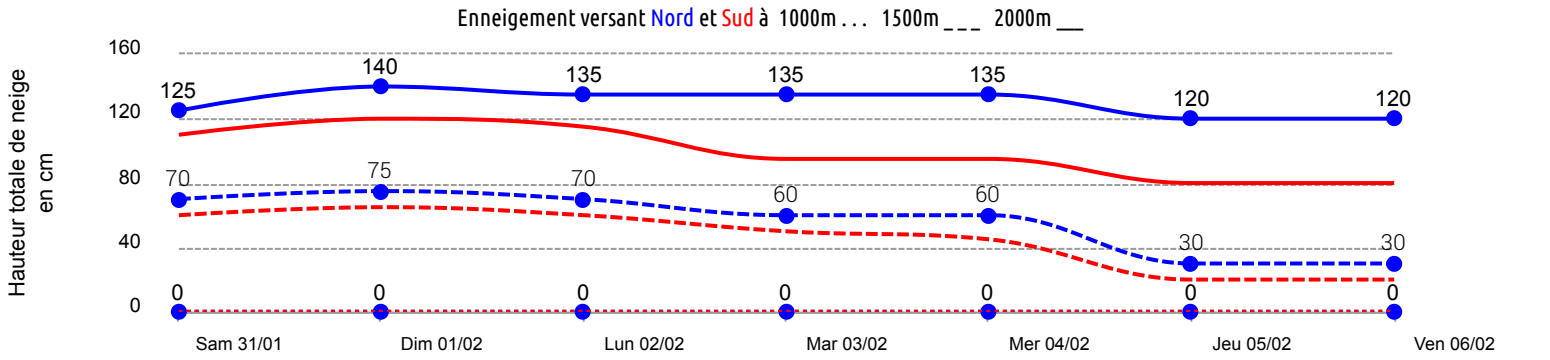

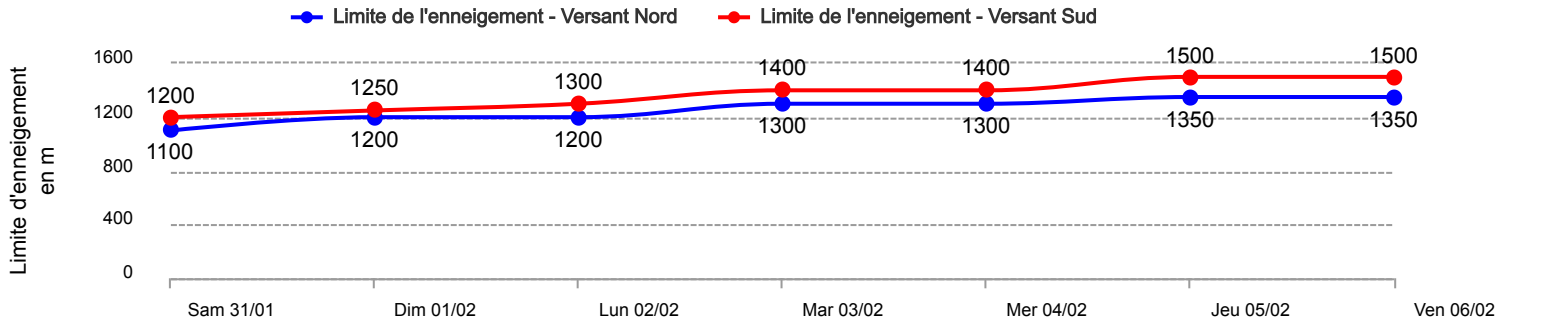

Pour consulter la vigilance en cours, veuillez vous rendre sur le site https://vigilance.meteofrance.fr/fr

Météo-France - 73 avenue de Paris, 94165 Saint-Mandé cedex - Contact : contact@meteo.fr

Rédigé par Météo-France avec la contribution des observateurs du réseau nivo-météorologiques. Partenariat : ANMSM (Maires de Stations de Montagne), DSF (Domaines Skiables de France), ADSP (Directeurs de Pistes et de la Sécurité des Stations de Sports d'Hiver) et autres acteurs de la montagne.

Bulletin neige & avalanches par téléphone au
0 892 68 10 20 Service 0,35 € / min + prix appel