Bulletin d'estimation du risque d'avalanche

(valable en dehors des pistes balisées et ouvertes)

MASSIF : Thabor

Rédigé le vendredi 6 février 2026 à 16h

Estimation des risques pour le : SAMEDI 07 FÉVRIER

FORTE PROBABILITÉ DE DÉCLENCHEMENTS DE PLAQUES VOLUMINEUSES

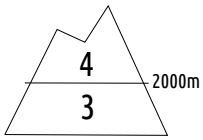

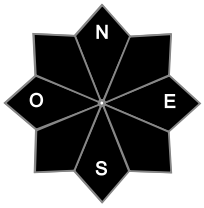

Au-dessus de 2000m indice de risque fort, plus bas indice marqué.

Départs spontanés : en neige récente humidifiée, voire en plaque.

Déclenchements provoqués : plaques faciles à déclencher, parfois larges et épaisses.

Indices de risque : 5 très fort - 4 fort - 3 marqué - 2 limité - 1 faible -- En noir : les pentes les plus dangereuses

Stabilité du manteau neigeux

Situation avalancheuse typique : neige fraîche couche fragile persistante

Invitation à la prudence en montagne (émission d'un communiqué spécial avalanche)

Déclenchements provoqués : le manteau neigeux reste peu stabilisé dans de nombreuses pentes, en particulier au-dessus de 2000 m. Les plaques d'aspect poudreux sont fréquentes et souvent difficiles à identifier. Déclenchements faciles, parfois même à distance, suite à la présence de plusieurs couches fragiles dans le manteau neigeux. En cas de rupture, elles engendrent des avalanches moyennes à grandes (taille 2 à 3), avec des cassures pouvant dépasser la centaine de mètres de largeur quand la topographie s'y prête.
Dans les ubacs (pentes ouest, nord à est), des cassures épaisses (> 1 m) emportant la quasi-totalité du manteau neigeux peuvent être observées, en cas de rupture sur l'importante couche fragile persistante enfouie à la base du manteau neigeux (détectable avec un test du bâton quand l'épaisseur de neige n'est pas trop importante). Un premier départ de surface peut faciliter le déclenchement en contrebas de ces plaques volumineuses.

Départs spontanés : quelques départs de neige récente humidifiée dans les pentes raides au soleil près des rochers. Avalanches petites à moyennes (taille 1 à 2), en poire. Ces départs ponctuels peuvent déclencher des avalanches de plaques sur leur trajet, avec les caractéristiques décrites au paragraphe des déclenchements provoqués.

Qualité de la neige

L'enneigement est plutôt excédentaire pour un début février, notamment en vallées, mais légèrement déficitaire sur la partie savoyarde du massif.
Données observées vers 2500 m : 170 cm de neige dans le vallon du Chardonnet, 130 cm à la Nivôse du Galibier, 48 cm à celle des Rochilles.

Limite d'enneigement skiable : la plupart des itinéraires sont skiables dès les fonds de vallées.

État de la neige de surface : 20/30 cm de neige fraîche en général. Elle est souvent légère et poudreuse, parfois densifiée ou cartonnée par le vent près des crêtes. Dans les adrets, fine croûte le matin sous 2000 m en général, s'humidifiant au soleil en journée.

Aperçu météo pour le samedi 07 février

nuit	matin	après-midi	soir

Temps sec, voilé à nuageux, mais les sommets restent hors de la couche nuageuse. Vent faible à toute altitude.

Pluie-Neige				
Iso 0 °C	1 600 m	1 600 m	1 700 m	1 700 m
Vent 2000 m	↘ 10 km/h	↖ 10 km/h	↑ 15 km/h	← 10 km/h
Vent 3000 m	↘ 25 km/h	↑ 20 km/h	↑ 15 km/h	↘ 15 km/h

Épaisseur de neige hors-piste

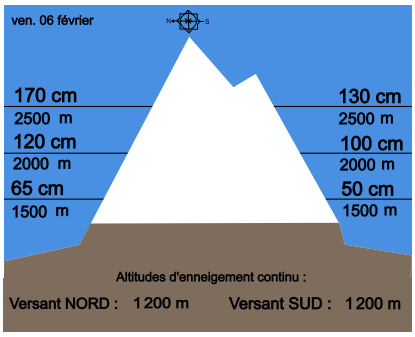

Précipitations à 1800 m

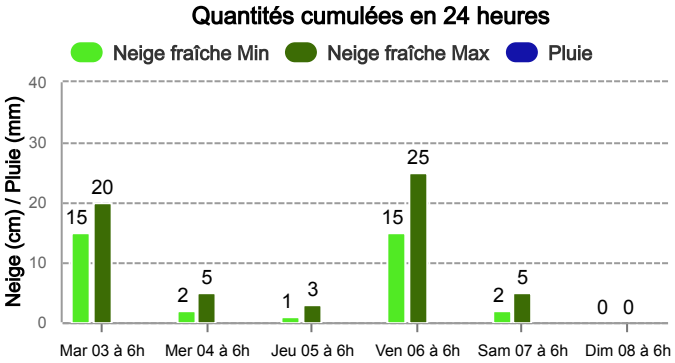

Tendance du dimanche 08 février

Indice de risque marqué

Lente stabilisation du manteau neigeux, avec encore des plaques pouvant céder au passage d'un skieur. Risque marqué.

Pour consulter la vigilance en cours, veuillez vous rendre sur le site https://vigilance.meteofrance.fr/fr

Météo-France - 73 avenue de Paris, 94165 Saint-Mandé cedex - Contact : contact@meteo.fr

Bulletin neige & avalanches par téléphone au 0 892 68 10 20 Service 0,35 € / min + prix appel

Rédigé par Météo-France avec la contribution des observateurs du réseau nivo-météorologiques. Partenariat : ANMSM (Maires de Stations de Montagne), DSF (Domaines Skiables de France), ADSP (Directeurs de Pistes et de la Sécurité des Stations de Sports d'Hiver) et autres acteurs de la montagne.

RÉPUBLIQUE FRANÇAISE
Liberté Égalité Fraternité

METEO FRANCE
À VOS CÔTÉS, DANS UN CLIMAT QUI CHANGE

Bulletin d'estimation du risque d'avalanche

(valable en dehors des pistes balisées et ouvertes)

MASSIF : Thabor

Rédigé le vendredi 6 février 2026 à 16h

Conditions nivo-météo des 7 derniers jours

	sam. 31/01				dim. 01/02				lun. 02/02				mar. 03/02				mer. 04/02				jeu. 05/02				ven. 06/02			
	03h	09h	15h	21h	03h	09h	15h	21h	03h	09h	15h	21h	03h	09h	15h	21h	03h	09h	15h	21h	03h	09h	15h	21h	03h	09h	15h	21h
Météo																												
Vent (km/h)	25	25	5	25	30	20	20	20	20	25	40	60	80	60	50	40	40	30	10	10	30	25	50	35	40	40	40	25
à 3000m																												
Vent (km/h)	10	15	5	10	15	15	15	10	10	10	20	40	40	30	25	15	20	20	15	10	10	15	30	20	15	25	25	15
à 2000m																												

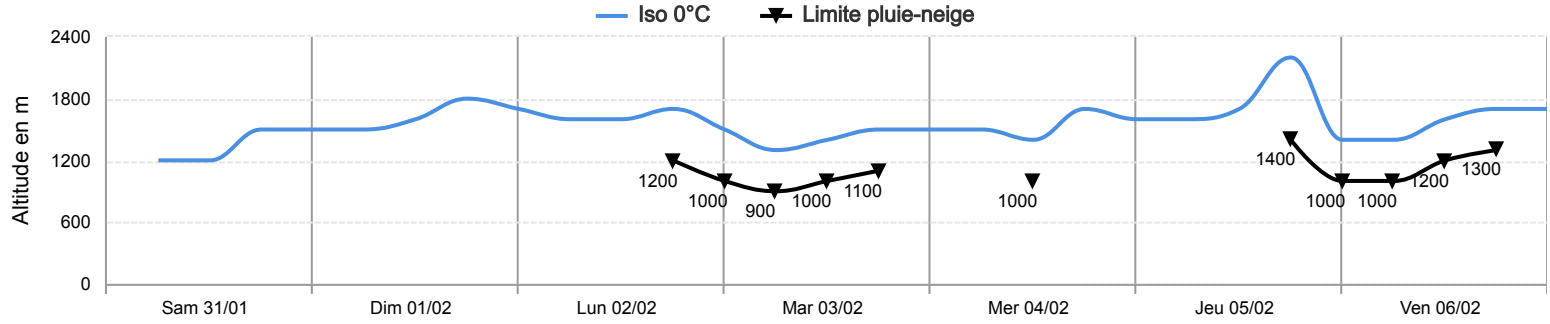

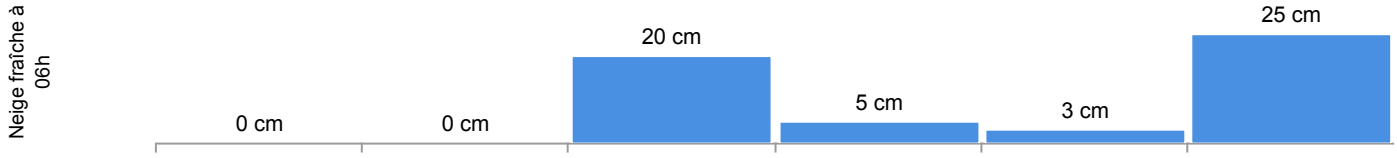

Risque d'avalanche	sam. 31/01	dim. 01/02	lun. 02/02	mar. 03/02	mer. 04/02	jeu. 05/02	ven. 06/02
	3	3	3	4	4	3	4

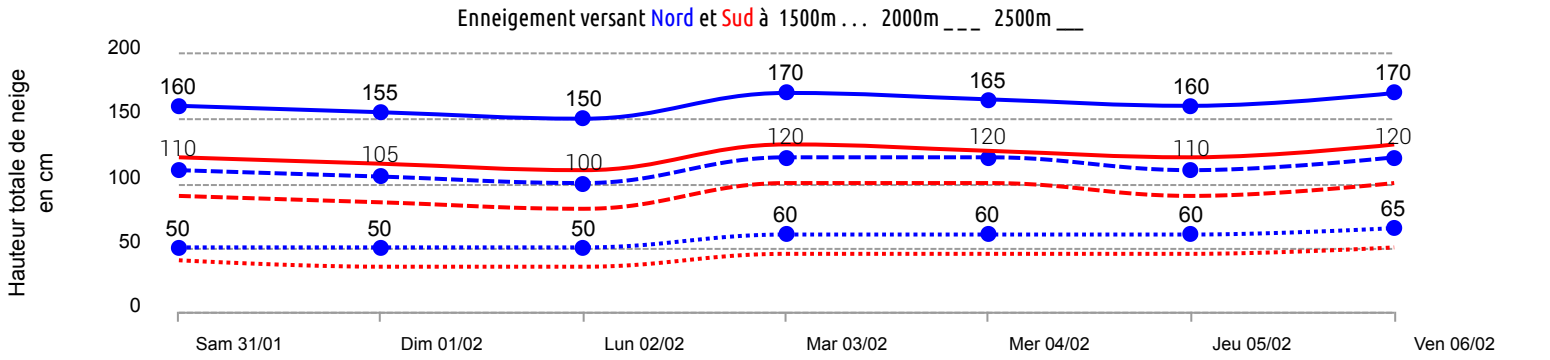

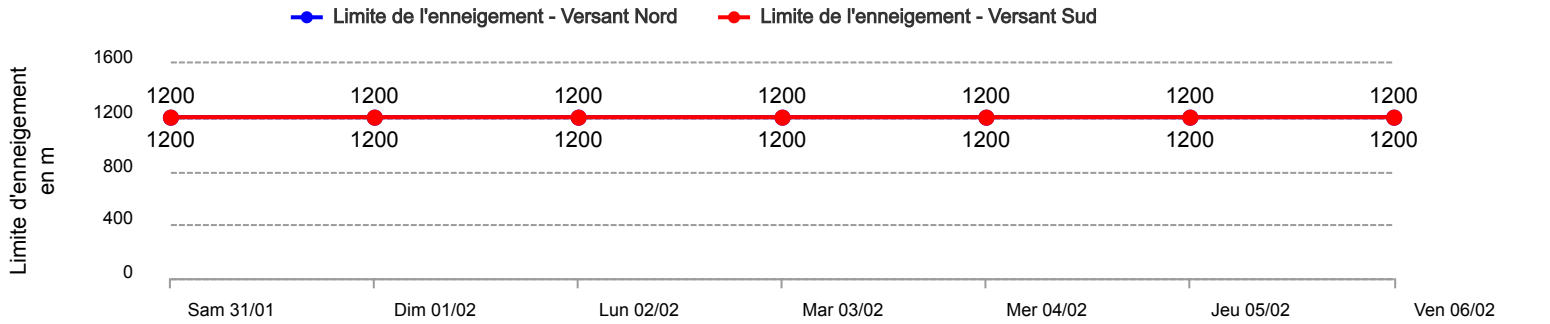

Pour consulter la vigilance en cours, veuillez vous rendre sur le site https://vigilance.meteofrance.fr/fr

Météo-France - 73 avenue de Paris, 94165 Saint-Mandé cedex - Contact : contact@meteo.fr

Rédigé par Météo-France avec la contribution des observateurs du réseau nivo-météorologiques. Partenariat : ANMSM (Maires de Stations de Montagne), DSF (Domaines Skiables de France), ADSP (Directeurs de Pistes et de la Sécurité des Stations de Sports d'Hiver) et autres acteurs de la montagne.

Bulletin neige & avalanches par téléphone au
0 892 68 10 20 Service 0,35 € / min + prix appel