GOBIERNO DE ESPAÑA
VICEPRESIDENCIA TERCERA DEL GOBIERNO
MINISTERIO PARA LA TRANSICIÓN ECOLÓGICA Y EL RETO DEMOGRÁFICO

Boletín de información nivológica y de peligro de aludes

Pirineo Navarro y Aragonés

aemet Agencia Estatal de Meteorología

sábado, 7 de febrero de 2026

Pronóstico hasta las 24 horas del domingo, día 8 de febrero

(Válido fuera de pistas de esquí balizadas y abiertas)

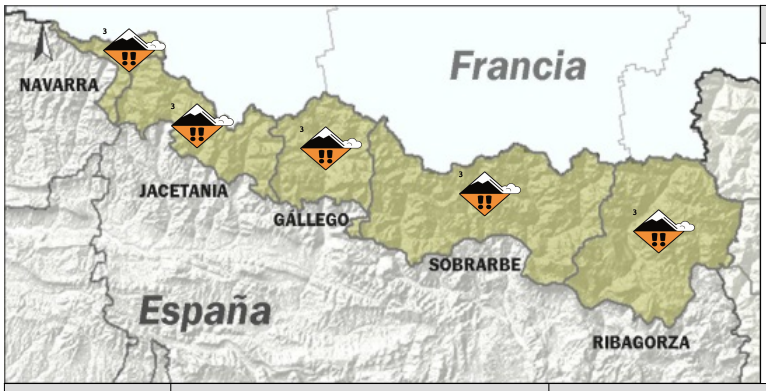

Problemas de aludes

Placas de viento

Nieve reciente

Macizo	Peligro	Problemas de aludes, cota, orientación, tamaño	Innivación observada (m)
Navarra	3 Notable	Placas de viento: 2100, N O E S, 3 Nieve reciente: N O E S, 2	2026-02-07 N S Cotas bajas
Jacetania	3 Notable	Placas de viento: 2100, N O E S, 3 Nieve reciente: N O E S, 2	2026-02-07 N S Cotas bajas
Gállego	3 Notable	Placas de viento: 2100, N O E S, 3 Nieve reciente: N O E S, 2	2026-02-07 N S Cotas bajas

AEMET. Se autoriza la reproducción de su contenido citando la fuente.

Boletín de información nivológica y de peligro de aludes

Pirineo Navarro y Aragonés

Sobrarbe	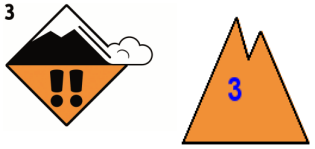 **Notable**	**Placas de viento** 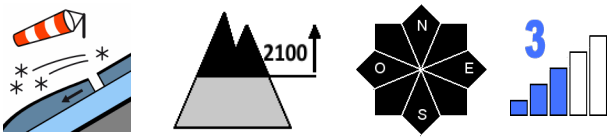 **Nieve reciente** 	2026-02-07 Cotas bajas
Ribagorza	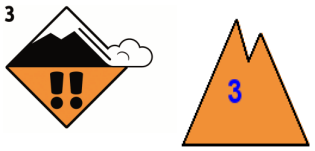 **Notable**	**Placas de viento** 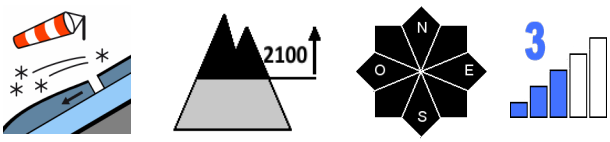 **Nieve reciente** 	2026-02-07 Cotas bajas

Estado del manto y observaciones recientes

El paso de sucesivas borrascas asociadas al chorro polar, está dejando abundantes precipitaciones en la cordillera desde hace semanas. En las últimas 24 horas las nevadas han sido débiles, y solo se han depositado unos 5 cm nuevos en algunos puntos de observación, mientras que en otros se han registrado pérdidas de hasta 10-15 cm.

El manto es continuo desde cotas bajas, con espesores que, por lo general, se encuentran muy por encima de lo que sería habitual para esta época del año. A 1300-1500 metros rondan los 40-90 cm, y se van incrementando conforme ascendemos, de manera que a unos 2100 metros se superan fácilmente los 200-220 cm, aún más en ventisqueros, hoyas y otras zonas propensas a la acumulación.

El perfil del manto consta de una capa superficial de nieve reciente de espesor variable y otras múltiples en el interior donde se van intercalando grano fino o redondo con costras de rehielo. En cotas altas la nieve se mantiene más seca, venteada y menos evolucionada, en particular en zonas de umbría, donde todavía persisten estratos débiles, en algunos casos situados en la base del manto. Además, hay varias generaciones de placas de viento, que abarcan todas las orientaciones, y que pueden colapsar ante sobrecargas débiles.

En las últimas 24 horas se han reportado 9 aludes medianos en el Sobrarbe, todos en orientación nordeste, algunos de placa dura y salida a 2250-2500 metros y otros de nieve reciente húmeda a 2000-2250 metros. Así como alguna colada en vertiente este a 2220-2500 metros en la Ribagorza y algunos disparos positivos en Jacetania, que han desencadenado coladas a 2000-2250 metros en orientación oeste.

AEMET. Se autoriza la reproducción de su contenido citando la fuente.

Evolución del manto y peligro de aludes para el domingo, día 8

Problema de nieve reciente. Problema de placas de viento y capas débiles persistentes en cotas altas.

No se esperan grandes cambios para el domingo, continuarán las nevadas, que podrán dejar unos 10-20 cm nuevos en los macizos occidentales y divisoria, localmente algo más, siendo las cantidades menores en el resto. En consecuencia, serán probables las purgas de nieve reciente en las laderas suficientemente inclinadas de cualquier orientación y cota, de tamaño pequeño (riesgo de caída) o mediano (capaz de enterrar a una persona), aunque no se descarta que en zonas donde las acumulaciones sean importantes puedan adquirir dimensiones mayores.

Mañana el viento girará a noroeste, y formará nuevas placas en diferentes áreas de cotas altas, aunque con preferencia en vertientes este y sur. Estas se sumarán a las ya existentes, que abarcan todas las orientaciones, y que en algunos casos son difíciles de localizar, al haber quedado ocultas por las nevadas de los últimos días. Todas estas estructuras permanecerán frágiles y podrán fracturar ante una sobrecarga débil (paso de un solo esquiador), provocando aludes que pueden alcanzar dimensión grande, tamaño suficiente como para enterrar a un grupo de personas.

Además, en las umbrías de la alta montaña podemos encontrar capas débiles persistentes en el interior del manto, que siguen dando muestras de reactividad, especialmente en zonas de poco espesor, y que en caso de colapsar podrían ocasionar aludes grandes, aunque sin descartar que localmente pueda producirse alguno de mayor tamaño.

Predicción meteorológica para el domingo, día 8

Pirineo navarro:

Muy nuboso o cubierto con nubes bajas, tendiendo a intervalos nubosos al final del día. Visibilidad localmente reducida. Se esperan precipitaciones débiles o localmente moderadas, siendo más abundantes en el norte. Cota de nieve en torno a 1200 metros. Temperaturas mínimas con pocos cambios, y máximas en descenso. Heladas débiles, moderadas y persistentes en cotas altas. Viento del sur y suroeste, girando a noroeste por la mañana, moderado o fuerte, más intenso por la tarde, cuando podrían soplar rachas muy fuertes en cotas altas y zonas expuestas.

Pirineo aragonés:

Muy nuboso o cubierto con nubes bajas. A partir del mediodía se abrirán grandes claros, primero en el este, quedando al final con intervalos nubosos en la divisoria y poco nuboso o despejado en el resto. Periodos de visibilidad localmente reducida. Se esperan precipitaciones débiles, localmente moderadas en los macizos occidentales y resto de la divisoria. Cota de nieve en torno a 1200 metros. Temperaturas mínimas con pocos cambios en la mitad occidental y en ascenso en la oriental. Máximas en ligero ascenso o sin cambios. Heladas débiles, moderadas y persistentes en cotas altas. Viento de componente sur, girando a noroeste por la mañana, moderado o fuerte, más intenso por la tarde, cuando podrían soplar rachas muy fuertes en cotas altas y zonas expuestas.

AEMET. Se autoriza la reproducción de su contenido citando la fuente.

Datos en la atmósfera libre:

Altitud de la isoterma de 0 ºC: 1600 m
Altitud de la isoterma de -10 ºC: 3200 m

Viento a 1500 m: NW 40 km/h
Viento a 3000 m: NW 50 km/h (W) - NW 30 km/h (E)

Evolución para el lunes día 9

Con pocos cambios.

(Información elaborada a partir de los datos recibidos de los refugios de Linza, Lizara, Panticosa, Bachimaña, Góriz, Pineta, Estós, Angel Orús, La Renclusa, Cap de Llauset y Belagua, de las estaciones de esquí de Astún y Formigal y de la estación de esquí de fondo de Llanos del Hospital)

Escala europea de peligro de aludes

Débil | Limitado | Notable | Fuerte | Muy Fuerte

Problemas de aludes

Nieve reciente | Placas de viento | Capas débiles persistentes | Nieve húmeda | Deslizamientos basales | Sin problema evidente

Nota1: Se recuerda que, siempre que haya nieve, la ausencia total de peligro no existe. Hay que tener presente que en circunstancias desfavorables, con aludes de tamaño 1 (alud pequeño o colada) y tamaño 2 (alud mediano), se pueden sufrir severos daños personales.

Nota2: Los BPA se elaboran en base a información meteorológica así como al estado del manto nivoso a través de sondeos puntuales. Se advierte a los usuarios de la variabilidad de esta información al extrapolarla a zonas extensas de montaña. Por ello, AEMET no se hace responsable de su uso para la toma de decisiones que conciernen a la seguridad personal, ni de los riesgos físicos o materiales de ellas derivadas.

AEMET. Se autoriza la reproducción de su contenido citando la fuente.