ICGC Institut Cartogràfic i Geològic de Catalunya

Servei Meteorològic de Catalunya meteo.cat

Boletín de peligro de aludes para el Pirineo de Catalunya
Del 07/02/2026 al 09/02/2026

(Válido fuera pistas de esquí y zonas no controladas)

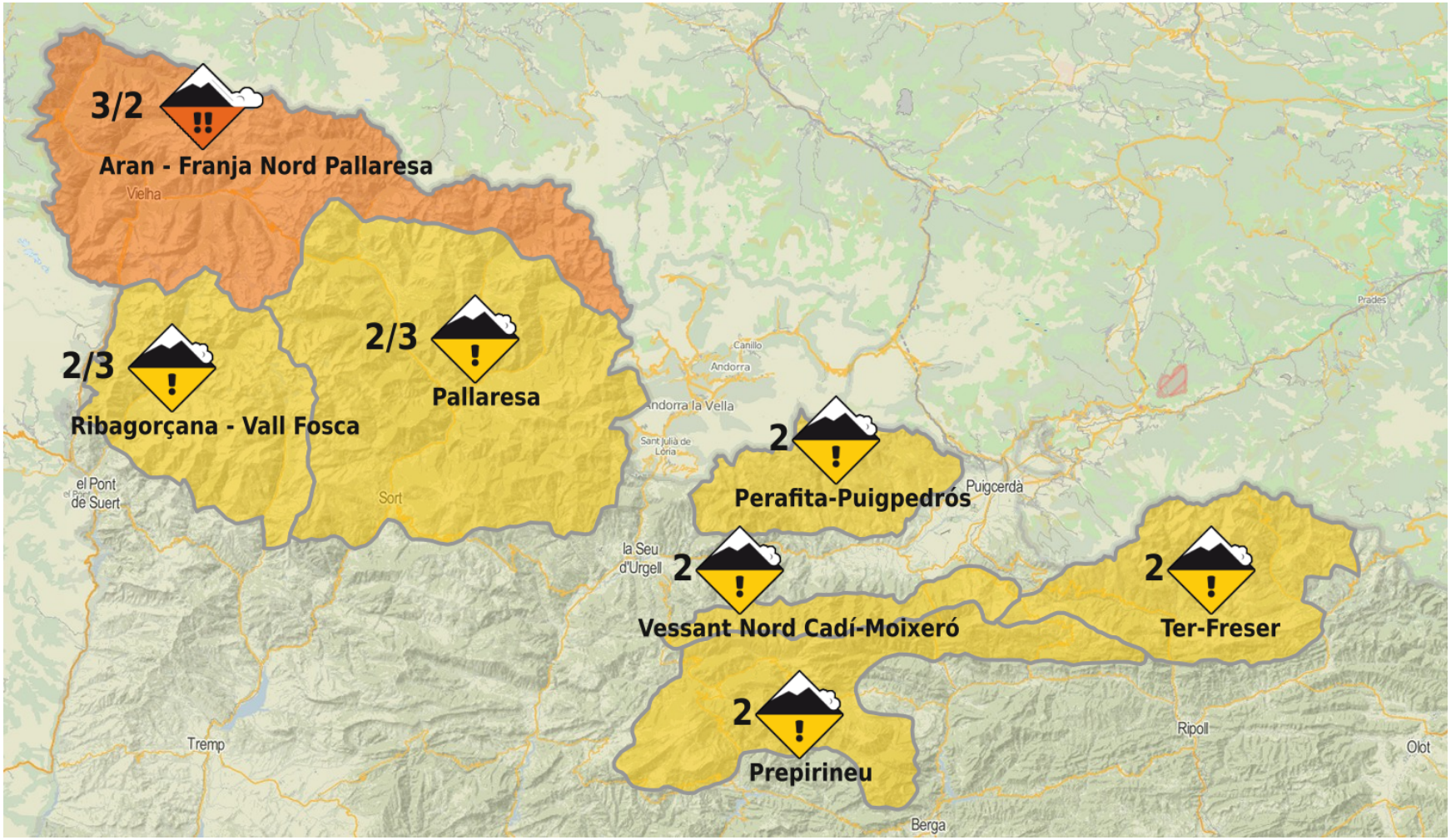

5 MUY FUERTE	4 FUERTE	3 NOTABLE	2 LIMITADO	1 DÉBIL

ICGC Institut Cartogràfic i Geològic de Catalunya

meteo.cat Servei Meteorològic de Catalunya

Boletín de peligro de aludes Aran - Franja Nord Pallaresa Del 07/02/2026 al 09/02/2026

(Válido fuera pistas de esquí y zonas no controladas)

MARCADO (3), por encima de los 2.200 m. MODERADO (2), en el resto.

Situación primaria

Nieve venteada

Distribución

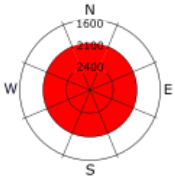

Tamaño

Origen

Tendencia

Situación secundaria

Nieve reciente

Distribución

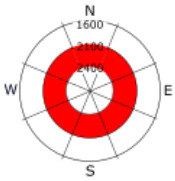

Tamaño

Origen

Tendencia

Estado del manto nivoso

Situación de placas de viento, capa débil persistente, nieve reciente, algún deslizamiento basal residual. Hay placas que todavía pueden caer fácilmente al paso de un esquiador. También hay escarcha superficial y se pueden formar placas muy frágiles encima, durante el fin de semana y el lunes. Hay, además, alguna capa débil enterrada que puede colapsar. En general, las placas están sobre todo por encima del límite del bosque y en cualquier orientación, preferentemente en N y E. Pueden ser de tamaño mediano, capacidad de enterrar a una persona, o incluso a un grupo de personas en caso de capas débiles. Las placas pueden quedar tapadas por nieve reciente. Tenemos además el problema de nieve reciente. Así pués, pueden caer aludes de nieve reciente pequeños de forma natural en cualquier orientación. Hay que tener en cuenta el terreno trampa para evitar daños y ser tapados por los depósitos de los aludes de nieve reciente. No se descarta todavía algún deslizamiento basal residual.

Distribución del manto nivoso

Hay nieve en el suelo a 1.000 m. El manto es esquiable por encima de unos 1.500 m. Los espesores a unos 2.200 m rondan los 100-135 cm en el norte de Arán y 140-190 cm en la Franja Norte Pallaresa y en el sur de Aran, y son superiores a los normales por estas fechas.

Tendencia para las próximas 48-72h

Las bajas temperaturas mantendrán sus placas frágiles. Peligro ESTACIONARIO.

El próximo boletín será emitido el día 2026-02-09

5 MUY FUERTE	4 FUERTE	3 NOTABLE	2 LIMITADO	1 DÉBIL

EAWS EUROPEAN AVALANCHE WARNING SERVICES

ICGC Institut Cartogràfic i Geològic de Catalunya

Servei Meteorològic de Catalunya

Boletín de peligro de aludes Ribagorçana - Vall Fosca Del 07/02/2026 al 09/02/2026

(Válido fuera pistas de esquí y zonas no controladas)

Limitado (2) por debajo de 2400 m, Notable (3) por encima

Situación primaria

Nieve venteada

Distribución

Tamaño

Origen

Tendencia

Situación secundaria

Nieve reciente

Distribución

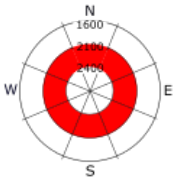

Tamaño

Origen

Tendencia

Estado del manto nivoso

Por encima de los 2300-2400 m, se han dado deflaciones, pero todavía se mantienen placas que localmente pueden dar alguna propagación destacable. Por lo general, hay placas por encima de los 2200 m, en laderas E, N y en algunas zonas S resguardadas del viento de W. Las más sensibles y frágiles están por encima de los 2400 m. Pueden caer fácilmente a nuestro paso y alcanzar tamaño suficiente para enterrar a una persona. También se pueden formar nuevas sobre escarcha recientemente formada. Además, se mantiene el problema de nieve reciente que ha ido purgando de forma natural y que seguirá haciéndolo donde todavía no se haya purgado, sobre todo en momentos de claros. Se prevé, pues, la caída de aludes de nieve reciente de forma natural. Estos aludes serán pequeños (sin capacidad de enterrarnos) y se darán en pendientes fuertemente inclinadas. Con las débiles nevadas previstas, las placas pueden quedarse tapadas y ser difíciles de detectar.

Distribución del manto nivoso

Hay nieve en el suelo a 1.500 m. El manto es esquiable por encima de unos 1500-1600 m. Los grosores alcanzan los 130-160 cm. Estos valores son muy superiores a los normales en la época.

Tendencia para las próximas 48-72h

Las bajas temperaturas mantendrán las placas frágiles. Peligro ESTACIONARIO.

El próximo boletín será emitido el día 2026-02-09

5 MUY FUERTE	4 FUERTE	3 NOTABLE	2 LIMITADO	1 DÉBIL

EAWS EUROPEAN AVALANCHE WARNING SERVICES

ICGC Institut Cartogràfic i Geològic de Catalunya

Servei Meteorològic de Catalunya

Boletín de peligro de aludes Pallaresa
Del 07/02/2026 al 09/02/2026

(Válido fuera pistas de esquí y zonas no controladas)

Limitado (2) por debajo de 2400 m, Notable (3) por encima

Situación primaria

Nieve venteada

Distribución

Tamaño

Origen

Tendencia

Situación secundaria

Nieve reciente

Distribución

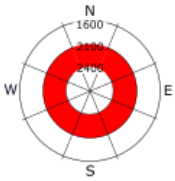

Tamaño

Origen

Tendencia

Estado del manto nivoso

Por encima de los 2300-2400 m, se han dado deflaciones, pero todavía se mantienen placas que localmente pueden dar alguna propagación destacable. Por lo general, hay placas por encima de los 2200 m, en laderas E, N y en algunas zonas S resguardadas del viento del W. Las más sensibles y frágiles están por encima de los 2400 m. Pueden caer fácilmente a nuestro paso y alcanzar tamaño suficiente para enterrar a una persona. También se pueden formar nuevas sobre escarcha recientemente formada. Además se mantiene el problema de nieve reciente que ha ido purgando de forma natural y que seguirá haciéndolo donde todavía no se haya purgado, sobre todo en momentos de claros. Se prevé pues la caída de aludes de nieve reciente de forma natural. Estos aludes serán pequeños (sin capacidad de enterrarnos) y se darán en pendientes fuertemente inclinadas. Con las débiles nevadas previstas, las placas pueden quedarse tapadas y ser difíciles de detectar.

Distribución del manto nivoso

Hay nieve desde los 1600 m. Los espesores en cotas altas y medias superan los 140-150 cm. Estos valores son superiores a los normales para la época.

Tendencia para las próximas 48-72h

Las bajas temperaturas mantendrán las placas frágiles. Peligro ESTACIONARIO.

El próximo boletín será emitido el día 2026-02-09

5 MUY FUERTE	4 FUERTE	3 NOTABLE	2 LIMITADO	1 DÉBIL

EAWS EUROPEAN AVALANCHE WARNING SERVICES

ICGC Institut Cartogràfic i Geològic de Catalunya

meteo.cat Servei Meteorològic de Catalunya

Boletín de peligro de aludes Perafita-Puigpedrós Del 07/02/2026 al 09/02/2026

(Válido fuera pistas de esquí y zonas no controladas)

Limitado (2)

Situación primaria

Nieve venteada

Distribución

Tamaño

Origen

Tendencia

Estado del manto nivoso

Por encima de los 2300-2400 m, el manto nivoso está constituido por placas que se desarrollaron el jueves a sotavento del viento del oeste. Estas placas se formaron primero con nieve fría y después, con la subida de la cota de nieve, con nieve más pesada para acabar de taparse con nieve otra vez más fría. Pueden caer a nuestro paso y alcanzar tamaño suficiente para enterrar a una persona. Se encuentran especialmente en ladera E, N y en algunas zonas S resguardadas del viento de W. Por debajo de los 2300 m el manto nivoso se ha ido agobiando y endureciendo. La nieve que pueda caer de frente puede tapar las placas existentes.

Distribución del manto nivoso

Hay nieve en el suelo por encima de 1.400-1500 m. Sin embargo, el manto es esquiable por encima de 1.500-1.600 m. Los grosores alcanzan los 130-150 cm a 2.200 m. Son grosores muy por encima de los habituales por la época.

Tendencia para las próximas 48-72h

Las bajas temperaturas mantendrán las placas frágiles. Peligro ESTACIONARIO.

El próximo boletín será emitido el día 2026-02-09

5 MUY FUERTE	4 FUERTE	3 NOTABLE	2 LIMITADO	1 DÉBIL

EAWS EUROPEAN AVALANCHE WARNING SERVICES

ICGC Institut Cartogràfic i Geològic de Catalunya

Servei Meteorològic de Catalunya meteo.cat

Boletín de peligro de aludes
Vessant Nord Cadí-Moixeró
Del 07/02/2026 al 09/02/2026

(Válido fuera pistas de esquí y zonas no controladas)

Limitado (2)

Situación primaria

Nieve venteada

Distribución

Tamaño

Origen

Tendencia

Situación secundaria

Nieve reciente

Distribución

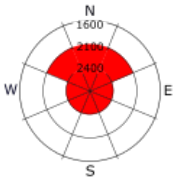

Tamaño

Origen

Tendencia

Estado del manto nivoso

Las nevadas de días pasados han dejado nieve reciente y placas de viento al abrigo del viento de componente W. Por encima de los 2300-2400 m, el manto nivoso está constituido por placas del pasado jueves a sotavento del viento del oeste. La reciente nieve caída entre la noche del viernes y la madrugada del sábado ha dejado una capa de nieve reciente (unos 10 cm a 2200 m) que puede tapar las placas existentes. Estas placas pueden caer a nuestro paso y alcanzar tamaño suficiente para enterrar a una persona. Se encuentran especialmente en laderas E, N y en algunas zonas S resguardadas del viento de W. Las nuevas placas que se formen estarán sobre escarcha. Se prevé la caída de pequeños aludes de nieve reciente en pendientes muy inclinadas, sobre todo en momentos de claros. Serán de nieve más pesada por debajo de los 2200 m. Evitad las zonas trampa: canales y zonas deprimidas donde la nieve acumulada, en caso de pequeños aludes, podría llegar a enterrarnos y causarnos daños importantes.

Distribución del manto nivoso

Hay nieve desde 1.200-1300 m. Norte y desde 1.400-1500 m. Sur, esquiable por encima de unos 1.600 m. Los grosores están alrededor de 155-165 cm a 2.200 m. Estos valores son muy excedentarios para la época del año.

Tendencia para las próximas 48-72h

Las bajas temperaturas mantendrán las placas frágiles. Peligro ESTACIONARIO.

El próximo boletín será emitido el día 2026-02-09

5 MUY FUERTE	4 FUERTE	3 NOTABLE	2 LIMITADO	1 DÉBIL

EAWS EUROPEAN AVALANCHE WARNING SERVICES

ICGC Institut Cartogràfic i Geològic de Catalunya

Servei Meteorològic de Catalunya

Boletín de peligro de aludes Prepirineu
Del 07/02/2026 al 09/02/2026

(Válido fuera pistas de esquí y zonas no controladas)

Limitado (2)

Situación primaria

Nieve venteada | **Distribución** | **Tamaño** | **Origen** | **Tendencia**

Situación secundaria

Nieve reciente | **Distribución** | **Tamaño** | **Origen** | **Tendencia**

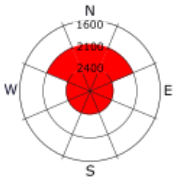

Estado del manto nivoso

Las nevadas de días pasados han dejado nieve reciente y placas de viento al abrigo del viento de componente W. Por encima de los 2300-2400 m, el manto nivoso está constituido por placas del pasado jueves a sotavento del viento del oeste. La reciente nieve caída entre la noche del viernes y la madrugada del sábado ha dejado una capa de nieve reciente (unos 10 cm a 2200 m) que puede tapar las placas existentes. Estas placas pueden caer a nuestro paso y alcanzar tamaño suficiente para enterrar a una persona. Se encuentran especialmente en laderas E, N y en algunas zonas S resguardadas del viento de W. Las nuevas placas que se formen estarán sobre escarcha. Se prevé la caída de pequeños aludes de nieve reciente en pendientes muy inclinadas, sobre todo en momentos de claros. Serán de nieve más pesada por debajo de los 2200 m. Evitad las zonas trampa: canales y zonas deprimidas donde la nieve acumulada, en caso de pequeños aludes, podría llegar a enterrarnos y causarnos daños importantes.

Distribución del manto nivoso

Hay nieve desde 1400-1500 m. El manto es esquiable a partir de 1600 m. Los grosores están alrededor de 110-130 cm a unos 2.200 my son superiores a los habituales.

Tendencia para las próximas 48-72h

Las bajas temperaturas mantendrán las placas frágiles. Peligro ESTACIONARIO.

El próximo boletín será emitido el día 2026-02-09

5 MUY FUERTE	4 FUERTE	3 NOTABLE	2 LIMITADO	1 DÉBIL

EAWS EUROPEAN AVALANCHE WARNING SERVICES

ICGC Institut Cartogràfic i Geològic de Catalunya

Servei Meteorològic de Catalunya

Boletín de peligro de aludes Ter-Freser Del 07/02/2026 al 09/02/2026

(Válido fuera pistas de esquí y zonas no controladas)

Limitado (2)

Situación primaria

Nieve venteada

Distribución

Tamaño

Origen

Tendencia

Estado del manto nivoso

Por encima de los 2300-2400 m, el manto nivoso está muy venteado. Aún así, hay placas de viento que se desarrollaron el jueves a sotavento del viento fuerte de componente oeste. Estas placas se formaron primero con nieve fría y después, con la subida de la cota de nieve, con nieve más pesada para acabar de taparse, en sectores muy resguardados del viento, con nieve otra vez más fría. Pueden caer a nuestro paso y alcanzar tamaño suficiente para enterrar a una persona. Se encuentran especialmente en laderas E, N y en algunas zonas S resguardadas del viento de W. Por debajo de los 2300 m el manto nivoso se ha ido endureciendo. Las placas existentes pueden verse tapadas localmente por una fina capa de nieve reciente.

Distribución del manto nivoso

El manto nivoso presenta grosores muy excedentarios para la época del año. En lugares no afectados por el viento, los espesores oscilan entre 100-140 cm a unos 2.000 m, siendo esquiable a partir de unos 1.500 m.

Tendencia para las próximas 48-72h

Las bajas temperaturas mantendrán las placas frágiles. Peligro ESTACIONARIO.

El próximo boletín será emitido el día 2026-02-09

5 MUY FUERTE	4 FUERTE	3 NOTABLE	2 LIMITADO	1 DÉBIL

EAWS EUROPEAN AVALANCHE WARNING SERVICES