MINISTERO DELLA DIFESA

meteomont
Servizio Nazionale di previsione neve e valanghe

EAWS EUROPEAN AVALANCHE WARNING SERVICES

CARABINIERI

ALPI CARNICHE OCCIDENTALI

Bollettino Valanghe N. 338/2026 del 07/02/2026 ore 14.00
Validità 48 ore prossima emissione 08/02/2026

A cura del Servizio METEOMONT dell'ARMA dei CARABINIERI
In collaborazione con Servizio Meteorologico dell'Aeronautica militare

SITUAZIONE alle 14:00 del 07/02/2026

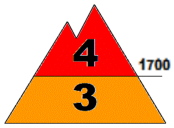

SITUAZIONE TIPO: neve a debole coesione e vento.



SITUAZIONE TIPO: situazione primaverile.

Quota neve (mslm)	Nord	Sud
	500	500

Altezza Neve (cm)	Neve al suolo	Neve Fresca	Quota (mslm)
	107	1	1728
	74	0	1425

VALANGHE OSSERVATE: Numerose valanghe di medie dimensioni, Valanghe a lastroni di superficie.

PREVISIONI 08/02/2026

GRADO DI PERICOLO: FORTE 4

SITUAZIONE TIPO: neve a debole coesione e vento.

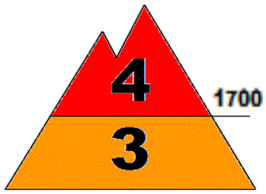

SITUAZIONE TIPO: situazione primaverile.

MANTO NEVOSO: La stabilità del manto nevoso è molto scarsa su molti punti (aree) per tutte le esposizioni al di sopra di 1700 mslm, possibili valanghe di dimensioni grandi.
La stabilità del manto nevoso è molto scarsa su molti punti (aree) per tutte le esposizioni al di sotto di 1700 mslm, possibili valanghe di dimensioni medie.

AVVERTENZE

In considerazione dei recenti apporti di neve fresca, è richiesta un'ottima valutazione locale della stabilità ed individuazione dell'itinerario.

SCALA EUROPEA DEL GRADO DI PERICOLO VALANGHE

LEGENDA PROBLEMA

Bollettino realizzato su scala sinottica-regionale (standard EAWS). La sua valutazione non può escludere in alcun modo la necessità di una seria e capace valutazione locale del pericolo (singolo pendio) che può essere anche sensibilmente diverso. Le previsioni meteorologiche sono relative all'orario UTC (per l'Italia +1 in inverno e +2 in estate).

Bollettino sottoposto a processi di: Acquisizione e controllo del C-Sifa e della rete di Osservatori e Esperti - Validazione del Previsore di turno - Certificazione della Sezione Meteomont.

MINISTERO DELLA DIFESA

meteomont
Servizio Nazionale di previsione neve e valanghe

EAWS EUROPEAN AVALANCHE WARNING SERVICES

CARABINIERI

ALPI CARNICHE OCCIDENTALI

PREVISIONE METEO

Quota		08/02/2026 h6:00	08/02/2026 h12:00	08/02/2026 h18:00
1000	Venti	00 Calma	00 Calma	01 Nodi da Est
	Temperature	-01 °C	-01 °C	-01 °C
	Temp.percepita	-1 °C	-1 °C	-1 °C
2000	Venti	00 Calma	01 Nodi da S-Ovest	00 Calma
	Temperature	-03 °C	-03 °C	-03 °C
	Temp.percepita	-3 °C	-3 °C	-3 °C
3000	Venti	01 Nodi da Ovest	01 Nodi da S-Ovest	02 Nodi da S-Ovest
	Temperature	-09 °C	-10 °C	-09 °C
	Temp.percepita	-9 °C	-10 °C	-9 °C
Zero termico		1200-1400 m.	1500-1700 m.	1400-1600 m.
Fenomeno		—	—	—
Stato del cielo				

LEGENDA FENOMENI

— Assenza Fenomeni
Nebbia
Foschia
Pioggia debole
Pioggia moderata
Pioggia forte
Temporali
Nevicata debole
Nevicata moderata
Nevicata forte

STATO DEL CIELO

Sereno
Poco nuvoloso
Nuvoloso
Molto nuvoloso
Coperto

Parametri meteonivometrici registrati presso i campi di rilevamento il 07/02/2026.

Località	Comune	Quota (m.s.l.m.)	Altezza neve (cm)	Neve caduta nelle 24 ore (cm)	Temp. Min (°C)	Temp. Max (°C)	Condizioni del tempo
MALGA VARMOST	Forni di Sopra (UD)	1728	107	1	N.P.	N.P.	Nevicata moderata
SAURIS DI SOPRA	Sauris (UD)	1425	74	0	+0	+13	Assenza di precipitazioni

(*) Rilievi fuori campo

L'INFORMAZIONE E' PREVENZIONE - LEGGI L'ATTUALE GRADO DI PERICOLO VALANGHE!

IL CAPO DEL CENTRO NAZIONALE METEOMONT
(Ten. Col. RFI Emanuela Gini)
FIRMA AUTOGRAFA OMESSA AI SENSI
DELL'ART.3 DEL D.LGS N.39/1993