MINISTERO DELLA DIFESA

meteomont
Servizio Nazionale di previsione neve e valanghe

EAWS EUROPEAN AVALANCHE WARNING SERVICES

CARABINIERI

AERONAUTICA MILITARE SERVIZIO METEOROLOGICO

ALPI RETICHE

Bollettino Valanghe N. 339/2026 del 06/02/2026 ore 14.00
Validità 48 ore prossima emissione 07/02/2026

A cura del Servizio METEOMONT dell'ARMA dei CARABINIERI
In collaborazione con Servizio Meteorologico dell'Aeronautica militare

SITUAZIONE alle 14:00 del 06/02/2026

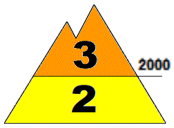

SITUAZIONE TIPO: brina di superficie sepolta.



SITUAZIONE TIPO: brina di superficie sepolta.

Quota neve (mslm)	Nord	Sud
	700 - 900	700 - 1000

Altezza Neve (cm)	Neve al suolo	Neve Fresca	Quota (mslm)
	57	1	2150
	64	3	1640

VALANGHE OSSERVATE: Nessuna valanga.

PREVISIONI 07/02/2026

GRADO DI PERICOLO: MARCATO 3

SITUAZIONE TIPO: brina di superficie sepolta.

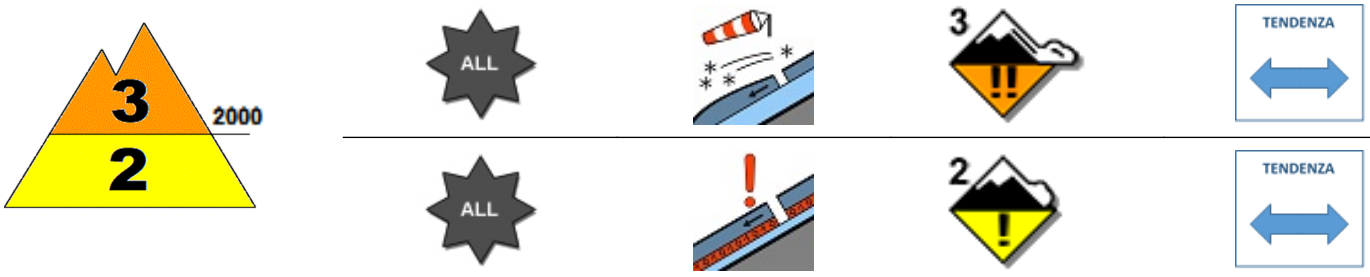

SITUAZIONE TIPO: brina di superficie sepolta.

MANTO NEVOSO: La stabilità del manto nevoso è molto scarsa su molti punti (aree) per tutte le esposizioni al di sopra di 2000 mslm, possibili valanghe di dimensioni medie.
La stabilità del manto nevoso è scarsa su molti punti (aree) per tutte le esposizioni al di sotto di 2000 mslm, possibili valanghe di dimensioni piccole.

AVVERTENZE

In considerazione dei recenti apporti di neve fresca, è richiesta una buona valutazione locale della stabilità ed individuazione dell'itinerario.

SCALA EUROPEA DEL GRADO DI PERICOLO VALANGHE

5 - MOLTO FORTE | 4 - FORTE | 3 - MARCATO | 2 - MODERATO | 1 - DEBOLE | NO NEVE | NO INFO

LEGENDA PROBLEMA

NEVE FRESCA | LASTRONI DA VENTO | STRATI DEBOLI PERSISTENTI | NEVE BAGNATA | SLITTAMENTO | CORNICI | NESSUN PROBLEMA VALANGHIVO EVIDENTE | NO_INFO

Bollettino realizzato su scala sinottica-regionale (standard EAWS). La sua valutazione non può escludere in alcun modo la necessità di una seria e capace valutazione locale del pericolo (singolo pendio) che può essere anche sensibilmente diverso. Le previsioni meteorologiche sono relative all'orario UTC (per l'Italia +1 in inverno e +2 in estate).

MINISTERO DELLA DIFESA

meteomont
Servizio Nazionale di previsione neve e valanghe

EAWS EUROPEAN AVALANCHE WARNING SERVICES

CARABINIERI

ALPI RETICHE

PREVISIONE METEO

Quota		07/02/2026 h6:00	07/02/2026 h12:00	07/02/2026 h18:00
1000	Venti	01 Nodi da Nord	00 Calma	01 Nodi da N-Est
	Temperature	-03 °C	-02 °C	-02 °C
	Temp.percepita	-3 °C	-2 °C	-2 °C
2000	Venti	01 Nodi da Nord	00 Calma	01 Nodi da N-Est
	Temperature	-03 °C	-02 °C	-02 °C
	Temp.percepita	-3 °C	-2 °C	-2 °C
3000	Venti	00 Calma	01 Nodi da Est	01 Nodi da Nord
	Temperature	-09 °C	-09 °C	-08 °C
	Temp.percepita	-9 °C	-9 °C	-8 °C
Zero termico		1500-1700 m.	1600-1800 m.	1600-1800 m.
Fenomeno		—	—	—
Stato del cielo				

LEGENDA FENOMENI

— Assenza Fenomeni · Nebbia · Foschia · Pioggia debole · Pioggia moderata · Pioggia forte · Temporali

Nevicata debole · Nevicata moderata · Nevicata forte

STATO DEL CIELO

Sereno · Poco nuvoloso · Nuvoloso · Molto nuvoloso · Coperto

Parametri meteonivometrici registrati presso i campi di rilevamento il 06/02/2026.

Località	Comune	Quota (m.s.l.m.)	Altezza neve (cm)	Neve caduta nelle 24 ore (cm)	Temp. Min (°C)	Temp. Max (°C)	Condizioni del tempo
SPONDA	Livigno (SO)	2150	57	1	-7	+5	Nevicata debole intermittente
BORMIO2000-LECCIONA	Valdisotto (SO)	2050	61	1	-3	+2	Assenza di precipitazioni
DOSSO DEL VALLONE	Valfurva (SO)	2582	58	2	-9	+4	Nevicata debole intermittente
SANTA APOLLONIA	Vezza d'Oglio (BS)	1599	33	2	N.P.	N.P.	Nevicata moderata
PREDA	Edolo (BS)	1580	41	2	-2	+2	Nevicata moderata
COLONIA VIGILI	Ponte di Legno (BS)	1640	64	3	-3	+5	Nevicata debole continua
PIZZO BELTOVO DI FUORI *	Stelvio (BZ)	3161	136	3	N.P.	N.P.	Assenza di precipitazioni
PISTA STELVIO *	Valdisotto (SO)	2268	60	2	N.P.	N.P.	Nevicata debole continua

(*) Rilievi fuori campo

L'INFORMAZIONE E' PREVENZIONE - LEGGI L'ATTUALE GRADO DI PERICOLO VALANGHE!

IL CAPO DEL CENTRO NAZIONALE METEOMONT
(Ten. Col. RFI Emanuela Gini)
FIRMA AUTOGRAFA OMESSA AI SENSI
DELL'ART.3 DEL D.LGS N.39/1993

Bollettino realizzato su scala sinottica-regionale (standard EAWS). La sua valutazione non può escludere in alcun modo la necessità di una seria e capace valutazione locale del pericolo (singolo pendio) che può essere anche sensibilmente diverso. Le previsioni meteorologiche sono relative all'orario UTC (per l'Italia +1 in inverno e +2 in estate).