MINISTERO DELLA DIFESA

meteomont
Servizio Nazionale di previsione neve e valanghe

EAWS EUROPEAN AVALANCHE WARNING SERVICES

CARABINIERI

MAINARDE-ALTO MOLISE

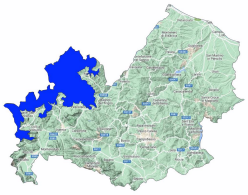

Bollettino Valanghe N. 287/2026 del 06/02/2026 ore 14.00
Validità 48 ore prossima emissione 07/02/2026

A cura del Servizio METEOMONT dell'ARMA dei CARABINIERI
In collaborazione con Servizio Meteorologico dell'Aeronautica militare

SITUAZIONE alle 14:00 del 06/02/2026

SITUAZIONE TIPO: pioggia su neve.

Quota neve (mslm)	Nord	Sud
	1600 - 1700	1700 - 1800

Altezza Neve (cm)	Neve al suolo	Neve Fresca	Quota (mslm)
	010	000	1600

VALANGHE OSSERVATE: -.

PREVISIONI 07/02/2026

GRADO DI PERICOLO: DEBOLE 1

SITUAZIONE TIPO: nessuna situazione tipo evidente.



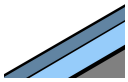

MANTO NEVOSO: La stabilità del manto nevoso è discreta su pochi punti (aree) per isolati pendii, possibili valanghe di dimensioni medie.

AVVERTENZE

In considerazione delle avverse condizioni meteorologiche in atto, e della scarsa visibilità, risulterà difficoltosa l'individuazione dell'itinerario e della valutazione del singolo pendio.

SCALA EUROPEA DEL GRADO DI PERICOLO VALANGHE

LEGENDA PROBLEMA

Bollettino realizzato su scala sinottica-regionale (standard EAWS). La sua valutazione non può escludere in alcun modo la necessità di una seria e capace valutazione locale del pericolo (singolo pendio) che può essere anche sensibilmente diverso. Le previsioni meteorologiche sono relative all'orario UTC (per l'Italia +1 in inverno e +2 in estate).

MINISTERO DELLA DIFESA

meteomont
Servizio Nazionale di previsione neve e valanghe

EAWS EUROPEAN AVALANCHE WARNING SERVICES

CARABINIERI

MAINARDE-ALTO MOLISE

PREVISIONE METEO

Quota		07/02/2026 h6:00	07/02/2026 h12:00	07/02/2026 h18:00
1000	Venti	05 Nodi da Ovest	04 Nodi da Ovest	03 Nodi da Ovest
	Temperature	+03 °C	+04 °C	+04 °C
	Temp.percepita	0 °C	2 °C	3 °C
2000	Venti	14 Nodi da Ovest	13 Nodi da Ovest	11 Nodi da Ovest
	Temperature	-02 °C	-02 °C	-01 °C
	Temp.percepita	-9 °C	-8 °C	-7 °C
3000	Venti	15 Nodi da Ovest	20 Nodi da Ovest	14 Nodi da Ovest
	Temperature	-04 °C	-06 °C	-07 °C
	Temp.percepita	-11 °C	-15 °C	-15 °C
Zero termico		1600-1800 m.	1700-1900 m.	1700-1900 m.
Fenomeno			—	
Stato del cielo				

LEGENDA FENOMENI

Assenza Fenomeni — Nebbia — Foschia — Pioggia debole — Pioggia moderata — Pioggia forte — Temporali

Nevicata debole — Nevicata moderata — Nevicata forte

STATO DEL CIELO

Sereno — Poco nuvoloso — Nuvoloso — Molto nuvoloso — Coperto

Parametri meteonivometrici registrati presso i campi di rilevamento il 06/02/2026.

Località	Comune	Quota (m.s.l.m.)	Altezza neve (cm)	Neve caduta nelle 24 ore (cm)	Temp. Min (°C)	Temp. Max (°C)	Condizioni del tempo
PRATO GENTILE	Capracotta (IS)	1490	0	0	+1	+7	Pioggia debole intermittente
PESCOPENNATARO	Pescopennataro (IS)	1220	0	0	+3	+11	Assenza di precipitazioni

(*) Rilievi fuori campo

L'INFORMAZIONE E' PREVENZIONE - LEGGI L'ATTUALE GRADO DI PERICOLO VALANGHE!

IL CAPO DEL CENTRO NAZIONALE METEOMONT
(Ten. Col. RFI Emanuela Gini)
FIRMA AUTOGRAFA OMESSA AI SENSI
DELL'ART.3 DEL D.LGS N.39/1993