Bulletin d'estimation du risque d'avalanche

(valable en dehors des pistes balisées et ouvertes)

MASSIF : Renoso Incudine

Rédigé le samedi 7 février 2026 à 15h

Estimation des risques pour le : DIMANCHE 08 FÉVRIER

NOUVELLES CHUTES DE NEIGE AVEC FORMATION DE PLAQUES EN ALTITUDE

3

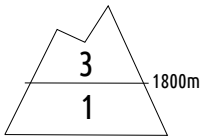

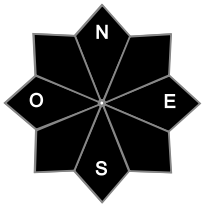

Au-dessus de 1800m indice de risque marqué, plus bas indice faible.

Départs spontanés : Avalanches de neige fraîche

Déclenchements provoqués : Plaques en altitude

Indices de risque : 5 très fort - 4 fort - 3 marqué - 2 limité - 1 faible -- En noir : les pentes les plus dangereuses

Stabilité du manteau neigeux

Situation avalancheuse typique : neige fraîche couche fragile persistante

Déclenchements provoqués : au-dessus de 1800 m, des plaques en place dans l'épaisse couche de neige récente sont présentes en toutes orientations. Ces plaques se situent souvent dans des pentes ombragées, parfois loin des crêtes. De plus, le fort vent d'Ouest a formé de nouvelles plaques durant les récentes chutes de neige, principalement dans les pentes orientées Nord à Est. Faciles à déclencher par un seul skieur, toutes plaques pourraient générer des avalanches de taille moyenne à grande. En dessous de 1800 m, les pluies des jours précédents ont contribué à stabiliser le manteau. Les plaques formées par la suite sont généralement peu épaisses et assez difficiles à solliciter.

Départs spontanés : les chutes de neige se poursuivent ce dimanche. Au fil des heures, la neige s'accumule et des coulée et quelques avalanches de taille moyenne sont attendues.

Qualité de la neige

Qualification de l'enneigement : l'enneigement est excellent pour la saison à toutes altitudes, avec des cumuls de neige récente atteignant ponctuellement 40 à 60 cm en moyenne montagne et plus de 2 mètres dans les combes abritées.

Limite d'enneigement skiable : 1400 à 1500 m.

État de la neige : la neige récente est encore sèche et plutôt légère, localement humidifiée ou croûtée en dessous de 1800 m. Le vent soutenu rend l'enneigement toujours très hétérogène. La neige est froide et poudreuse à l'abri du vent, elle devient plus compacte, voire cartonnée dans les secteurs ventés. Des anciennes surfaces, souvent dures et glacées, réapparaissent près des crêtes.

Aperçu météo pour le dimanche 08 février

	nuit	matin	après-midi	soir
Poursuite d'un temps perturbé, encore assez venteux dans cette nuit.				
Pluie-Neige	1 500 m	1 500 m	1 500 m	1 500 m
Iso 0 °C	1 900 m	1 900 m	1 900 m	1 800 m
Vent 1500 m	→ 50 km/h	↖ 20 km/h	← 25 km/h	← 20 km/h
Vent 2000 m	→ 55 km/h	↖ 30 km/h	↑ 40 km/h	↗ 25 km/h

Épaisseur de neige hors-piste

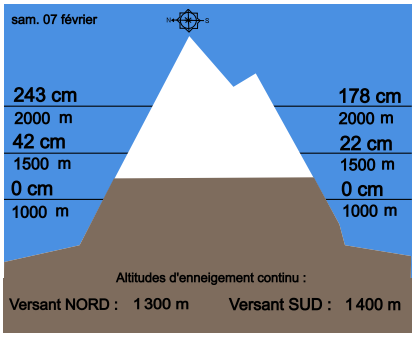

Précipitations à 1800 m

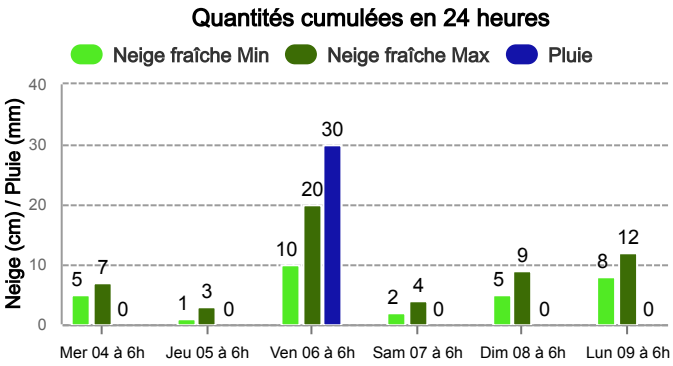

Tendance du lundi 09 février

3

Indice de risque marqué

Poursuite d'un temps perturbé. Pas d'évolution notable en termes de risque.

Pour consulter la vigilance en cours, veuillez vous rendre sur le site https://vigilance.meteofrance.fr/fr

Météo-France - 73 avenue de Paris, 94165 Saint-Mandé cedex - Contact : contact@meteo.fr

Rédigé par Météo-France avec la contribution des observateurs du réseau nivo-météorologiques. Partenariat : ANMSM (Maires de Stations de Montagne), DSF (Domaines Skiables de France), ADSP (Directeurs de Pistes et de la Sécurité des Stations de Sports d'Hiver) et autres acteurs de la montagne.

Bulletin neige & avalanches par téléphone au

0 892 68 10 20 Service 0,35 € / min + prix appel

RÉPUBLIQUE FRANÇAISE
Liberté Égalité Fraternité

METEO FRANCE
À VOS CÔTÉS, DANS UN CLIMAT QUI CHANGE

Bulletin d'estimation du risque d'avalanche

(valable en dehors des pistes balisées et ouvertes)

MASSIF : Renoso Incudine

Rédigé le samedi 7 février 2026 à 15h

Conditions nivo-météo des 7 derniers jours

	dim. 01/02				lun. 02/02				mar. 03/02				mer. 04/02				jeu. 05/02				ven. 06/02				sam. 07/02			
	03h	09h	15h	21h	03h	09h	15h	21h	03h	09h	15h	21h	03h	09h	15h	21h	03h	09h	15h	21h	03h	09h	15h	21h	03h	09h	15h	21h
Météo																												
Vent (km/h)	35	25	30	30	40	25	25	30	55	45	10	20	15	60	40	20	30	60	45	70	85	70	60	45	55	55	65	50
à 2000m	↓	↘	↘	↘	→	→	↗	↑	↗	→	↑	←	↗	↘	→	↑	→	→	→	→	→	→	→	→	→	↗	→	→
Vent (km/h)	30	20	20	20	40	20	20	25	35	35	10	15	20	50	30	10	25	40	35	55	95	80	75	60	60	45	65	50
à 1500m	↘	↘	↘	↘	→	→	↗	↑	↑	→	↑	↓	↗	→	→	↗	→	→	↗	↗	→	→	→	→	→	→	→	→

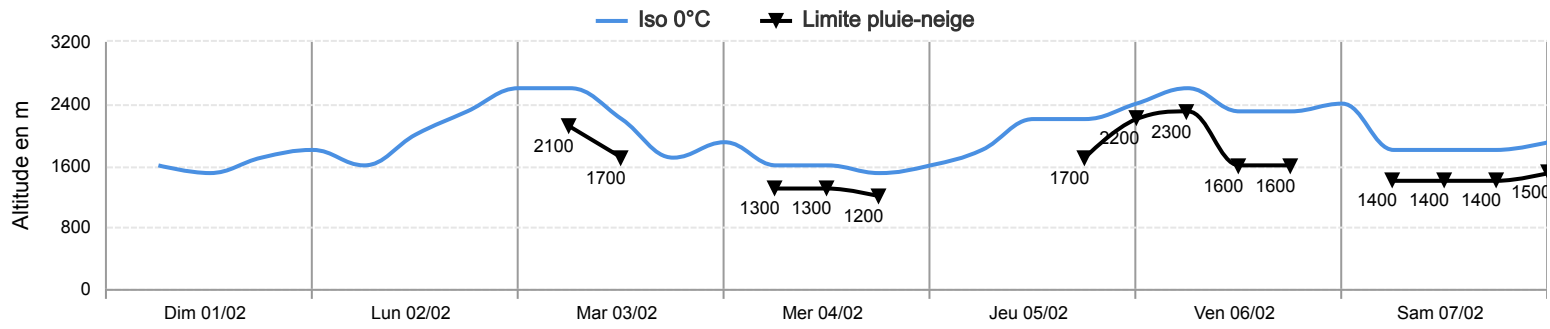

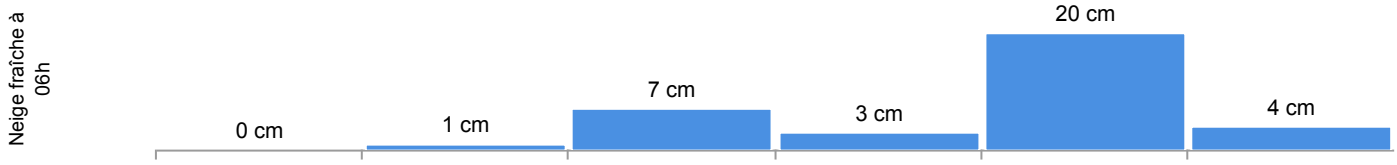

Risque d'avalanche							
	dim. 01/02	lun. 02/02	mar. 03/02	mer. 04/02	jeu. 05/02	ven. 06/02	sam. 07/02

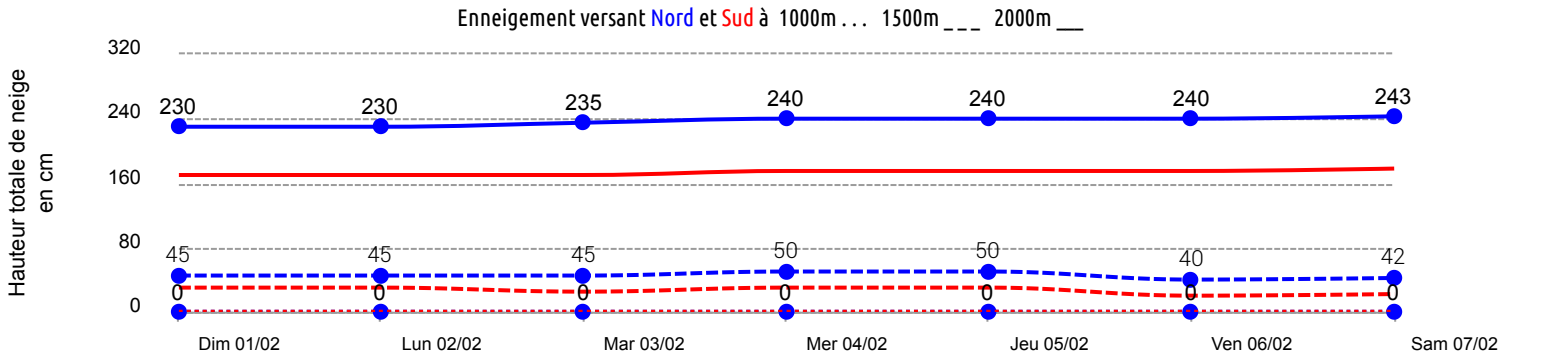

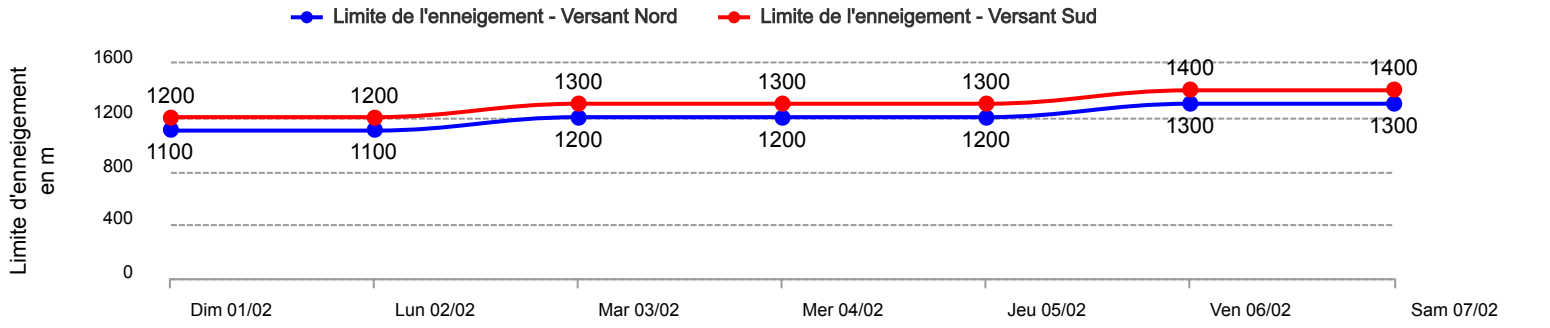

Pour consulter la vigilance en cours, veuillez vous rendre sur le site https://vigilance.meteofrance.fr/fr

Météo-France - 73 avenue de Paris, 94165 Saint-Mandé cedex - Contact : contact@meteo.fr

Rédigé par Météo-France avec la contribution des observateurs du réseau nivo-météorologiques. Partenariat : ANMSM (Maires de Stations de Montagne), DSF (Domaines Skiables de France), ADSP (Directeurs de Pistes et de la Sécurité des Stations de Sports d'Hiver) et autres acteurs de la montagne.

Bulletin neige & avalanches par téléphone au
0 892 68 10 20 Service 0,35 € / min + prix appel