Bulletin d'estimation du risque d'avalanche
(valable en dehors des pistes balisées et ouvertes)

MASSIF : Bauges

Rédigé le samedi 7 février 2026 à 16h

Estimation des risques pour le : DIMANCHE 08 FÉVRIER

INSTABILITÉS DANS LA NEIGE RÉCENTE.

2

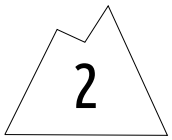

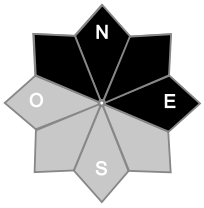

Indice de risque limité.

Départs spontanés : Petits départs au fil du réchauffement diurne.

Déclenchements provoqués : Plaques friables dans la neige récente.

Indices de risque : 5 très fort - 4 fort - 3 marqué - 2 limité - 1 faible -- En noir : les pentes les plus dangereuses

Stabilité du manteau neigeux

Situation avalancheuse typique : neige ventée

Déclenchements provoqués :
Au-dessus de 1800 m : **plaques friables dans la neige récente**. Formées lors des chutes de ces derniers jours par le **vent de secteur Sud à Ouest**. Peu nombreuses mais réactives au passage d'un·e skieur·euse. Cassure de 10-30 cm d'épaisseur. Taille 1 (petite) à 2 (moyenne).
Observables : changements de densité de neige, irrégularités d'épaisseur du manteau neigeux, fissures devant les skis ...

Départs spontanés :
* Petits départs ponctuels dans les pentes raides. Principalement près des rochers/falaises et au fil du réchauffement diurne. Taille 1 (petite) à 2 (moyenne). Ces petits départs peuvent déclencher une plaque friable.
* Rares plaques de fond. Départs possibles à toute heure du jour et de la nuit. Départs plus probables dans les faces exposées au soleil. Taille 1 (petite) à 2 (moyenne).

Qualité de la neige

Enneigement : un peu déficitaire. On peut chausser les skis ou raquettes vers 1000 m environ (plutôt 1200 m en versants S). Peu de sous-couche sous 1500 m. Cailloux vers les crêtes peu enneigées.

Qualité de la neige ce dimanche :
* En-dessous de 1700/1800 m : le matin, la surface de la neige est regelée. La croûte est plus ou moins portante (plus dure à basse altitude, notamment sous 1300/1500 m). Au fil de la journée, la neige se ramollit légèrement en surface, surtout dans les versants ensoleillés.
* Au-dessus de 1700/1800 m : couche de neige récente restée froide et assez légère (7-15 cm). Elle repose sur une surface plus durcie par le travail du vent de secteur Sud à Ouest de ces derniers jours ou par le regel.

Aperçu météo pour le dimanche 08 février

nuit	matin	après-midi	soir

Le ciel se couvre au fil de la journée. Le vent est faible. Doux pour la saison.

Pluie-Neige				
Iso 0 °C	1 800 m	1 800 m	1 800 m	1 700 m
Vent 1500 m	10 km/h	15 km/h	5 km/h	5 km/h
Vent 2000 m	15 km/h	20 km/h	10 km/h	10 km/h

Épaisseur de neige hors-piste

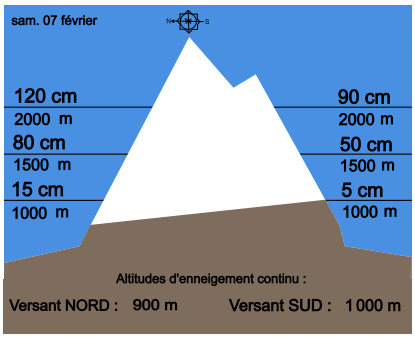

Précipitations à 1800 m

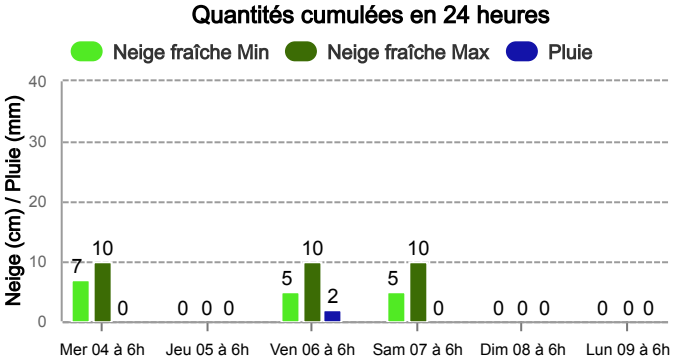

Tendance du lundi 09 février

2

Indice de risque limité

Les plaques friables dans la neige récente se stabilisent progressivement. Nombreux passages nuageux sur la journée de lundi. Le vent reste assez faible.

Pour consulter la vigilance en cours, veuillez vous rendre sur le site https://vigilance.meteofrance.fr/fr

Météo-France - 73 avenue de Paris, 94165 Saint-Mandé cedex - Contact : contact@meteo.fr

Rédigé par Météo-France avec la contribution des observateurs du réseau nivo-météorologiques. Partenariat : ANMSM (Maires de Stations de Montagne), DSF (Domaines Skiables de France), ADSP (Directeurs de Pistes et de la Sécurité des Stations de Sports d'Hiver) et autres acteurs de la montagne.

Bulletin neige & avalanches par téléphone au
0 892 68 10 20 Service 0,35 € / min + prix appel

RÉPUBLIQUE FRANÇAISE
Liberté Égalité Fraternité

METEO FRANCE
À VOS CÔTÉS, DANS UN CLIMAT QUI CHANGE

Bulletin d'estimation du risque d'avalanche

(valable en dehors des pistes balisées et ouvertes)

MASSIF : Bauges

Rédigé le samedi 7 février 2026 à 16h

Conditions nivo-météo des 7 derniers jours

	dim. 01/02				lun. 02/02				mar. 03/02				mer. 04/02				jeu. 05/02				ven. 06/02				sam. 07/02			
	03h	09h	15h	21h	03h	09h	15h	21h	03h	09h	15h	21h	03h	09h	15h	21h	03h	09h	15h	21h	03h	09h	15h	21h	03h	09h	15h	21h
Météo																												
Vent (km/h)	15	10	20	30	30	40	50	55	55	45	35	30	20	20	25	35	30	30	30	25	30	30	25	20	20	10	10	10
à 2000m																												
Vent (km/h)	10	5	10	15	20	25	30	30	40	35	25	20	10	10	15	25	20	20	20	20	25	25	20	10	10	5	5	5
à 1500m																												

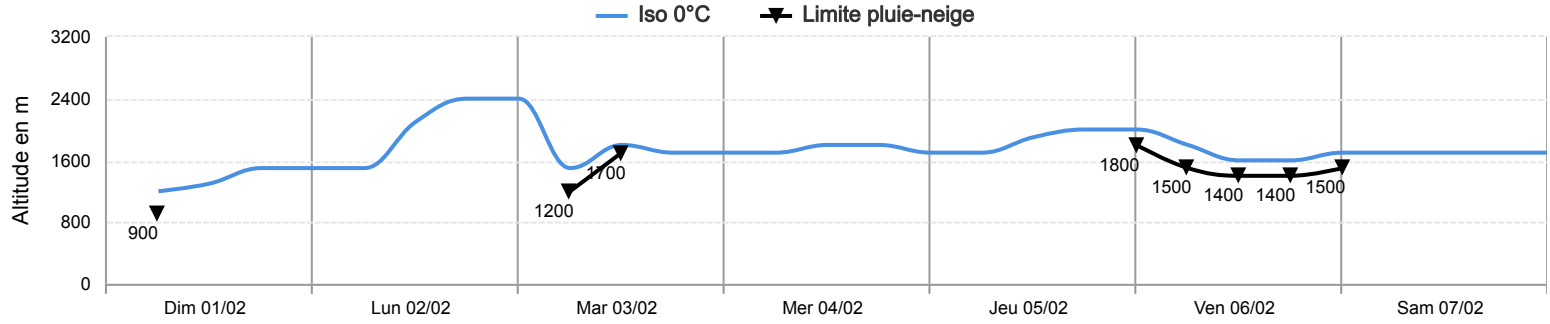

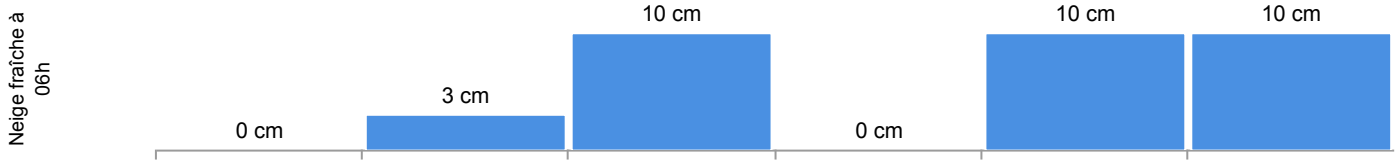

Risque d'avalanche	dim. 01/02	lun. 02/02	mar. 03/02	mer. 04/02	jeu. 05/02	ven. 06/02	sam. 07/02
	2	2	3	3	3	3	2

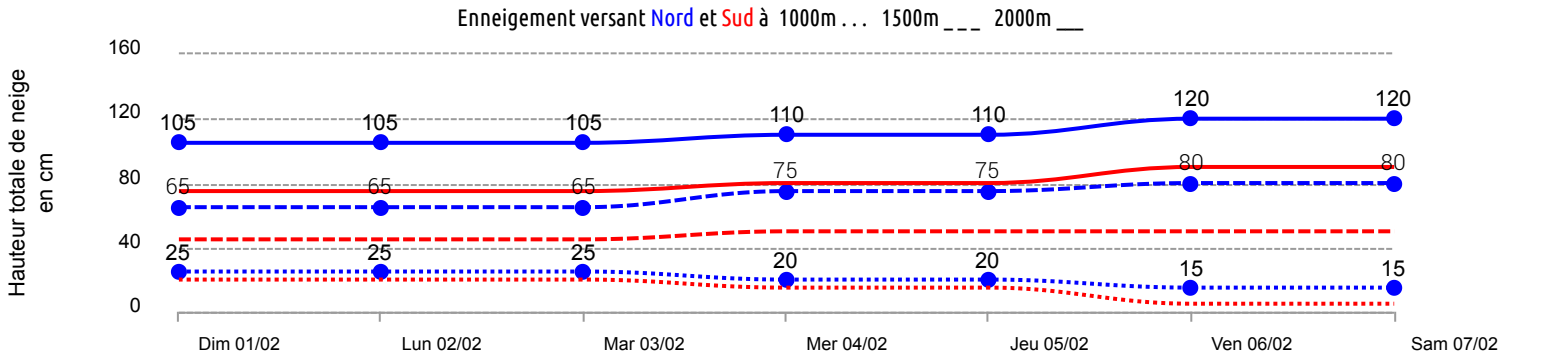

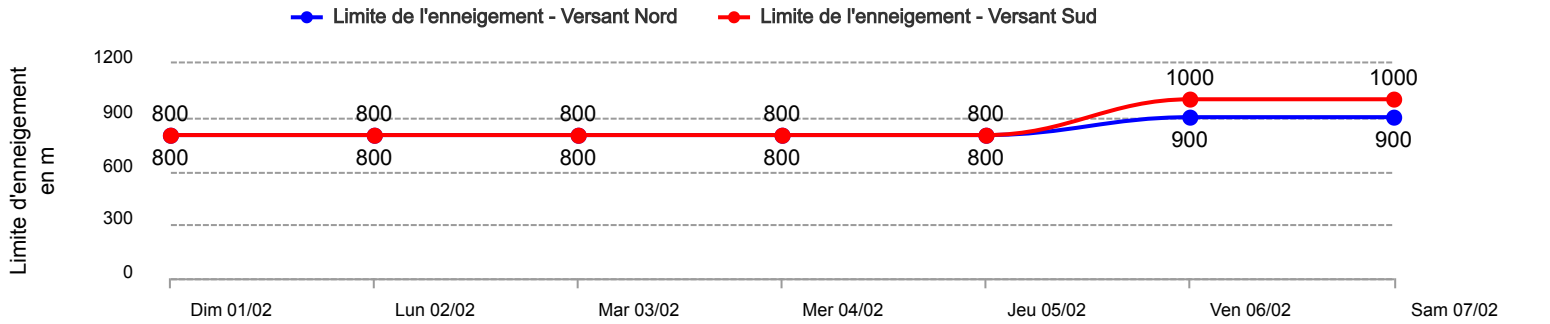

Pour consulter la vigilance en cours, veuillez vous rendre sur le site https://vigilance.meteofrance.fr/fr

Météo-France - 73 avenue de Paris, 94165 Saint-Mandé cedex - Contact : contact@meteo.fr

Rédigé par Météo-France avec la contribution des observateurs du réseau nivo-météorologiques. Partenariat : ANMSM (Maires de Stations de Montagne), DSF (Domaines Skiables de France), ADSP (Directeurs de Pistes et de la Sécurité des Stations de Sports d'Hiver) et autres acteurs de la montagne.

Bulletin neige & avalanches par téléphone au

0 892 68 10 20 Service 0,35 € / min + prix appel