RÉPUBLIQUE FRANÇAISE
Liberté Égalité Fraternité

METEO FRANCE
À VOS CÔTÉS, DANS UN CLIMAT QUI CHANGE

Bulletin d'estimation du risque d'avalanche
(valable en dehors des pistes balisées et ouvertes)

MASSIF : Cerdagne Canigou

Rédigé le samedi 7 février 2026 à 16h

Estimation des risques pour le : DIMANCHE 08 FÉVRIER

PERSISTANCE DE QUELQUES INSTABILITÉS EN ALTITUDE

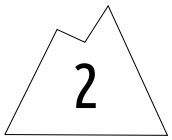

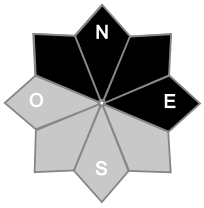

Indice de risque limité.

Départs spontanés : Ponctuellement, en fin de nuit ou matinée, coulées en neige humide en dessous de 2000 m, ou avalanches de glissement pentes raides et herbeuses au soleil.

Déclenchements provoqués : Plaques à vent juste sous les crêtes frontalièères, déclenchables surtout en haute montagne.

Indices de risque : 5 très fort - 4 fort - 3 marqué - 2 limité - 1 faible -- En noir : les pentes les plus dangereuses

Stabilité du manteau neigeux

Situation avalancheuse typique : neige ventée neige humide

Déclenchements provoqués :
* Au-dessus de 2200/2300 m, dans les orientations nord-ouest à est, déclenchements possibles d'avalanches de taille moyenne (T2), voire de grande taille (T3) dans les secteurs les plus défavorables de haute montagne (secteur Orlu). En effet, des structures de plaques pas complètement stabilisées peuvent encore être présentes, principalement sous les crêtes chargées dernièrement par le vent de sud ouest.
Ces accumulations en neige souvent dure ou cartonnée, peuvent céder au passage d'un randonneur dans les pentes raides (observables : neige sèche et cartonnée en surface, bruits d'effondrement au sein du manteau neigeux ou fissures qui se propagent devant les skis).
* Plus bas et dans les expositions bien ensoleillées, là où croûtes de regel et neige bien humidifiée prédominent en surface, le risque de départ accidentel est faible.

Départs spontanés :
Plutôt en fin de nuit et matinée.
* Avalanches de glissement possibles en pentes très raides herbeuses ou sur des dalles rocheuses, surtout au soleil et en dessous de 2000 m (Taille 1 ou 2). (observables : présence de gueules de baleine, reptations, neige dense et très humide).
* Départs ponctuels en surface (tailles1 voire 2) en neige humide au soleil.

Qualité de la neige

Enneigement :
L'enneigement est excellent et nettement excédentaire pour la saison. La limite de skiabillité se situe vers 1300/1400 m dans les meilleures configurations.

État de la neige :
Au petit matin, neige dure et portante en dessous de 2000 m environ, voire jusqu'en haute montagne dans les expositions raides exposées en journée au soleil. Neige froide encore présente au-delà de 2100/2200 m à l'ombre ou dans les vallons froids d'altitude.
Dégel quasi nul en journée dans les versants ombragés, neige de printemps meuble dans les pentes raides profitant des éclaircies, apport de quelques centimètres de neige récente en fin de journée et nuit suivante.

Aperçu météo pour le dimanche 08 février

	nuit	matin	après-midi	soir

Un peu de neige en moyenne montagne en fin de journée.

Pluie-Neige			1 400 m	
Iso 0 °C	2 200 m	2 000 m	1 800 m	1 800 m
Vent 2000 m	45 km/h	40 km/h	35 km/h	25 km/h
Vent 3000 m	55 km/h	50 km/h	50 km/h	40 km/h

Épaisseur de neige hors-piste

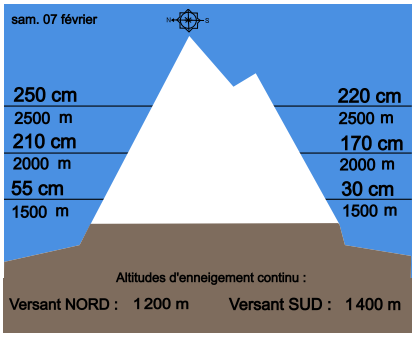

Précipitations à 1800 m

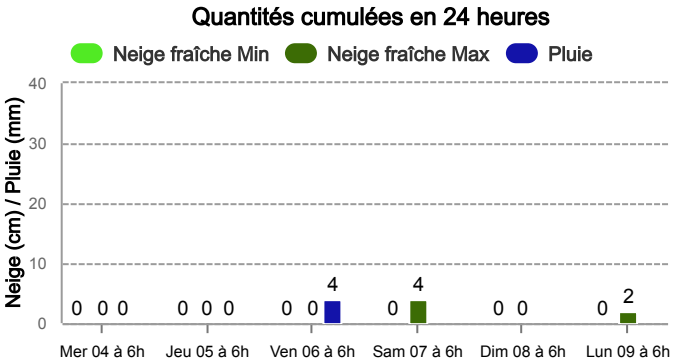

Tendance du lundi 09 février

Indice de risque limité

Stationnaire.

Pour consulter la vigilance en cours, veuillez vous rendre sur le site https://vigilance.meteofrance.fr/fr

Météo-France - 73 avenue de Paris, 94165 Saint-Mandé cedex - Contact : contact@meteo.fr

Rédigé par Météo-France avec la contribution des observateurs du réseau nivo-météorologiques. Partenariat : ANMSM (Maires de Stations de Montagne), DSF (Domaines Skiables de France), ADSP (Directeurs de Pistes et de la Sécurité des Stations de Sports d'Hiver) et autres acteurs de la montagne.

Bulletin neige & avalanches par téléphone au
0 892 68 10 20 Service 0,35 € / min + prix appel

RÉPUBLIQUE FRANÇAISE
Liberté Égalité Fraternité

METEO FRANCE
À VOS CÔTÉS, DANS UN CLIMAT QUI CHANGE

Bulletin d'estimation du risque d'avalanche

(valable en dehors des pistes balisées et ouvertes)

MASSIF : Cerdagne Canigou

Rédigé le samedi 7 février 2026 à 16h

Conditions nivo-météo des 7 derniers jours

	dim. 01/02				lun. 02/02				mar. 03/02				mer. 04/02				jeu. 05/02				ven. 06/02				sam. 07/02			
	03h	09h	15h	21h	03h	09h	15h	21h	03h	09h	15h	21h	03h	09h	15h	21h	03h	09h	15h	21h	03h	09h	15h	21h	03h	09h	15h	21h
Météo																												
Vent (km/h)	65	30	30	40	60	80	95	75	70	50	40	40	50	75	40	35	65	80	75	55	40	25	25	30	30	20	25	50
à 3000m																												
Vent (km/h)	40	15	15	15	35	60	80	55	45	25	25	20	25	45	25	25	45	60	55	40	25	15	15	20	20	15	15	40
à 2000m																												

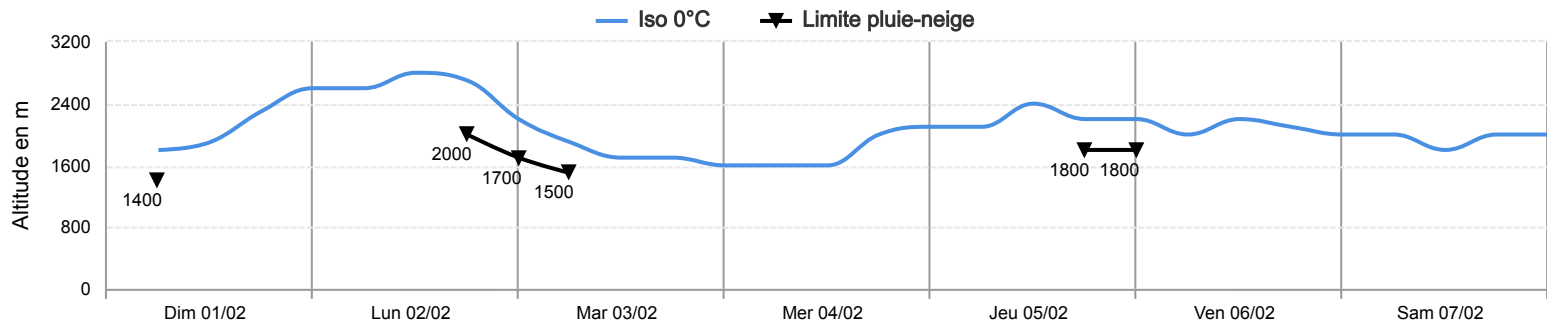

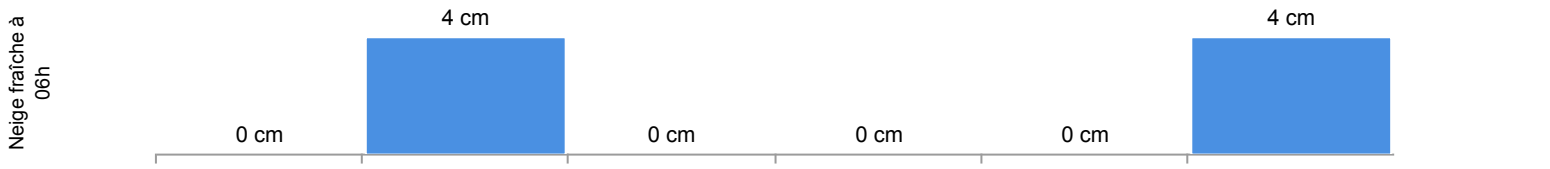

Risque d'avalanche	dim. 01/02	lun. 02/02	mar. 03/02	mer. 04/02	jeu. 05/02	ven. 06/02	sam. 07/02
	3	3	3	3	2	2	2

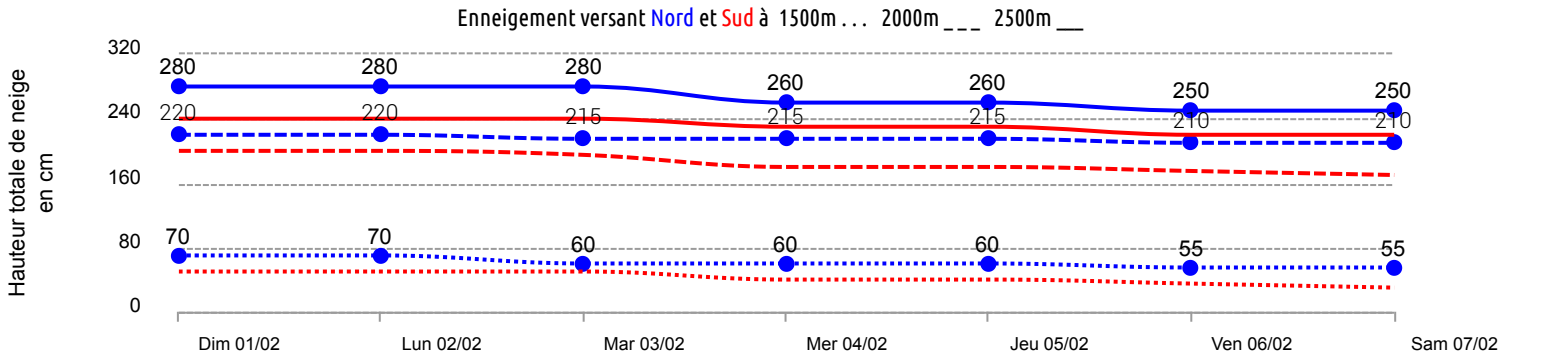

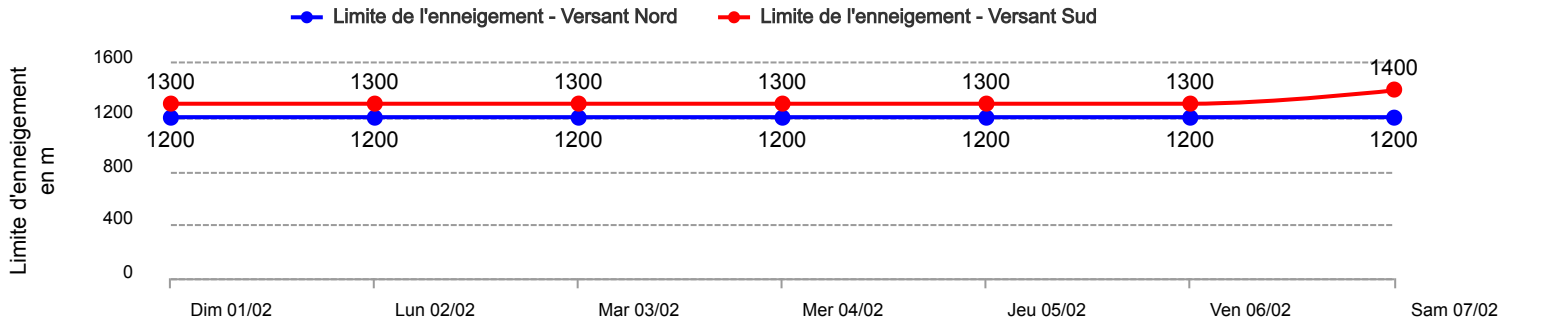

Pour consulter la vigilance en cours, veuillez vous rendre sur le site https://vigilance.meteofrance.fr/fr

Météo-France - 73 avenue de Paris, 94165 Saint-Mandé cedex - Contact : contact@meteo.fr

Rédigé par Météo-France avec la contribution des observateurs du réseau nivo-météorologiques. Partenariat : ANMSM (Maires de Stations de Montagne), DSF (Domaines Skiables de France), ADSP (Directeurs de Pistes et de la Sécurité des Stations de Sports d'Hiver) et autres acteurs de la montagne.

Bulletin neige & avalanches par téléphone au
0 892 68 10 20 Service 0,35 € / min + prix appel