Bulletin d'estimation du risque d'avalanche

(valable en dehors des pistes balisées et ouvertes)

MASSIF : Devoluy

Rédigé le samedi 7 février 2026 à 16h

Estimation des risques pour le : DIMANCHE 08 FÉVRIER

INSTABILITÉS ENCORE FACILES À DÉCLENCHER EN ALTITUDE

3

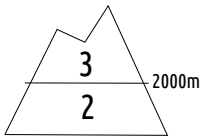

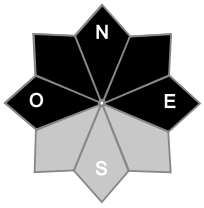

Au-dessus de 2000m indice de risque marqué, plus bas indice limité.

Départs spontanés : En neige récente humidifiée, plutôt ponctuels et de taille petite à moyenne.

Déclenchements provoqués : instabilités persistant en versants froids d'altitude, faciles à déclencher

Indices de risque : 5 très fort - 4 fort - 3 marqué - 2 limité - 1 faible -- En noir : les pentes les plus dangereuses

Stabilité du manteau neigeux

Situation avalancheuse typique : neige fraîche couche fragile persistante

Déclenchements provoqués : le manteau neigeux reste modérément stabilisé au-dessus de 2000 m. Ces instabilités se présentent souvent sous forme de plaques d'aspect parfois poudreux et difficiles à identifier. Déclenchements possibles par un seul skieur, même à distance, engendrant des avalanches moyennes (taille 2) avec des cassures pouvant dépasser la centaine de mètres de largeur. Des avalanches de grande taille (taille 3) emportant la quasi-totalité du manteau neigeux ne sont pas exclues dans les orientations ouest, nord et est, au-delà de 2300/2400 m. Déclenchement plus difficile et aléatoire, mais un premier départ de surface peut faciliter le déclenchement en contrebas de ces plaques volumineuses.
Le manteau neigeux est en effet constitué d'un empilement de couches fragiles : dans la neige récente, encore peu stabilisée, mais aussi à la base du manteau neigeux, détectable avec un test du bâton quand l'épaisseur de neige n'est pas trop importante.
Sous 2000 m, ainsi qu'en adrets raides d'altitude, l'instabilité est plus limitée. La neige récente a pris une bonne cohésion, avec la relative douceur humide ou au soleil, et les couches fragiles persistantes sont moins généralisées.

Départs spontanés : quelques départs de neige récente humidifiée dans les pentes raides au soleil près des rochers. Avalanches petites à moyennes (taille 1 à 2), en poire.

Qualité de la neige

L'enneigement est excédentaire pour un début février.
Données observées : 207 cm à la Nivôse de Écrins vers 3000 m, 198 cm au Pré de Mme Carle à 1900 m, 126 cm au hameau de Dormillouse à 1730 m.

Limite d'enneigement skiable : vers 1200/1300 m sur la plupart des itinéraires.

État de la neige de surface : 20/30 cm de neige récente en altitude, restée poudreuse et légère en versants froids, et parfois densifiée ou cartonnée par le vent près des crêtes. En versants ensoleillés, neige récente plus tassée, avec un début de transformation sous 2200/2400 m environ : croûte superficielle le matin, s'humidifiant au soleil en journée.

Aperçu météo pour le dimanche 08 février

	nuit	matin	après-midi	soir

Courte fenêtre ensoleillée le matin, devenant couvert l'après-midi, quelques flocons le soir

Pluie-Neige				1 200 m
Iso 0 °C	1 700 m	1 700 m	1 600 m	1 500 m
Vent 2000 m	↓ 10 km/h	↑ 20 km/h	↙ 20 km/h	↖ 10 km/h
Vent 3000 m	↗ 10 km/h	↖ 25 km/h	↖ 25 km/h	↑ 10 km/h

Épaisseur de neige hors-piste

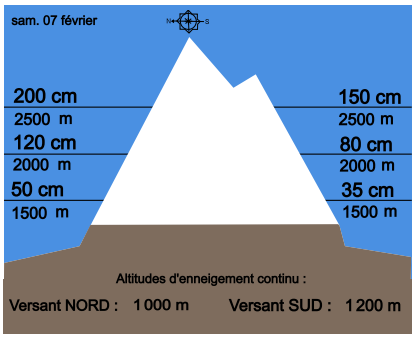

Précipitations à 1800 m

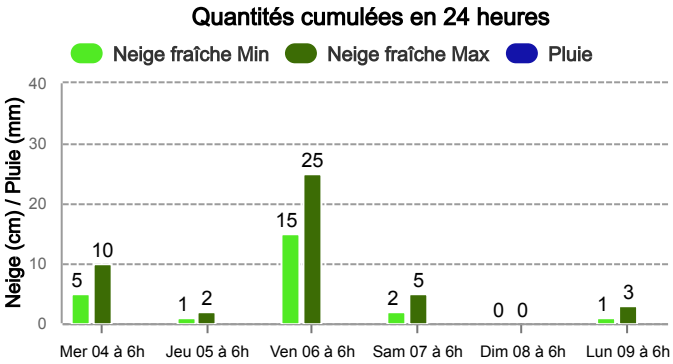

Tendance du lundi 09 février

3 **Indice de risque marqué**

Poursuite de la lente stabilisation du manteau neigeux. Les couches fragiles persistantes deviennent difficilement sollicitables. Risque encore probablement marqué, mais évolution vers un risque limité envisageable.

Pour consulter la vigilance en cours, veuillez vous rendre sur le site https://vigilance.meteofrance.fr/fr

Météo-France - 73 avenue de Paris, 94165 Saint-Mandé cedex - Contact : contact@meteo.fr

Rédigé par Météo-France avec la contribution des observateurs du réseau nivo-météorologiques. Partenariat : ANMSM (Maires de Stations de Montagne), DSF (Domaines Skiables de France), ADSP (Directeurs de Pistes et de la Sécurité des Stations de Sports d'Hiver) et autres acteurs de la montagne.

Bulletin neige & avalanches par téléphone au 0 892 68 10 20 Service 0,35 € / min + prix appel

RÉPUBLIQUE FRANÇAISE
Liberté Égalité Fraternité

METEO FRANCE
À VOS CÔTÉS, DANS UN CLIMAT QUI CHANGE

Bulletin d'estimation du risque d'avalanche

(valable en dehors des pistes balisées et ouvertes)

MASSIF : Devoluy

Rédigé le samedi 7 février 2026 à 16h

Conditions nivo-météo des 7 derniers jours

	dim. 01/02				lun. 02/02				mar. 03/02				mer. 04/02				jeu. 05/02				ven. 06/02				sam. 07/02			
	03h	09h	15h	21h	03h	09h	15h	21h	03h	09h	15h	21h	03h	09h	15h	21h	03h	09h	15h	21h	03h	09h	15h	21h	03h	09h	15h	21h
Météo																												
Vent (km/h)	20	20	40	30	35	50	70	100	120	60	50	40	40	40	30	15	30	15	60	40	40	45	35	20	15	10	10	5
à 3000m	↓	↘	↘	↘	↘	↗	↑	↑	↑	↗	↗	↑	↑	↑	↑	↗	↘	→	↑	→	↘	↘	↘	↘	↘	↑	↑	↓
Vent (km/h)	20	20	15	10	10	25	45	80	70	45	35	35	35	30	20	5	10	20	60	10	25	25	25	15	10	10	15	10
à 2000m	↓	↻	↓	↙	↗	↑	↖	↑	↖	↑	↑	↖	↖	↖	↖	→	↘	↑	↑	↑	↘	↘	↘	↓	↓	↑	↑	↙

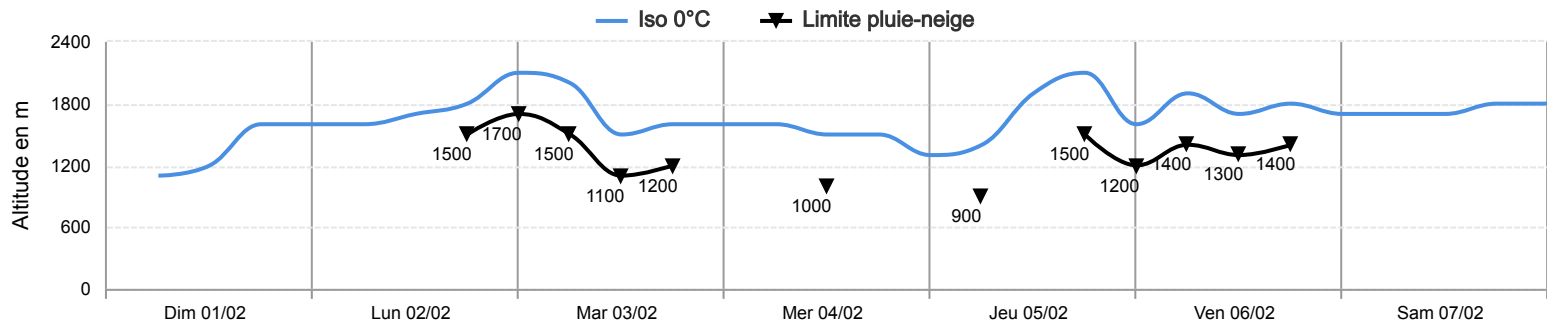

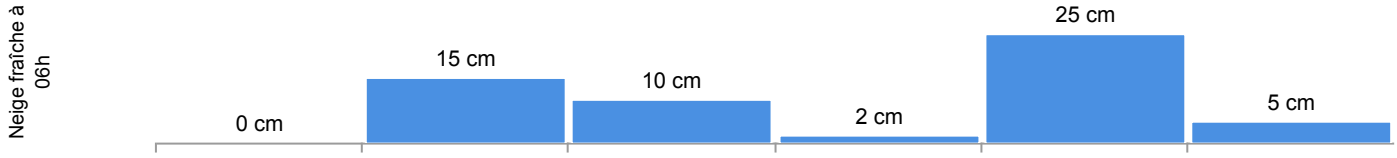

Risque d'avalanche	dim. 01/02	lun. 02/02	mar. 03/02	mer. 04/02	jeu. 05/02	ven. 06/02	sam. 07/02
	3	3	4	3	3	4	3

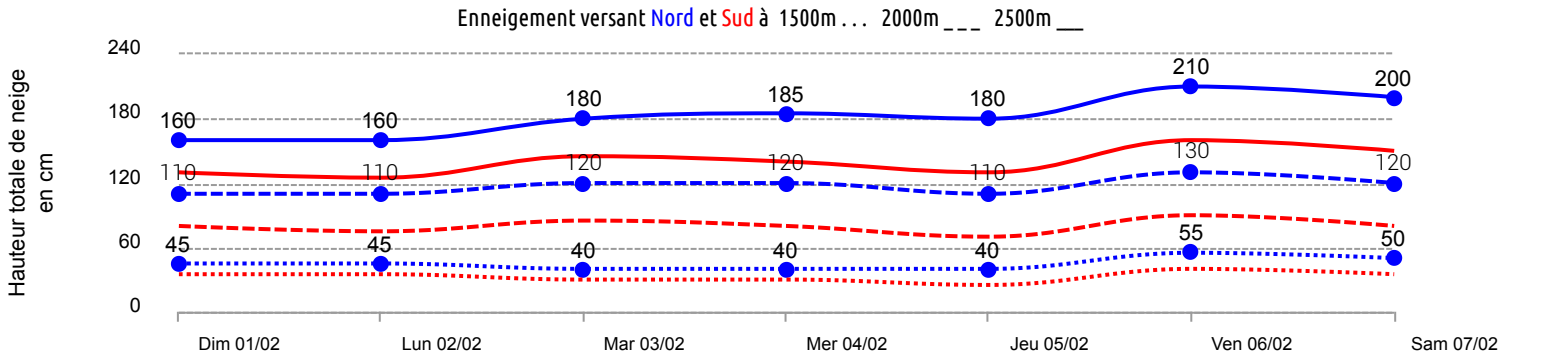

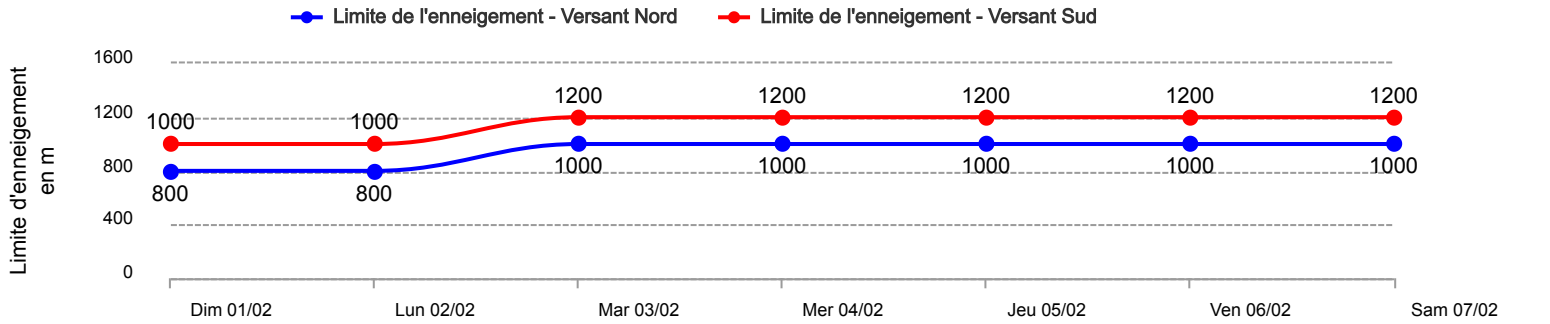

Pour consulter la vigilance en cours, veuillez vous rendre sur le site https://vigilance.meteofrance.fr/fr

Météo-France - 73 avenue de Paris, 94165 Saint-Mandé cedex - Contact : contact@meteo.fr

Rédigé par Météo-France avec la contribution des observateurs du réseau nivo-météorologiques. Partenariat : ANMSM (Maires de Stations de Montagne), DSF (Domaines Skiables de France), ADSP (Directeurs de Pistes et de la Sécurité des Stations de Sports d'Hiver) et autres acteurs de la montagne.

Bulletin neige & avalanches par téléphone au

0 892 68 10 20 Service 0,35 € / min + prix appel