RÉPUBLIQUE FRANÇAISE
Liberté Égalité Fraternité

METEO FRANCE
À VOS CÔTÉS, DANS UN CLIMAT QUI CHANGE

Bulletin d'estimation du risque d'avalanche
(valable en dehors des pistes balisées et ouvertes)
MASSIF : Embrunais Parpaillon

Rédigé le samedi 7 février 2026 à 16h

Estimation des risques pour le : DIMANCHE 08 FÉVRIER

INSTABILITÉS ENCORE FACILES À DÉCLENCHER EN ALTITUDE, PARFOIS TRÈS VOLUMINEUSES

3

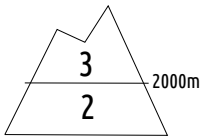

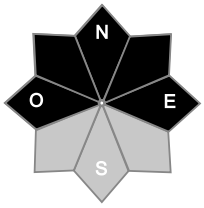

Au-dessus de 2000m indice de risque marqué, plus bas indice limité.

Départs spontanés : En neige récente humidifiée, plutôt ponctuels et de taille petite à moyenne.

Déclenchements provoqués : instabilités persistant en versants froids d'altitude, faciles à déclencher

Indices de risque : 5 très fort - 4 fort - 3 marqué - 2 limité - 1 faible -- En noir : les pentes les plus dangereuses

Stabilité du manteau neigeux

Situation avalancheuse typique : couche fragile persistante neige fraîche

Déclenchements provoqués : le manteau neigeux reste faiblement à modérément stabilisé au-dessus de 2000 m. Ces instabilités se présentent souvent sous forme de plaques d'aspect poudreux, difficiles à identifier. Déclenchements faciles, même à distance, engendrant des avalanches moyennes (taille 2) avec des cassures pouvant dépasser la centaine de mètres de largeur. Des avalanches de grande taille (taille 3) emportant la quasi-totalité du manteau neigeux sont possibles dans les orientations ouest, nord et est, notamment au-delà de 2300/2400 m. Un premier départ de surface peut faciliter le déclenchement en contrebas de ces plaques volumineuses.
Le manteau neigeux est en effet constitué d'un empilement de couches fragiles : dans la neige récente, encore peu stabilisée, mais aussi à la base du manteau neigeux, détectable avec un test du bâton quand l'épaisseur de neige n'est pas trop importante.
Sous 2000 m, ainsi qu'en adrets raides d'altitude, l'instabilité est plus limitée. La neige récente a pris une bonne cohésion, avec la relative douceur humide ou au soleil, et les couches fragiles persistantes sont moins généralisées.

Départs spontanés : quelques départs de neige récente humidifiée dans les pentes raides au soleil près des rochers. Avalanches petites à moyennes (taille 1 à 2), en poire.

Qualité de la neige

L'enneigement est légèrement excédentaire pour un début février.
Données observées : 85 cm à la Nivôse du Parpaillon à 2550 m, secteur soufflé par le vent.

Limite d'enneigement skiable : dès 1200/1400 m sur la plupart des itinéraires, peu de sous-couche en adrets à cette altitude.

État de la neige de surface : 20/30 cm de neige récente, restée poudreuse et légère en versants froids, et parfois densifiée ou cartonnée par le vent près des crêtes. En versants ensoleillés, neige récente plus tassée, avec un début de transformation sous 2000/2200 m environ : croûte superficielle le matin, s'humidifiant au soleil en journée. Faible chute de neige en fin de journée à proximité de l'Ubaye.

Aperçu météo pour le dimanche 08 février

	nuit	matin	après-midi	soir
	Courte fenêtre ensoleillée le matin, devenant couvert l'après-midi, quelques flocons			
Pluie-Neige			1 400 m	1 300 m
Iso 0 °C	1 700 m	1 900 m	1 800 m	1 700 m
Vent 2000 m	↓ 10 km/h	↖ 10 km/h	← 15 km/h	↖ 10 km/h
Vent 3000 m	↑ 15 km/h	↖ 15 km/h	← 20 km/h	← 15 km/h

Épaisseur de neige hors-piste

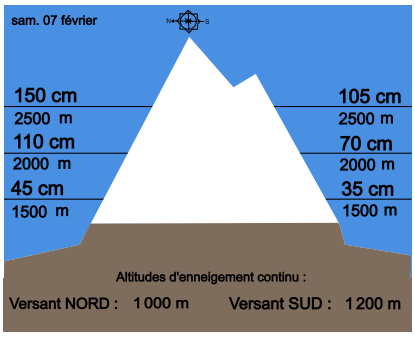

Précipitations à 1800 m

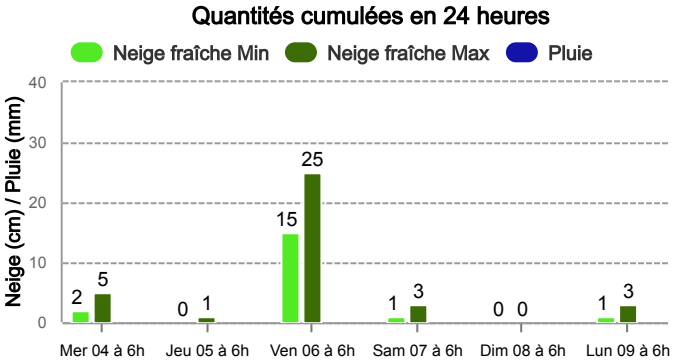

Tendance du lundi 09 février

3 **Indice de risque marqué**

Poursuite de la lente stabilisation du manteau neigeux, que les faibles chutes de neige dimanche soir n'influencent guère. Les couches fragiles persistantes restent sollicitables. Risque marqué en altitude.

Pour consulter la vigilance en cours, veuillez vous rendre sur le site https://vigilance.meteofrance.fr/fr

Météo-France - 73 avenue de Paris, 94165 Saint-Mandé cedex - Contact : contact@meteo.fr

Rédigé par Météo-France avec la contribution des observateurs du réseau nivo-météorologiques. Partenariat : ANMSM (Maires de Stations de Montagne), DSF (Domaines Skiables de France), ADSP (Directeurs de Pistes et de la Sécurité des Stations de Sports d'Hiver) et autres acteurs de la montagne.

Bulletin neige & avalanches par téléphone au
0 892 68 10 20 Service 0,35 € / min + prix appel

RÉPUBLIQUE FRANÇAISE
Liberté Égalité Fraternité

METEO FRANCE
À VOS CÔTÉS, DANS UN CLIMAT QUI CHANGE

Bulletin d'estimation du risque d'avalanche
(valable en dehors des pistes balisées et ouvertes)
MASSIF : Embrunais Parpaillon

Rédigé le samedi 7 février 2026 à 16h

Conditions nivo-météo des 7 derniers jours

	dim. 01/02				lun. 02/02				mar. 03/02				mer. 04/02				jeu. 05/02				ven. 06/02				sam. 07/02			
	03h	09h	15h	21h	03h	09h	15h	21h	03h	09h	15h	21h	03h	09h	15h	21h	03h	09h	15h	21h	03h	09h	15h	21h	03h	09h	15h	21h
Météo																												
Vent (km/h)	15	15	25	35	30	30	45	80	80	60	40	40	40	40	20	15	25	20	45	15	40	35	35	20	20	10	5	5
à 3000m																												
Vent (km/h)	10	10	10	10	10	10	15	40	40	30	20	15	15	20	15	10	10	10	20	15	15	15	20	10	10	5	10	10
à 2000m																												

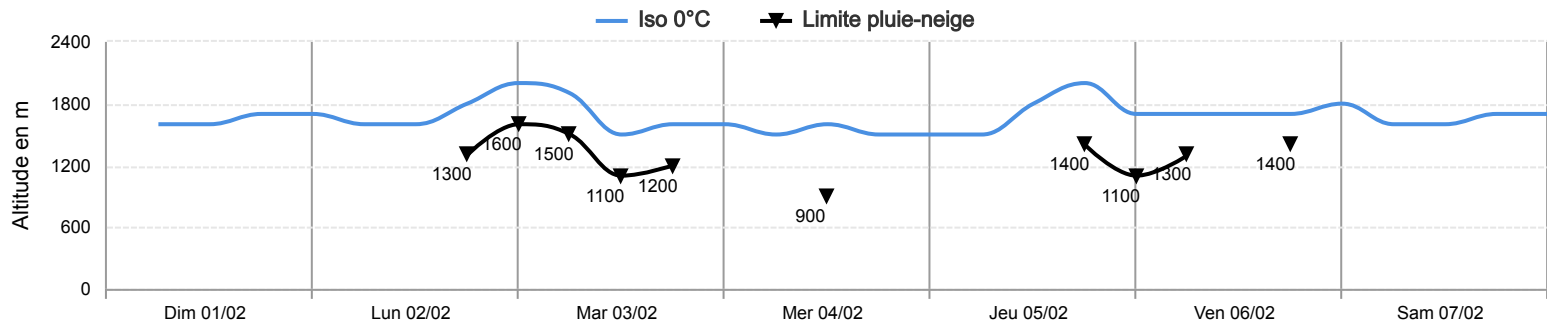

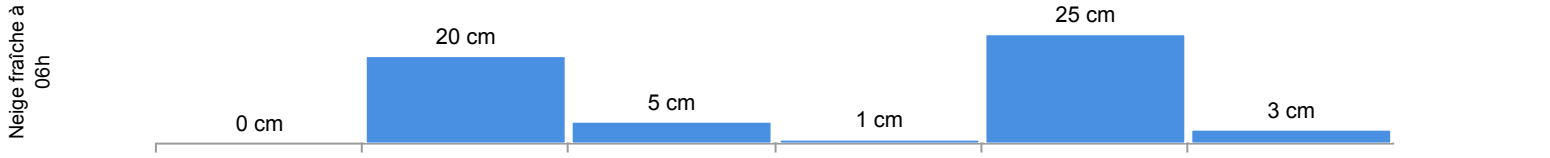

Risque d'avalanche	dim. 01/02	lun. 02/02	mar. 03/02	mer. 04/02	jeu. 05/02	ven. 06/02	sam. 07/02
	3	3	4	4	3	4	4

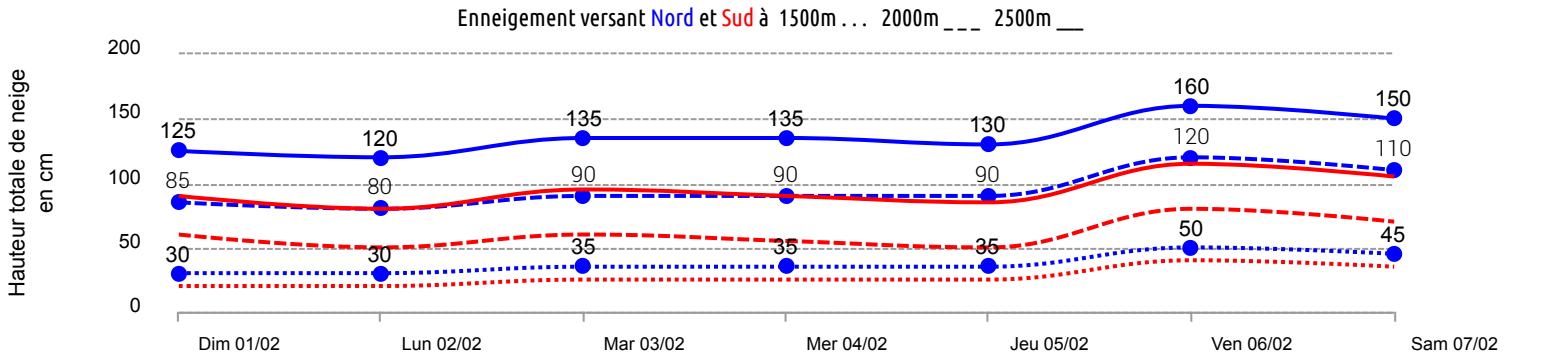

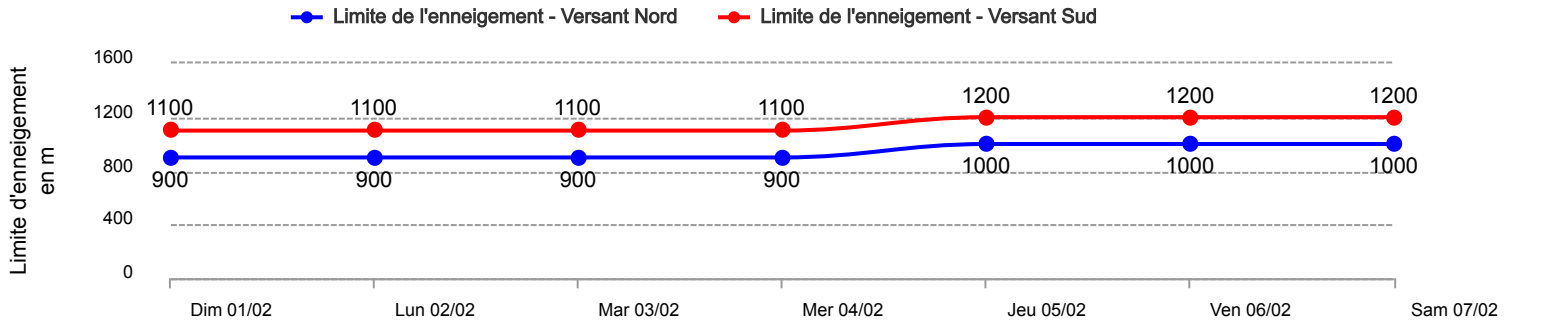

Pour consulter la vigilance en cours, veuillez vous rendre sur le site https://vigilance.meteofrance.fr/fr

Météo-France - 73 avenue de Paris, 94165 Saint-Mandé cedex - Contact : contact@meteo.fr

Rédigé par Météo-France avec la contribution des observateurs du réseau nivo-météorologiques. Partenariat : ANMSM (Maires de Stations de Montagne), DSF (Domaines Skiables de France), ADSP (Directeurs de Pistes et de la Sécurité des Stations de Sports d'Hiver) et autres acteurs de la montagne.

Bulletin neige & avalanches par téléphone au
0 892 68 10 20 Service 0,35 € / min + prix appel