Bulletin d'estimation du risque d'avalanche

(valable en dehors des pistes balisées et ouvertes)

MASSIF : Grandes-Rousses

Rédigé le samedi 7 février 2026 à 16h

Estimation des risques pour le : DIMANCHE 08 FÉVRIER

ENCORE QUELQUES PLAQUES INSTABLES EN FACES NORD D'ALTITUDE, PARFOIS DIFFICILES A DECELER ; EPAISSES CASSURES NON EXCLUES...

3

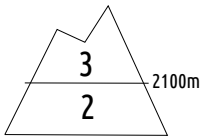

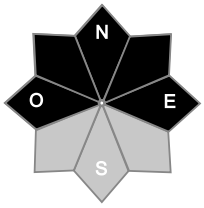

Altitude + crêtes

Indices de risque : 5 très fort - 4 fort - 3 marqué - 2 limité - 1 faible -- En noir : les pentes les plus dangereuses

Au-dessus de 2100m indice de risque marqué, plus bas indice limité.

Départs spontanés : Peu probables... Si éclaircies, petites coulées ponctuelles au soleil, près des rochers...

Déclenchements provoqués : Quelques plaques de surface en larges faces Nord à Est Déclenchement plus épais/à distance non exclu au dessus de 2300m environ ?

Stabilité du manteau neigeux

Situation avalancheuse typique : neige ventée couche fragile persistante

En faces ombragées d'altitude, des sous couches fragiles sont bien enfouies, encore un risque de déclenchement à distance d'épaisse et large plaque... Sous 1900/2100m a priori, neige en partie tassée ou instabilités plus superficielles.

Déclenchements provoqués : Risque de plaque sans doute encore localement marqué en faces ombragées d'altitude, notamment plus haut que 2100/2300m. A l'abord des crêtes risque de rupture de plaque friable (en poudreuse dense), de 20/40 cm environ.
Dans un cas défavorable la rupture d'une plaque de surface (peu large) pourrait déstabiliser une couche fragile bien enfouie et dégénérer en épaisse et large avalanche ? Peu d'indices de terrain si ce ne sont de rares récentes cassures spontanées. Des sous couches sans aucune cohésion sont plus régulièrement observées vers Emparis...
Plus bas que 2100m moins de neige mobilisable en général et des sous-couches moins "réactives".
Enfin à modeste altitude (sous 1700/1900m) l'humidification de surface a crouté la neige, pas de risque de plaque a priori mais un ski assez délicat en terrain non tracé...

Départs spontanés : Peu d'activité a priori ou si éclaircies une rare coulée/petite avalanche ponctuelle de neige humide près des rochers, aux altitudes modestes... En prairies/clairières raides, très rare départ de fond/glissement (de taille moyenne), plutôt l'après-midi?

Qualité de la neige

Qualification de l'enneigement : L'enneigement est correct à très bon pour la saison en altitude, dans les combes et médiocre sous la moyenne montagne...
Limites skiables : vers 1100/1500 m.

Qualité de la neige Dimanche : En dessous de 1800/2200m suivant l'exposition au soleil, neige croutée en surface, s'humidifiant un peu lors d'éventuelles éclaircies...
Dans les faces ombragées dès 1800/2000m, neige poudreuse peu ventée.
Certaines pentes ont été striées par de récentes petites avalanches humides...

Aperçu météo pour le dimanche 08 février

	nuit	matin	après-midi	soir

Temps calme et sec, avec des voiles nuageux élevés un peu plus denses en cours d'après-midi...

Pluie-Neige				
Iso 0 °C	1 700 m	1 900 m	1 900 m	1 700 m
Vent 2000 m	↑ 10 km/h	↖ 15 km/h	↖ 15 km/h	↖ 20 km/h
Vent 3000 m	↖ 15 km/h	↖ 20 km/h	↖ 25 km/h	↖ 25 km/h

Épaisseur de neige hors-piste

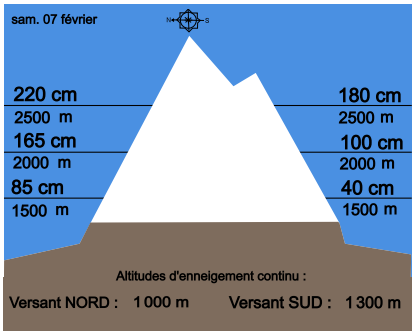

Précipitations à 1800 m

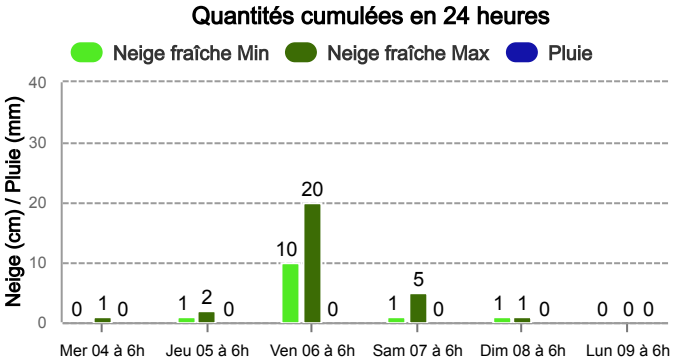

Tendance du lundi 09 février

3 **Indice de risque marqué**

Lundi, Risque d'avalanche en légère hausse.
Un peu de vent de Sud vers les hautes crêtes, possibles formations de nouvelles petites plaques (bien instables) en faces Nord...

Pour consulter la vigilance en cours, veuillez vous rendre sur le site https://vigilance.meteofrance.fr/fr

Météo-France - 73 avenue de Paris, 94165 Saint-Mandé cedex - Contact : contact@meteo.fr

Rédigé par Météo-France avec la contribution des observateurs du réseau nivo-météorologiques. Partenariat : ANMSM (Maires de Stations de Montagne), DSF (Domaines Skiables de France), ADSP (Directeurs de Pistes et de la Sécurité des Stations de Sports d'Hiver) et autres acteurs de la montagne.

Bulletin neige & avalanches par téléphone au
0 892 68 10 20 Service 0,35 € / min + prix appel

RÉPUBLIQUE FRANÇAISE
Liberté Égalité Fraternité

METEO FRANCE
À VOS CÔTÉS, DANS UN CLIMAT QUI CHANGE

Bulletin d'estimation du risque d'avalanche

(valable en dehors des pistes balisées et ouvertes)

MASSIF : Grandes-Rousses

Rédigé le samedi 7 février 2026 à 16h

Conditions nivo-météo des 7 derniers jours

	dim. 01/02				lun. 02/02				mar. 03/02				mer. 04/02				jeu. 05/02				ven. 06/02				sam. 07/02			
	03h	09h	15h	21h	03h	09h	15h	21h	03h	09h	15h	21h	03h	09h	15h	21h	03h	09h	15h	21h	03h	09h	15h	21h	03h	09h	15h	21h
Météo																												
Vent (km/h)	20	20	20	20	25	40	65	105	100	95	80	65	35	35	35	25	25	45	45	45	45	30	25	20	20	10	10	10
à 3000m																												
Vent (km/h)	10	10	10	10	15	25	50	90	80	75	60	35	25	30	20	10	15	30	30	30	20	20	20	10	5	10	10	5
à 2000m																												

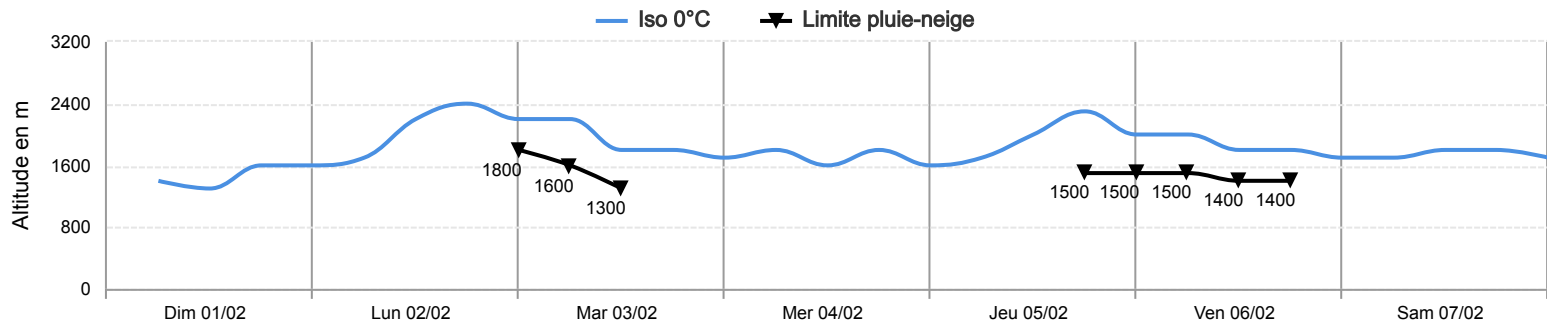

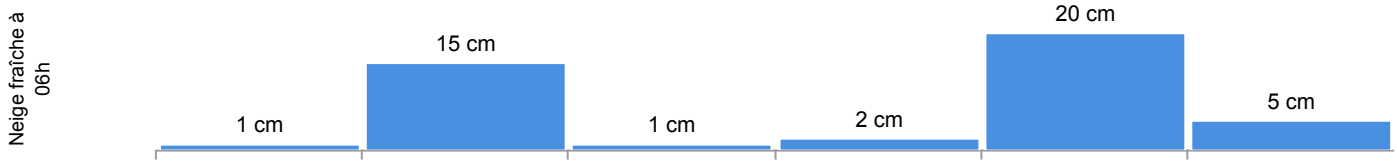

Risque d'avalanche	dim. 01/02	lun. 02/02	mar. 03/02	mer. 04/02	jeu. 05/02	ven. 06/02	sam. 07/02
	3	3	4	4	3	3	3

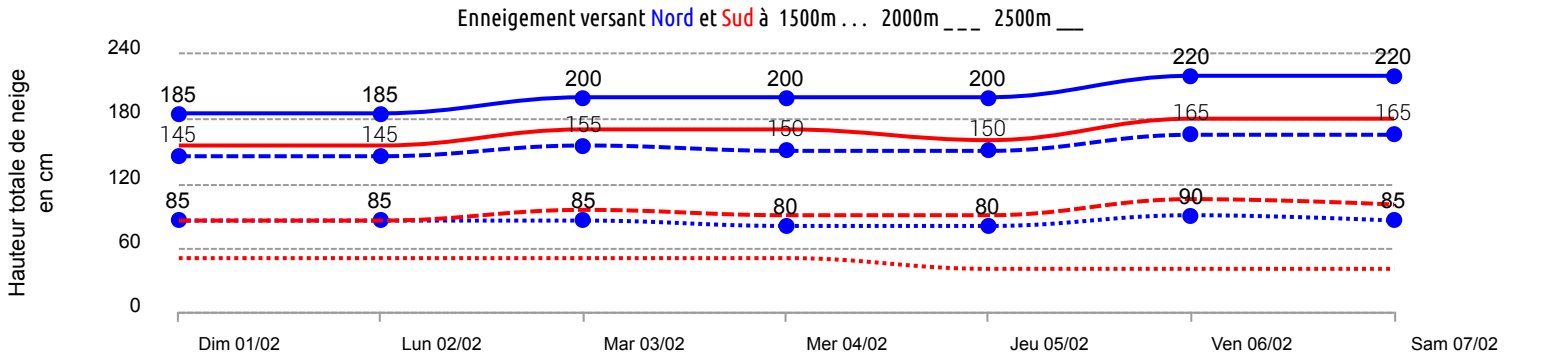

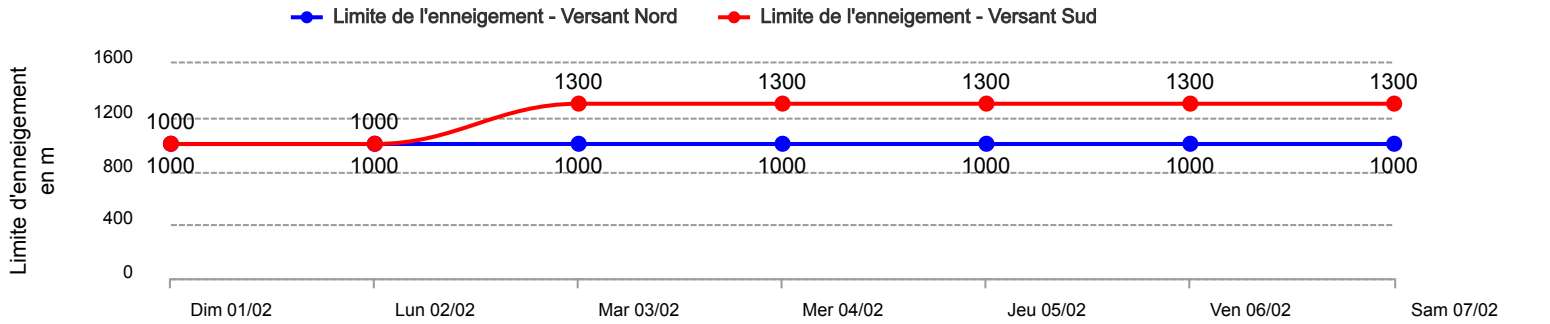

Pour consulter la vigilance en cours, veuillez vous rendre sur le site https://vigilance.meteofrance.fr/fr

Météo-France - 73 avenue de Paris, 94165 Saint-Mandé cedex - Contact : contact@meteo.fr

Rédigé par Météo-France avec la contribution des observateurs du réseau nivo-météorologiques. Partenariat : ANMSM (Maires de Stations de Montagne), DSF (Domaines Skiables de France), ADSP (Directeurs de Pistes et de la Sécurité des Stations de Sports d'Hiver) et autres acteurs de la montagne.

Bulletin neige & avalanches par téléphone au
0 892 68 10 20 Service 0,35 € / min + prix appel