Bulletin d'estimation du risque d'avalanche
(valable en dehors des pistes balisées et ouvertes)

MASSIF : Haute-Tarentaise

Rédigé le samedi 7 Février 2026 à 16h

Estimation des risques pour le : DIMANCHE 08 FÉVRIER

QUELQUES PLAQUES D'ASPECT POUDREUX. RARES GRANDES AVALANCHES POSSIBLES.

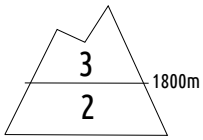

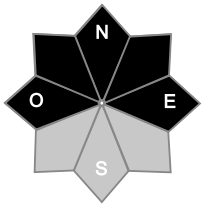

Au-dessus de 1800m indice de risque marqué, plus bas indice limité.

Départs spontanés : petites plaques sous le Foehn.

Déclenchements provoqués : quelques plaques poudreuses. Rares grandes avalanches possibles.

Indices de risque : 5 très fort - 4 fort - 3 marqué - 2 limité - 1 faible -- En noir : les pentes les plus dangereuses

Stabilité du manteau neigeux

Situation avalancheuse typique : neige ventée couche fragile persistante

Déclenchements provoqués : quelques **plaques friables d'aspect poudreux** sont en place près des crêtes. De nouvelles se forment là où le vent de Sud transporte la neige récente (secteur frontalier). Elles restent réactives en journée dans les versants Est, Nord et Ouest. Elles occasionnent des cassures de ~20 cm et des avalanches de taille 1 à 2 (petite à moyenne). **Observables :** accumulation de neige fraiche supérieure à la moyenne environnante, transport de neige par le vent.
Facteur aggravant, au dessus de 1800m et en versants froids (Est/Nord/Ouest) mais **aussi en Sud à haute altitude, des couches fragiles persistantes enfouies** dans le manteau pourront réagir au passage d'un skieur ou en cascade grâce aux plaques friables. Elles **engendrent de plus grandes et larges avalanches : taille 3 possible.**
Observables : woumfs en ce qui concerne les couches fragiles persistantes enfouies.

Départs spontanés : là où le vent transporte la neige (en particulier à l'approche de la crête frontière), des plaques cèdent dans les pentes raides (taille 1). En l'absence de vent, l'activité naturelle est peu probable.

Qualité de la neige

Enneigement : un peu en dessous des normales de saison mais les chutes à venir (dans la semaine) devraient améliorer nettement l'enneigement

Limite skiable : dans les secteurs soumis au foehn les limites skiables sont remontées au delà de 1600m en Sud. A l'abri du foehn on peut encore chausser localement en Nord vers 1000/1100m .

Qualité de la neige : en Est, Nord et Ouest, la neige est croutée jusqu'à 1500-1700 m. Plus haut, elle devient poudreuse (~20 cm), bonne à skier, jusqu'à l'approche des crêtes où elle est légèrement travaillée par le vent.
En Sud Est à Sud Ouest, elle est croutée le matin et ramollie doucement au fil des heures. Il faut monter sur les plus hautes pentes dans ces orientations pour trouver de la neige froide.

Aperçu météo pour le dimanche 08 février

	nuit	matin	après-midi	soir
	Ciel variable. Eclaircies possibles.			
Pluie-Neige				
Iso 0 °C	1 700 m	2 000 m	2 100 m	1 700 m
Vent 2500 m	← 10 km/h	↙ 25 km/h	↙ 25 km/h	↙ 20 km/h
Vent 3500 m	↗ 20 km/h	↖ 30 km/h	↖ 30 km/h	↖ 25 km/h

Épaisseur de neige hors-piste

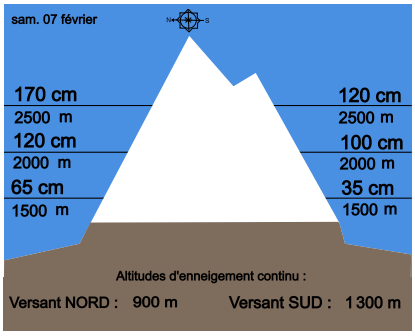

Précipitations à 1800 m

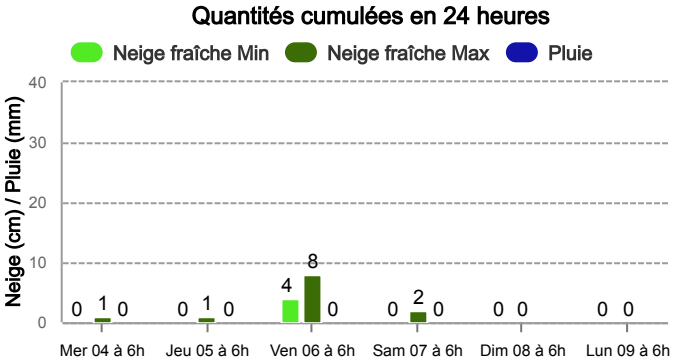

Tendance du lundi 09 février

Indice de risque marqué

Manteau neigeux encore piégeux avec des plaques de neige récentes "en surface" et une couche fragile persistante enfouie qui engendre occasionnellement des départs plus gros.

Pour consulter la vigilance en cours, veuillez vous rendre sur le site https://vigilance.meteofrance.fr/fr

Météo-France - 73 avenue de Paris, 94165 Saint-Mandé cedex - Contact : contact@meteo.fr

Rédigé par Météo-France avec la contribution des observateurs du réseau nivo-météorologiques. Partenariat : ANMSM (Maires de Stations de Montagne), DSF (Domaines Skiables de France), ADSP (Directeurs de Pistes et de la Sécurité des Stations de Sports d'Hiver) et autres acteurs de la montagne.

Bulletin neige & avalanches par téléphone au 0 892 68 10 20 Service 0,35 € / min + prix appel

RÉPUBLIQUE FRANÇAISE
Liberté Égalité Fraternité

METEO FRANCE
À VOS CÔTÉS, DANS UN CLIMAT QUI CHANGE

Bulletin d'estimation du risque d'avalanche

(valable en dehors des pistes balisées et ouvertes)

MASSIF : Haute-Tarentaise

Rédigé le samedi 7 février 2026 à 16h

Conditions nivo-météo des 7 derniers jours

	dim. 01/02				lun. 02/02				mar. 03/02				mer. 04/02				jeu. 05/02				ven. 06/02				sam. 07/02			
	03h	09h	15h	21h	03h	09h	15h	21h	03h	09h	15h	21h	03h	09h	15h	21h	03h	09h	15h	21h	03h	09h	15h	21h	03h	09h	15h	21h
Météo																												
Vent (km/h)	20	20	30	30	40	45	60	85	90	75	50	50	55	30	30	35	35	35	40	40	40	45	45	20	15	15	15	15
à 3500m																												
Vent (km/h)	10	10	10	10	10	25	45	70	75	55	35	25	35	30	20	10	15	20	25	30	30	35	35	15	5	5	5	5
à 2500m																												

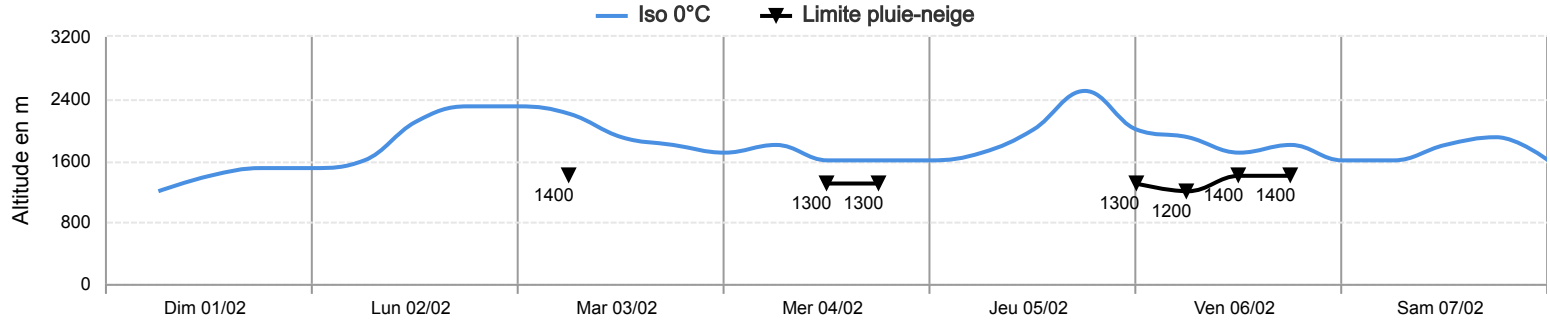

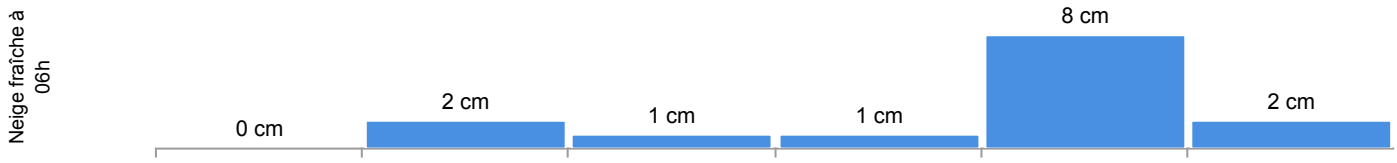

Risque d'avalanche	dim. 01/02	lun. 02/02	mar. 03/02	mer. 04/02	jeu. 05/02	ven. 06/02	sam. 07/02
	3	3	3	3	3	3	3

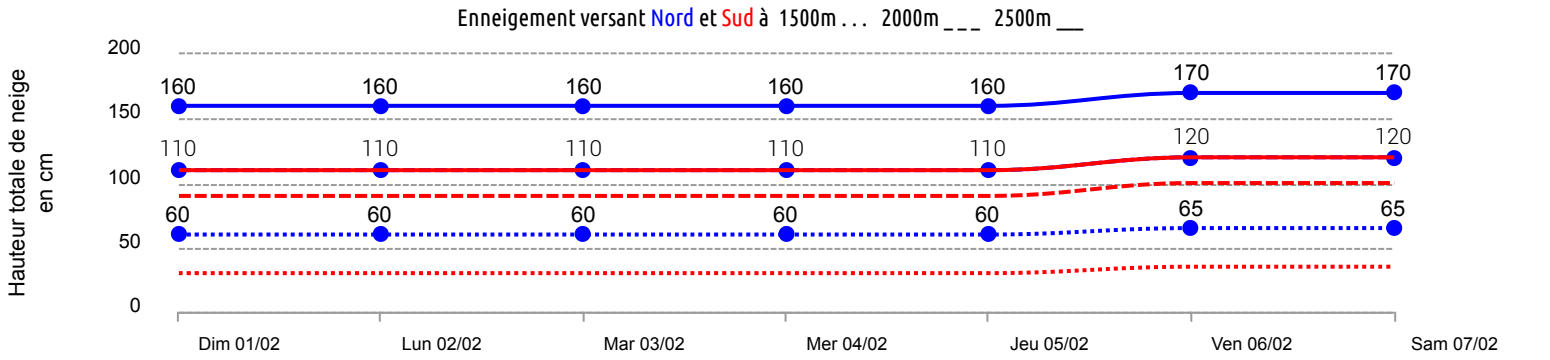

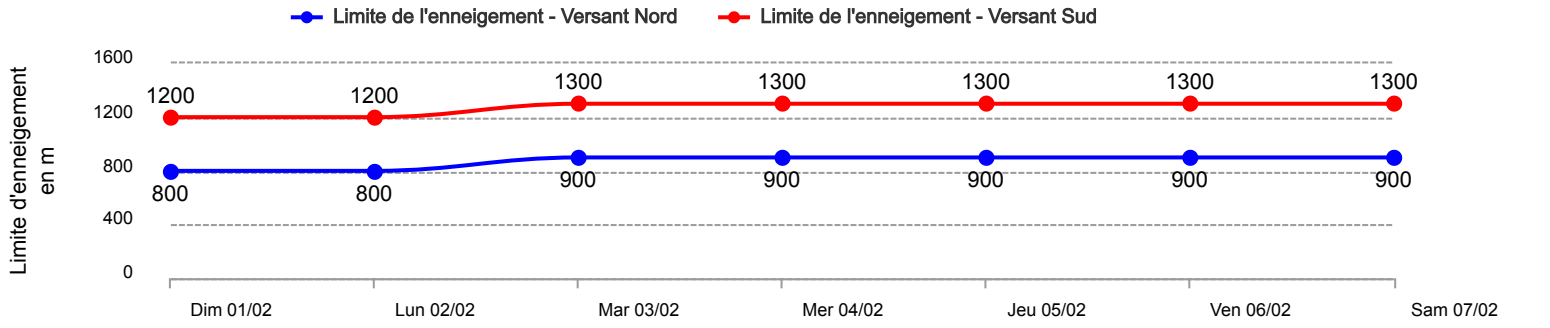

Pour consulter la vigilance en cours, veuillez vous rendre sur le site https://vigilance.meteofrance.fr/fr

Météo-France - 73 avenue de Paris, 94165 Saint-Mandé cedex - Contact : contact@meteo.fr

Rédigé par Météo-France avec la contribution des observateurs du réseau nivo-météorologiques. Partenariat : ANMSM (Maires de Stations de Montagne), DSF (Domaines Skiables de France), ADSP (Directeurs de Pistes et de la Sécurité des Stations de Sports d'Hiver) et autres acteurs de la montagne.

Bulletin neige & avalanches par téléphone au

0 892 68 10 20 Service 0,35 € / min + prix appel