Bulletin d'estimation du risque d'avalanche
(valable en dehors des pistes balisées et ouvertes)

MASSIF : Mercantour

Rédigé le samedi 7 février 2026 à 16h

Estimation des risques pour le : DIMANCHE 08 FÉVRIER

INSTABILITÉS MARQUÉES DANS LA NEIGE RÉCENTE, LOCALEMENT VOLUMINEUSES.

3

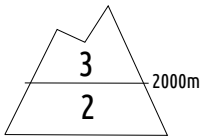

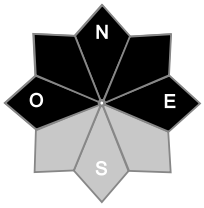

Au-dessus de 2000m indice de risque marqué, plus bas indice limité.

Départs spontanés : peu probables ou superficiel en neige humide de petite taille.

Déclenchements provoqués : encore des plaques faciles à déclencher, même à distance.

Indices de risque : 5 très fort - 4 fort - 3 marqué - 2 limité - 1 faible -- En noir : les pentes les plus dangereuses

Stabilité du manteau neigeux

Situation avalancheuse typique : couche fragile persistante neige fraîche

Déclenchements provoqués : le manteau neigeux est encore instable dans de nombreuses pentes au-dessus de 2000 m environ. Nombreuses instabilités en place facilement déclenchables par un skieur ou un randonneur. Elles peuvent encore être difficiles à déclencher car d'aspect poudreux, sinon durcies par le vent dans les secteurs exposés. Elles engendrent des avalanches de plaques de taille petite à moyenne (taille 1 à 2), emportant la totalité de la neige récente. Dans les orientations ouest, nord, et est au-dessus de 2000/2200 m, la présence d'une couche fragile persistante plus profondément enfouie rend possible des avalanches de taille moyenne à grande (taille 2 à 3), si une première avalanche de surface vient solliciter l'une de ces couches fragiles. Cassures sur des largeurs importantes possibles.
Sous 2000 m, le risque de déclenchement est plus limité.
Les faibles chutes de neige à proximité de la frontière italienne en fin de journée ne modifient guère la stabilité du manteau neigeux.

Départs spontanés : peu probables. Un éventuel départ ponctuel de petite ampleur (taille 1) en neige humide n'est pas exclue en pentes raides.

Qualité de la neige

Enneigement bon voire excédentaire jusqu'à basse altitude pour un début février.
Données observées : 146 cm à la nivôse de Millefonts à 2400 m, 137 cm à Isola 2000 à 1912m.

Enneigement skiable dès 1200/1300 m en terrain favorable, mais peu de sous-couche sous 1600 m en général.

État de la neige en surface : neige croutée en adrets jusque vers 1900/2200 m, plus bas en ubacs, s'humidifiant en journée. Sinon neige fraiche/récente en quantité, poudreuse, localement densifiée par le vent. Corniches et congères parfois volumineuses en place.

Aperçu météo pour le dimanche 08 février

	nuit	matin	après-midi	soir

Ciel se couvrant en matinée. Faibles chutes de neige l'après-midi et nuit suivante, plus importantes près de la frontière italienne.

Pluie-Neige			1 400 m	1 300 m
Iso 0 °C	1 800 m	1 900 m	1 900 m	1 600 m
Vent 2000 m	↓ 10 km/h	← 10 km/h	↙ 20 km/h	↙ 20 km/h
Vent 3000 m	→ 20 km/h	← 15 km/h	← 25 km/h	↙ 25 km/h

Épaisseur de neige hors-piste

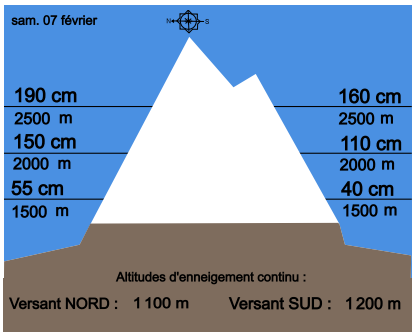

Précipitations à 1800 m

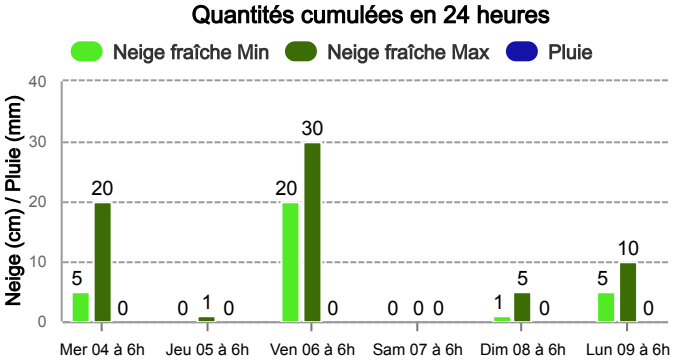

Tendance du lundi 09 février

3 **Indice de risque marqué**

Maintien d'un risque marqué. Des instabilités sont encore en place et localement facilement déclenchables. La situation météorologique évolue peu avec un ciel restant majoritairement nuageux, mais des précipitations faibles et éparses.

Pour consulter la vigilance en cours, veuillez vous rendre sur le site https://vigilance.meteofrance.fr/fr

Météo-France - 73 avenue de Paris, 94165 Saint-Mandé cedex - Contact : contact@meteo.fr

Rédigé par Météo-France avec la contribution des observateurs du réseau nivo-météorologiques. Partenariat : ANMSM (Maires de Stations de Montagne), DSF (Domaines Skiables de France), ADSP (Directeurs de Pistes et de la Sécurité des Stations de Sports d'Hiver) et autres acteurs de la montagne.

Bulletin neige & avalanches par téléphone au **0 892 68 10 20** Service 0,35 € / min + prix appel

RÉPUBLIQUE FRANÇAISE
Liberté Égalité Fraternité

METEO FRANCE
À VOS CÔTÉS, DANS UN CLIMAT QUI CHANGE

Bulletin d'estimation du risque d'avalanche

(valable en dehors des pistes balisées et ouvertes)

MASSIF : Mercantour

Rédigé le samedi 7 février 2026 à 16h

Conditions nivo-météo des 7 derniers jours

	dim. 01/02				lun. 02/02				mar. 03/02				mer. 04/02				jeu. 05/02				ven. 06/02				sam. 07/02			
	03h	09h	15h	21h	03h	09h	15h	21h	03h	09h	15h	21h	03h	09h	15h	21h	03h	09h	15h	21h	03h	09h	15h	21h	03h	09h	15h	21h
Météo																												
Vent (km/h)	15	15	20	20	25	35	45	60	75	50	35	30	35	20	25	25	35	40	40	45	40	45	40	30	35	15	15	15
à 3000m																												
Vent (km/h)	15	10	10	10	10	10	20	25	25	40	25	15	15	25	15	10	15	15	25	20	35	20	20	15	15	10	15	15
à 2000m																												

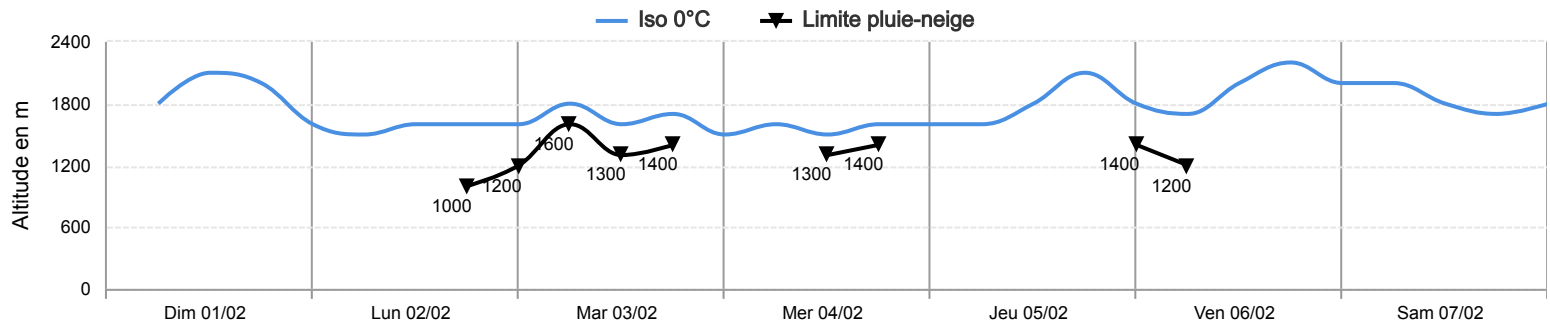

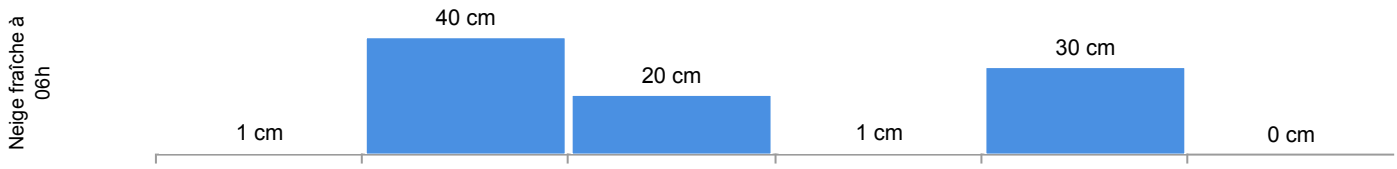

Risque d'avalanche	dim. 01/02	lun. 02/02	mar. 03/02	mer. 04/02	jeu. 05/02	ven. 06/02	sam. 07/02
	3	3	4	4	3	4	3

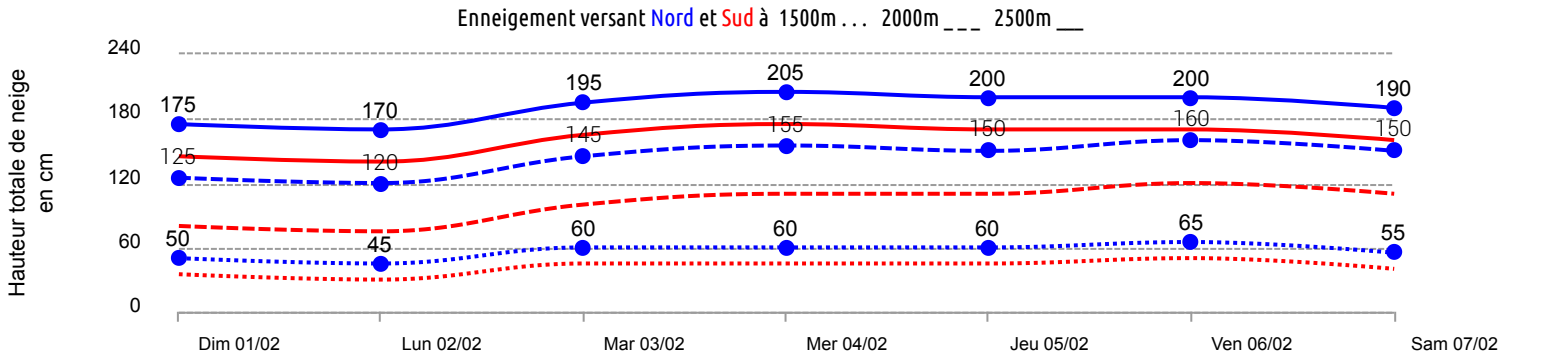

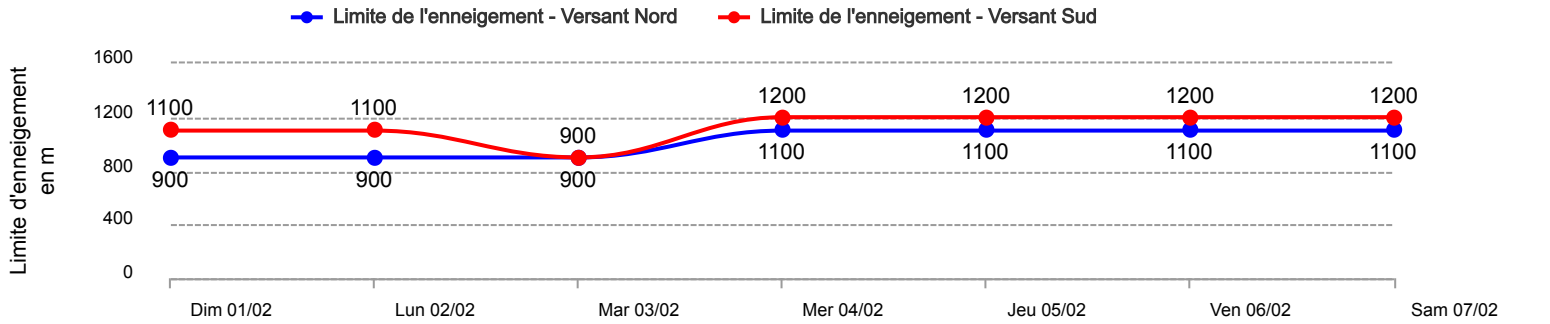

Pour consulter la vigilance en cours, veuillez vous rendre sur le site https://vigilance.meteofrance.fr/fr

Météo-France - 73 avenue de Paris, 94165 Saint-Mandé cedex - Contact : contact@meteo.fr

Rédigé par Météo-France avec la contribution des observateurs du réseau nivo-météorologiques. Partenariat : ANMSM (Maires de Stations de Montagne), DSF (Domaines Skiables de France), ADSP (Directeurs de Pistes et de la Sécurité des Stations de Sports d'Hiver) et autres acteurs de la montagne.

Bulletin neige & avalanches par téléphone au

0 892 68 10 20 Service 0,35 € / min + prix appel