Bulletin d'estimation du risque d'avalanche
(valable en dehors des pistes balisées et ouvertes)
MASSIF : Vercors

Rédigé le samedi 7 février 2026 à 16h

Estimation des risques pour le : DIMANCHE 08 FÉVRIER

RARES PLAQUES VERS LES HAUTES CRETES, EN PENTES OMBRAGEES...

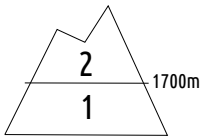

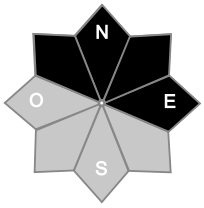

Altitude/localisées

Au-dessus de 1700m indice de risque limité, plus bas indice faible.

Départs spontanés : Rare coulée ponctuelle au soleil, en pentes herbeuses, rare avalanche de glissement (de taille moyenne)

Déclenchements provoqués : Rares plaques instables en faces sommitales, ombragées...

Indices de risque : 5 très fort - 4 fort - 3 marqué - 2 limité - 1 faible -- En noir : les pentes les plus dangereuses

Stabilité du manteau neigeux

Situation avalancheuse typique : neige ventée avalanches de fond

Tassement relatif du manteau neigeux, notamment plus bas que 1700/1900m.

Déclenchements provoqués :
Risque de plaque de plus en plus rare, plutôt à proximité des crêtes d'altitude et en faces ombragées. Noter qu'une cassure plus épaisse n'est pas totalement exclue en contrebas, donnant une avalanche de moyenne taille.
Indices observables : Transition crêtes dégarnies/faces chargées, mais la neige la plus récente dissimule parfois les accumulations de jeudi soir...
Plus bas que 1700/1800m le récent redoux a crouté la neige en surface, peu de risque accidentel mais ski parfois délicat...

Départs spontanés :
Peu d'activé attendue, ou de rares départs humides ponctuels lors d'éclaircies, près des rochers.
En pentes herbeuses raides fissurées, une rare avalanche de glissement (ou de fond) n'est pas exclue, notamment sous 1700m, d'ampleur moyenne (taille 2), et ce plutôt l'après-midi ou le soir.

Qualité de la neige

Qualification de l'enneigement : L'enneigement s'est récemment dégradé aux basses altitudes mais reste correct pour la saison dès la moyenne montagne et dans les combes ombragées du Vercors
Limites skiables : Vers 1100/1400 m, sur les pistes forestières/clairières...

Qualité de la neige dimanche : Sous 1700/1900m et au Sud, neige croutée par regel , s'humidifiant lors de brèves éclaircies (ski parfois difficile en pentes peu tracées) . En faces Nord d'altitude reste un peu de neige poudreuse, reposant sur des sous couches plus ventées...

Aperçu météo pour le dimanche 08 février

	nuit	matin	après-midi	soir

Temps calme et sec, avec des voiles nuageux élevés un peu plus denses en cours d'après-midi...

Pluie-Neige				
Iso 0 °C	1 700 m	1 900 m	1 800 m	1 600 m
Vent 1500 m	15 km/h	20 km/h	20 km/h	15 km/h
Vent 2000 m	25 km/h	20 km/h	25 km/h	20 km/h

Épaisseur de neige hors-piste

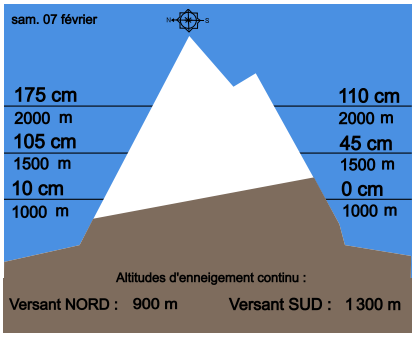

Précipitations à 1800 m

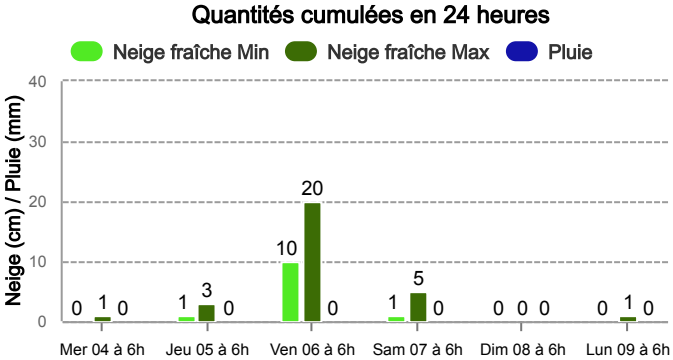

Tendance du lundi 09 février

Indice de risque limité

Lundi, Risque d'avalanche en légère hausse. Un peu de vent de Sud vers les hautes crêtes, possibles formations de nouvelles petites plaques en faces Nord ?

Pour consulter la vigilance en cours, veuillez vous rendre sur le site https://vigilance.meteofrance.fr/fr

Météo-France - 73 avenue de Paris, 94165 Saint-Mandé cedex - Contact : contact@meteo.fr

Rédigé par Météo-France avec la contribution des observateurs du réseau nivo-météorologiques. Partenariat : ANMSM (Maires de Stations de Montagne), DSF (Domaines Skiables de France), ADSP (Directeurs de Pistes et de la Sécurité des Stations de Sports d'Hiver) et autres acteurs de la montagne.

Bulletin neige & avalanches par téléphone au
0 892 68 10 20 Service 0,35 € / min + prix appel

RÉPUBLIQUE FRANÇAISE
Liberté Égalité Fraternité

METEO FRANCE
À VOS CÔTÉS, DANS UN CLIMAT QUI CHANGE

Bulletin d'estimation du risque d'avalanche
(valable en dehors des pistes balisées et ouvertes)

MASSIF : Vercors

Rédigé le samedi 7 février 2026 à 16h

Conditions nivo-météo des 7 derniers jours

	dim. 01/02				lun. 02/02				mar. 03/02				mer. 04/02				jeu. 05/02				ven. 06/02				sam. 07/02			
	03h	09h	15h	21h	03h	09h	15h	21h	03h	09h	15h	21h	03h	09h	15h	21h	03h	09h	15h	21h	03h	09h	15h	21h	03h	09h	15h	21h
Météo																												
Vent (km/h)	20	20	20	20	25	55	80	120	125	90	75	70	45	50	50	30	25	35	50	45	55	25	25	15	15	15	15	10
à 2000m	↓	↙	↓	↗	↑	↑	↑	↑	↑	↑	↑	↑	↑	↑	↑	↑	↑	↑	↑	↑	↑	↘	↘	↘	↗	↓	↙	↙
Vent (km/h)	15	15	15	15	15	35	65	100	110	75	55	50	40	45	40	25	25	20	45	30	20	20	20	10	10	10	15	10
à 1500m	↓	↓	↘	↑	↑	↑	↑	↑	↑	↑	↑	↑	↑	↑	↑	↑	↑	↑	↑	↑	↗	→	→	↓	↙	↖	↓	↙

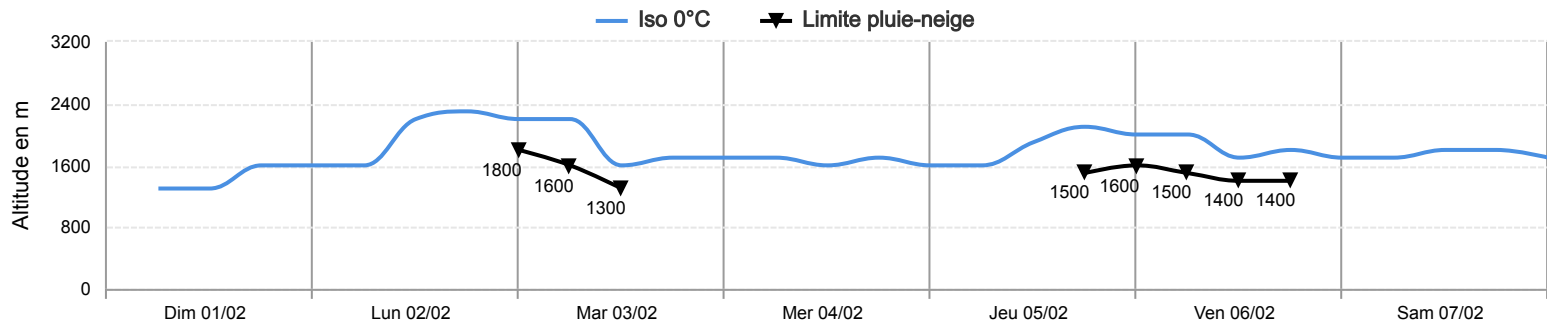

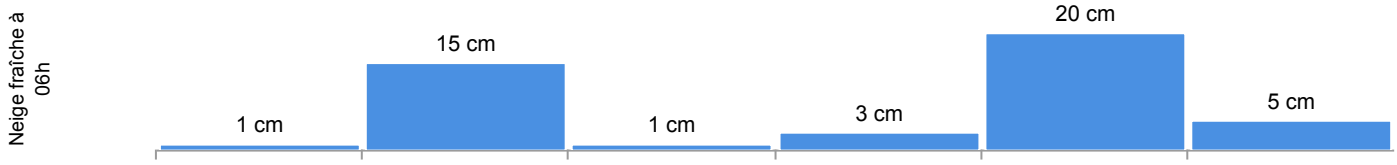

Risque d'avalanche	dim. 01/02	lun. 02/02	mar. 03/02	mer. 04/02	jeu. 05/02	ven. 06/02	sam. 07/02
	2	3	3	3	3	3	3

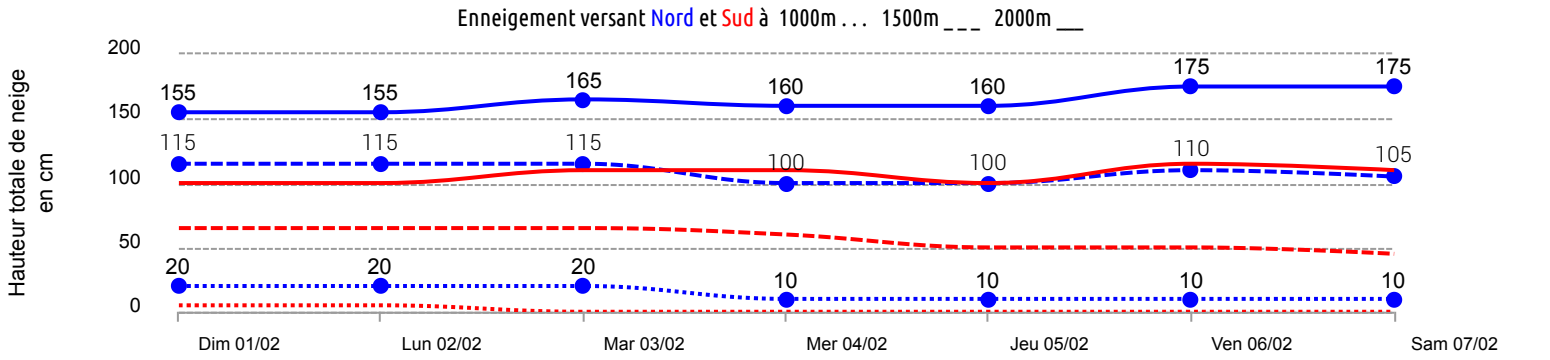

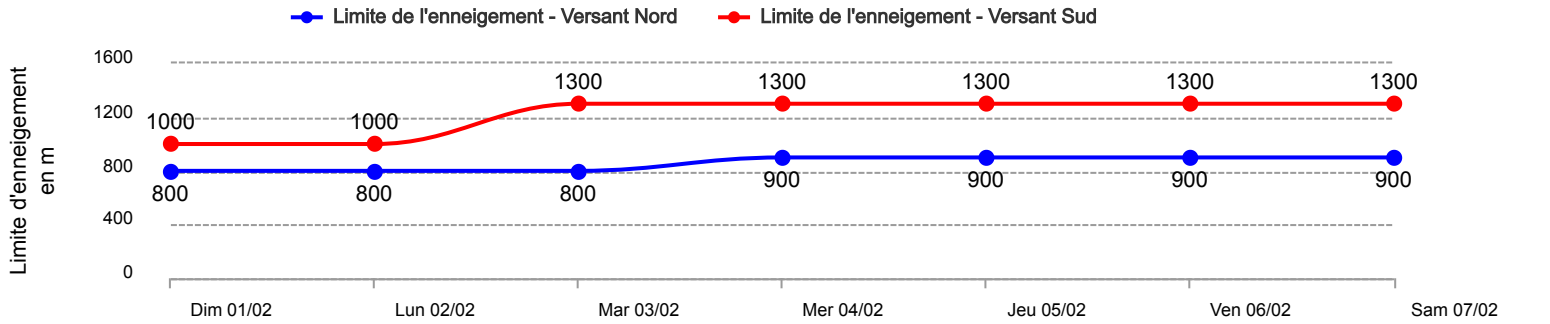

Pour consulter la vigilance en cours, veuillez vous rendre sur le site https://vigilance.meteofrance.fr/fr

Météo-France - 73 avenue de Paris, 94165 Saint-Mandé cedex - Contact : contact@meteo.fr

Bulletin neige & avalanches par téléphone au **0 892 68 10 20** Service 0,35 € / min + prix appel

Rédigé par Météo-France avec la contribution des observateurs du réseau nivo-météorologiques. Partenariat : ANMSM (Maires de Stations de Montagne), DSF (Domaines Skiables de France), ADSP (Directeurs de Pistes et de la Sécurité des Stations de Sports d'Hiver) et autres acteurs de la montagne.