Bulletin d'estimation du risque d'avalanche
(valable en dehors des pistes balisées et ouvertes)

MASSIF : Aspe Ossau

Rédigé le samedi 7 février 2026 à 17h

Estimation des risques pour le : DIMANCHE 08 FÉVRIER

NEIGE VENTÉE, RARES COUCHES FRAGILES PERSISTANTES ENFOUIES

2

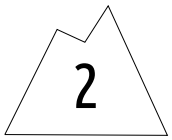

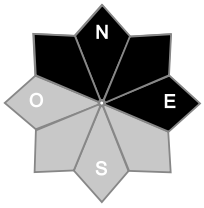

Neige ventée.

Indices de risque : 5 très fort - 4 fort - 3 marqué - 2 limité - 1 faible -- En noir : les pentes les plus dangereuses

Indice de risque limité.

Départs spontanés : Rares, petits départs ponctuels ou éventuellement linéaires

Déclenchements provoqués : Plaques au-dessus de 2000m en nord à est, couches fragilles enfouies en secteurs froids.

Stabilité du manteau neigeux

Situation avalancheuse typique : neige ventée couche fragile persistante

Déclenchements provoqués : Plaques en place parfois loin des crêtes, cols et sommets dans les secteurs déventés Nord-à Est, formées par les épisodes successifs de vent fort de sud-ouest, devenant moins facilement déclenchables avec le tassement. Elles sont plus fréquentes et épaisses dans les secteurs frontaliers du cirque d'Anéou au Palas.
De nouvelles se forment en journée de dimanche avec les chutes de neige en expositions à l'abri du vent d'ouest. Elles peuvent être assez facilement déclenchables, mais restent le plus souvent de faible épaisseur et engendrent rarement une avalanche de taille moyenne. Elles sont plutôt proches des crêtes, formées par un vent modéré.
Dans les secteurs froids bien ombragés au-dessus de 2000m, des couches fragiles sont en place dans certains secteurs. Elles sont difficilement déclenchables car enfouies assez profondément, mais leur sollicitation, parfois possible là où l'épaisseur de neige est moins importante (abords des combes, ruptures de pente), peut engendrer des avalanches avec des cassures de plus de 50cm.

Départs spontanés :
- Déclenchement spontané entre samedi soir et dimanche matin possible de plaques sous l'effet vent de sud-ouest, avec des départs linéaires dans les expositions nord-est en général, en général de taille moyenne.
- Petits départs ponctuels en pentes raides dimanche pendant les chutes de neige, plutôt en versants est où les accumulations peuvent être suffisantes.

Autres :
Corniches souvent imposantes au-dessus des pentes est

Qualité de la neige

Enneigement : bon pour la saison, mais les crêtes, cols et sommets en expositions ouest sont souvent pelés par le vent dans les expositions ouest. Accumulations plus importantes en secteurs frontaliers.
Limites skiables : manteau neigeux skiable à partir de 1300-1400m en nord.
État de la neige : Le manteau existant est humidifié et regelé sous 1800m et plus haut en sud. Au-dessus de 1800m en nord, neige sèche tassée travaillée par le vent, la glace ou les rochers affleurent dans les zones ventées. Au-dessus de 1600m, on peut trouver une fine couche de neige fraîche dans les endroits abrités du vent de sud.
Le manteau évolue peu ensuite, dans une ambiance restant fraîche et nuageuse après les éclaircies fugaces du début de journée. Quelques centimètres supplémentaires se déposent en journée.

Aperçu météo pour le dimanche 08 février

	nuit	matin	après-midi	soir
	Quelques éclaircies en tout début de journée, puis le relief se bouche à nouveau, quelques chutes de neige			
Pluie-Neige	1 500 m	1 500 m	1 300 m	1 200 m
Iso 0 °C	1 900 m	1 700 m	1 700 m	1 500 m
Vent 1500 m	↑ 40 km/h	→ 15 km/h	→ 30 km/h	↑ 20 km/h
Vent 3000 m	↑ 60 km/h	↘ 30 km/h	↘ 35 km/h	↘ 20 km/h

Épaisseur de neige hors-piste

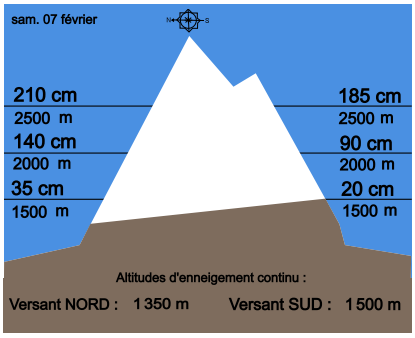

Précipitations à 1800 m

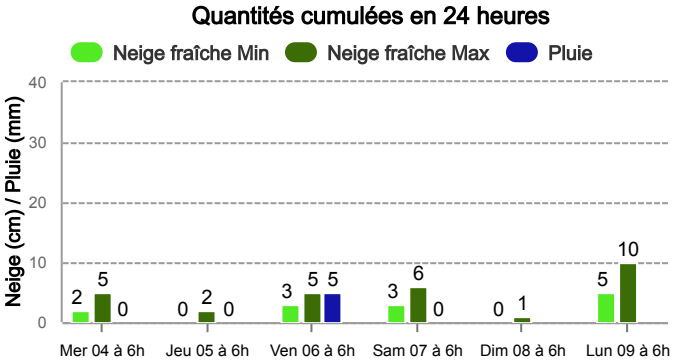

Tendance du lundi 09 février

2

Indice de risque limité

Nouvelles chutes de neige limitant la stabilisation

Pour consulter la vigilance en cours, veuillez vous rendre sur le site https://vigilance.meteofrance.fr/fr

Météo-France - 73 avenue de Paris, 94165 Saint-Mandé cedex - Contact : contact@meteo.fr

Rédigé par Météo-France avec la contribution des observateurs du réseau nivo-météorologiques. Partenariat : ANMSM (Maires de Stations de Montagne), DSF (Domaines Skiables de France), ADSP (Directeurs de Pistes et de la Sécurité des Stations de Sports d'Hiver) et autres acteurs de la montagne.

Bulletin neige & avalanches par téléphone au
0 892 68 10 20 Service 0,35 € / min + prix appel

RÉPUBLIQUE FRANÇAISE
Liberté Égalité Fraternité

METEO FRANCE
À VOS CÔTÉS, DANS UN CLIMAT QUI CHANGE

Bulletin d'estimation du risque d'avalanche

(valable en dehors des pistes balisées et ouvertes)

MASSIF : Aspe Ossau

Rédigé le samedi 7 février 2026 à 17h

Conditions nivo-météo des 7 derniers jours

	dim. 01/02				lun. 02/02				mar. 03/02				mer. 04/02				jeu. 05/02				ven. 06/02				sam. 07/02			
	03h	09h	15h	21h	03h	09h	15h	21h	03h	09h	15h	21h	03h	09h	15h	21h	03h	09h	15h	21h	03h	09h	15h	21h	03h	09h	15h	21h
Météo																												
Vent (km/h)	40	40	45	50	70	115	110	80	40	45	80	90	95	100	60	55	75	110	90	80	75	60	55	60	55	50	50	75
à 3000m																												
Vent (km/h)	25	20	20	35	50	80	80	45	30	25	30	50	60	40	20	35	60	80	70	55	45	40	40	40	40	35	30	35
à 1500m																												

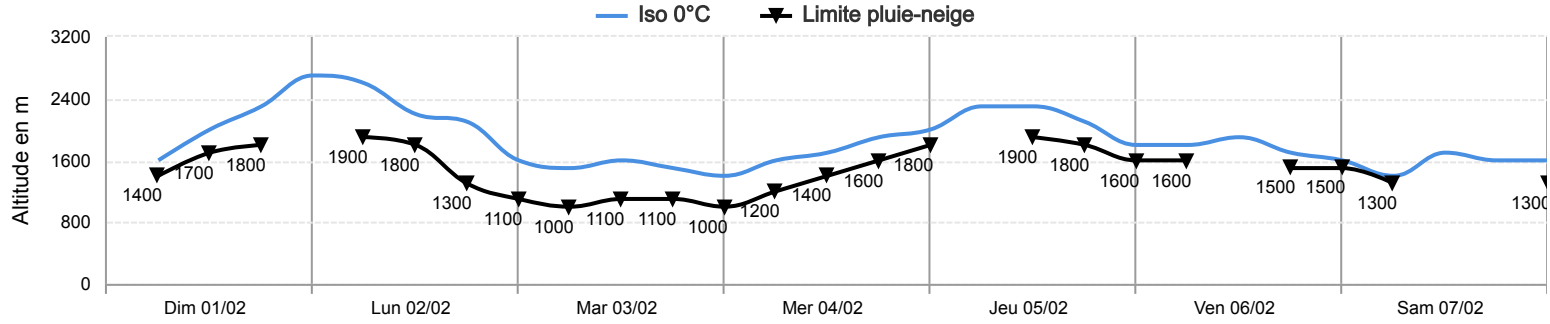

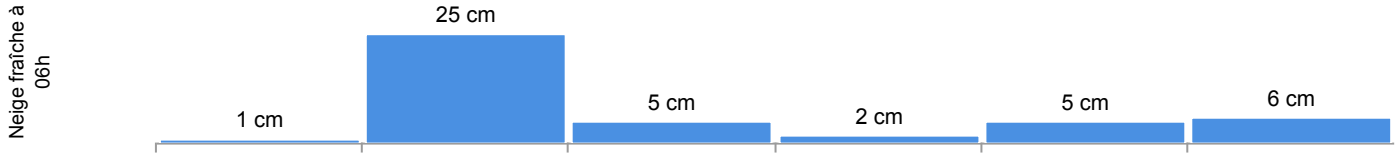

Risque d'avalanche	dim. 01/02	lun. 02/02	mar. 03/02	mer. 04/02	jeu. 05/02	ven. 06/02	sam. 07/02
	4	3	3	3	3	3	2

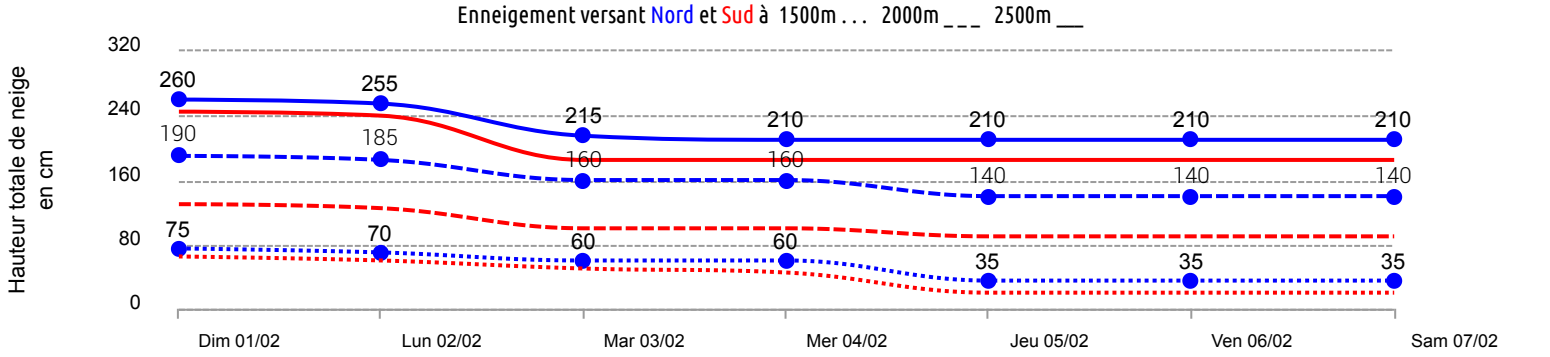

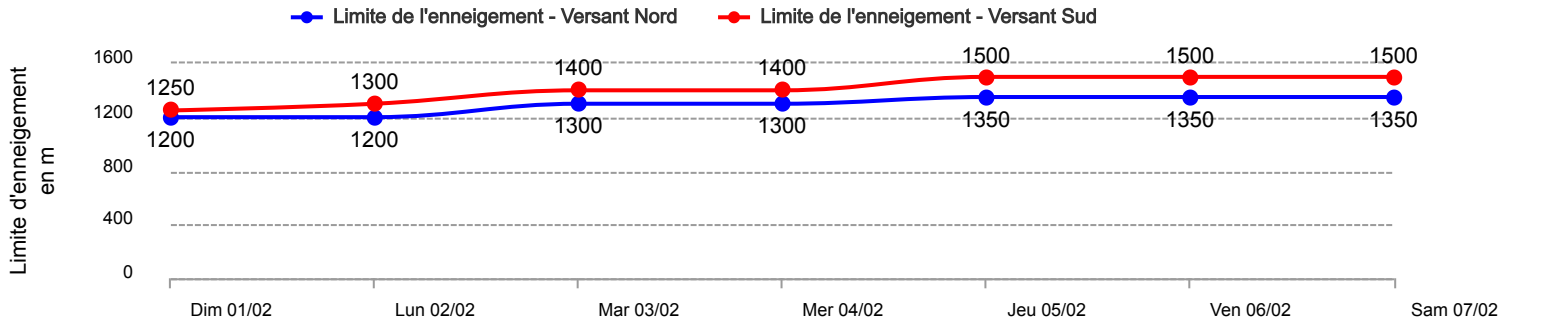

Pour consulter la vigilance en cours, veuillez vous rendre sur le site https://vigilance.meteofrance.fr/fr

Météo-France - 73 avenue de Paris, 94165 Saint-Mandé cedex - Contact : contact@meteo.fr

Rédigé par Météo-France avec la contribution des observateurs du réseau nivo-météorologiques. Partenariat : ANMSM (Maires de Stations de Montagne), DSF (Domaines Skiables de France), ADSP (Directeurs de Pistes et de la Sécurité des Stations de Sports d'Hiver) et autres acteurs de la montagne.

Bulletin neige & avalanches par téléphone au
0 892 68 10 20 Service 0,35 € / min + prix appel