Bulletin d'estimation du risque d'avalanche

(valable en dehors des pistes balisées et ouvertes)

MASSIF : Pays-Basque

Rédigé le samedi 7 février 2026 à 17h

Estimation des risques pour le : DIMANCHE 08 FÉVRIER

QUELQUES PLAQUES AU PLUS HAUT DU MASSIF, HUMIDIFICATION AUX ALTITUDES BASSES

2

2

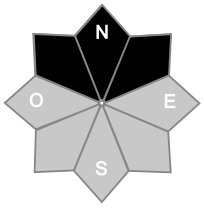

Indice de risque limité.

Départs spontanés : Rares, en neige humide sous 1500m, un départ linéaire en altitude possible

Déclenchements provoqués : Plaques peu épaisses en Nord à Est au-dessus de 1800 m.

Indices de risque : 5 très fort - 4 fort - 3 marqué - 2 limité - 1 faible -- En noir : les pentes les plus dangereuses

Stabilité du manteau neigeux

Situation avalancheuse typique : neige ventée — neige humide

Déclenchements provoqués : Au plus haut du massif, en général au-dessus de 1800m, des plaques se situent dans les expositions ombragées, formées par les épisodes successifs de vent de sud. Elles sont peu épaisses, parfois encore déclenchables, même si le manteau se stabilise peu à peu par tassement. De nouvelles se forment en journée, dans les expositions est, mais n'atteignent probablement pas une épaisseur suffisante pour bousculer un pratiquant.

Départs spontanés : Rares, principalement dans la nuit de samedi à dimanche, sous l'effet du vent et de quelques précipitations.
- en neige sèche dans les versants Nord d'altitude, un départ linéaire est possible sur une faible épaisseur
- en neige humide : Quelques départs de petite taille sous les faibles pluies sous 1500m environ

L'activité spontanée diminue dimanche avec une nouvelle baisse du vent et de l'iso 0°C.

Qualité de la neige

Enneigement : bon pour la saison, mais les crêtes, cols et sommets sont souvent pelés par le vent dans les expositions ouest.
Limites skiables : manteau neigeux skiable à partir de 1400m en nord, 1500 en sud.
État de la neige : Le manteau existant est humidifié sous 1800m et plus haut en sud. Au-dessus de 1800m en nord, neige sèche tassée travaillée par le vent, la glace ou les rochers affleurent dans les zones ventées. Au-dessus de 1600m, on peut trouver une fine couche de neige fraîche dans les endroits abrités du vent de sud.
Le manteau évolue peu en journée, dans une ambiance restant fraîche et nuageuse après les éclaircies fugaces du début de journée.

Aperçu météo pour le dimanche 08 février

Quelques éclaircies en tout début de journée, puis le relief se bouche à nouveau, quelques chutes de neige

	nuit	matin	après-midi	soir
Pluie-Neige	1 400 m	1 300 m	1 300 m	
Iso 0 °C	1 700 m	1 600 m	1 500 m	1 600 m
Vent 1000 m	60 km/h	25 km/h	35 km/h	20 km/h
Vent 2000 m	90 km/h	40 km/h	45 km/h	30 km/h

Épaisseur de neige hors-piste

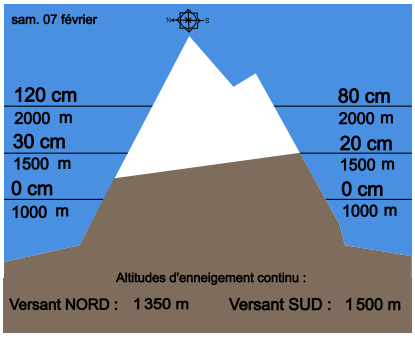

Précipitations à 1800 m

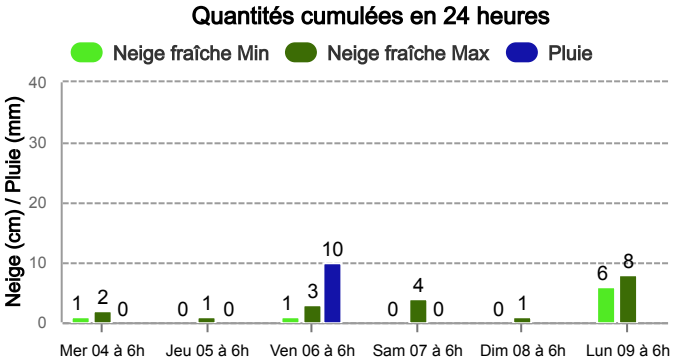

Tendance du lundi 09 février

2

Indice de risque limité

Augmentation du risque en neige humide avec le redoux, mais taille des avalanches encore limitée lundi

Pour consulter la vigilance en cours, veuillez vous rendre sur le site https://vigilance.meteofrance.fr/fr

Météo-France - 73 avenue de Paris, 94165 Saint-Mandé cedex - Contact : contact@meteo.fr

Rédigé par Météo-France avec la contribution des observateurs du réseau nivo-météorologiques. Partenariat : ANMSM (Maires de Stations de Montagne), DSF (Domaines Skiables de France), ADSP (Directeurs de Pistes et de la Sécurité des Stations de Sports d'Hiver) et autres acteurs de la montagne.

Bulletin neige & avalanches par téléphone au 0 892 68 10 20 Service 0,35 € / min + prix appel

RÉPUBLIQUE FRANÇAISE
Liberté Égalité Fraternité

METEO FRANCE
À VOS CÔTÉS, DANS UN CLIMAT QUI CHANGE

Bulletin d'estimation du risque d'avalanche
(valable en dehors des pistes balisées et ouvertes)
MASSIF : Pays-Basque

Rédigé le samedi 7 février 2026 à 17h

Conditions nivo-météo des 7 derniers jours

	dim. 01/02				lun. 02/02				mar. 03/02				mer. 04/02				jeu. 05/02				ven. 06/02				sam. 07/02			
	03h	09h	15h	21h	03h	09h	15h	21h	03h	09h	15h	21h	03h	09h	15h	21h	03h	09h	15h	21h	03h	09h	15h	21h	03h	09h	15h	21h
Météo																												
Vent (km/h)	70	45	50	80	95	120	120	80	80	80	65	80	100	85	65	70	90	130	95	90	95	95	80	70	70	70	80	90
à 2000m																												
Vent (km/h)	30	30	40	60	60	90	90	55	55	55	40	45	50	40	45	60	80	90	65	60	75	70	60	50	55	55	60	65
à 1000m																												

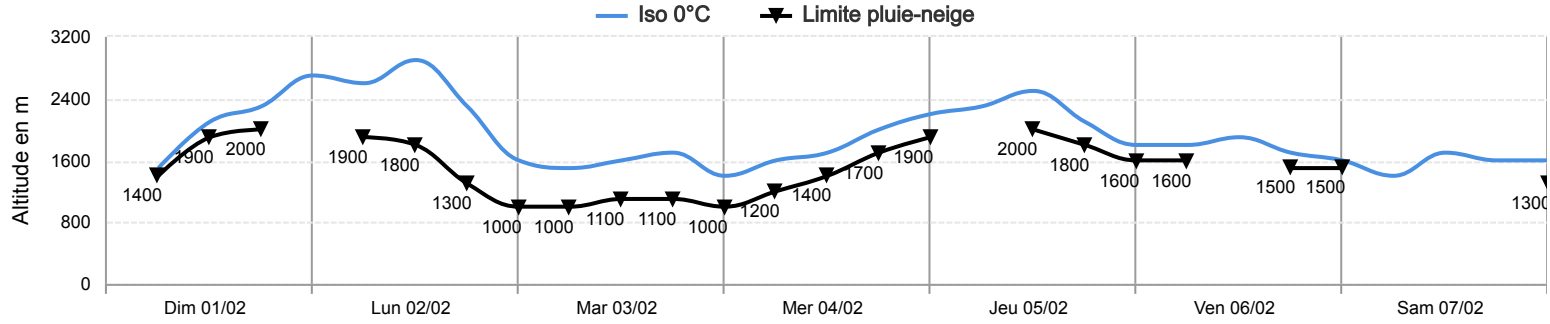

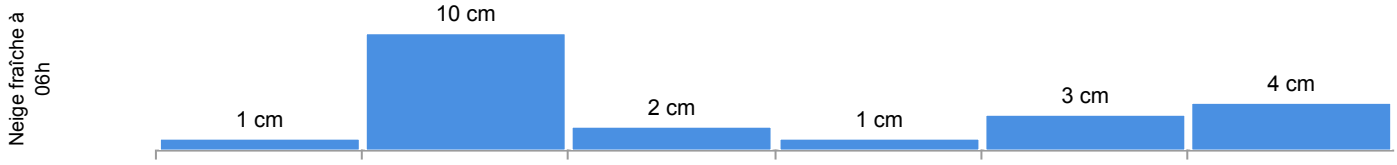

Risque d'avalanche	dim. 01/02	lun. 02/02	mar. 03/02	mer. 04/02	jeu. 05/02	ven. 06/02	sam. 07/02
	3	3	2	2	2	2	2

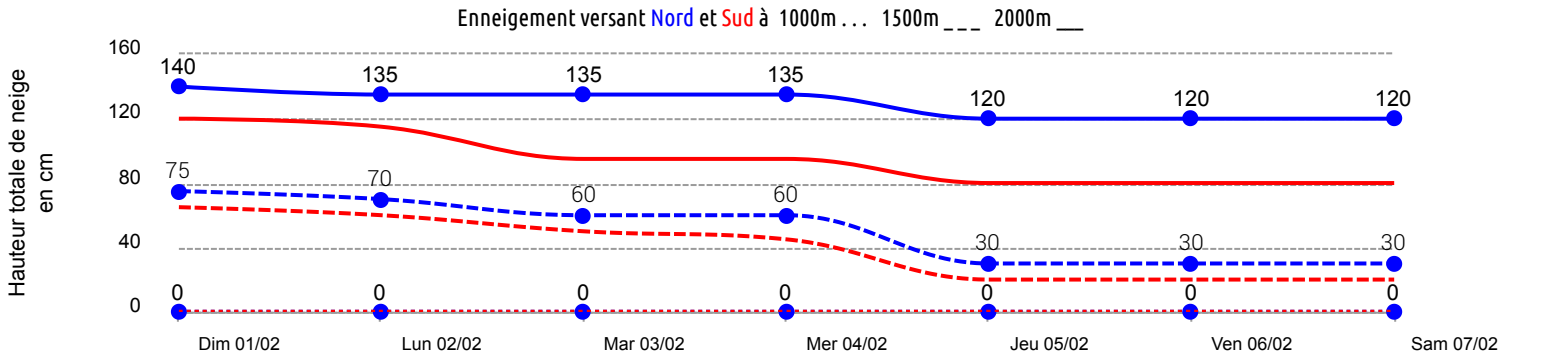

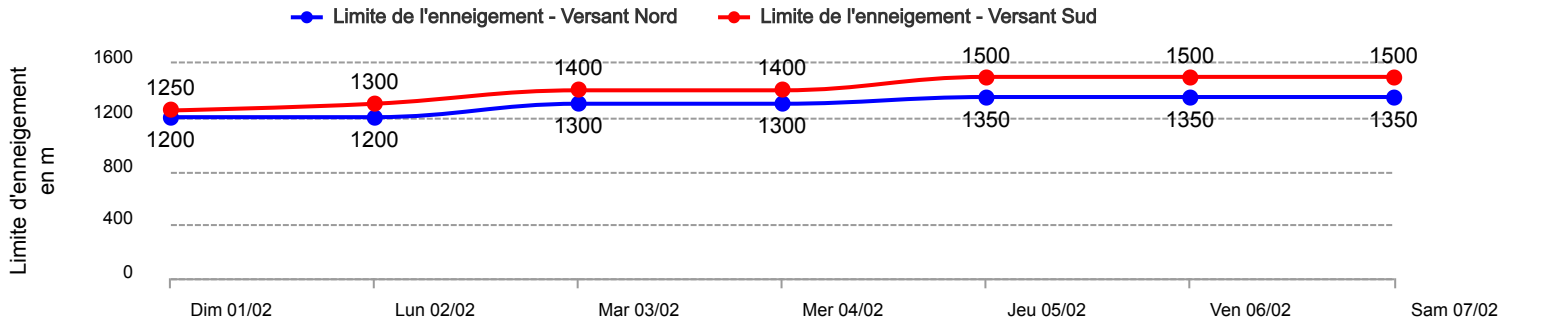

Pour consulter la vigilance en cours, veuillez vous rendre sur le site https://vigilance.meteofrance.fr/fr

Météo-France - 73 avenue de Paris, 94165 Saint-Mandé cedex - Contact : contact@meteo.fr

Rédigé par Météo-France avec la contribution des observateurs du réseau nivo-météorologiques. Partenariat : ANMSM (Maires de Stations de Montagne), DSF (Domaines Skiables de France), ADSP (Directeurs de Pistes et de la Sécurité des Stations de Sports d'Hiver) et autres acteurs de la montagne.

Bulletin neige & avalanches par téléphone au

0 892 68 10 20 Service 0,35 € / min + prix appel