GOBIERNO DE ESPAÑA
VICEPRESIDENCIA TERCERA DEL GOBIERNO
MINISTERIO PARA LA TRANSICIÓN ECOLÓGICA Y EL RETO DEMOGRÁFICO

Boletín de información nivológica y de peligro de aludes

Pirineo Catalán

aemet Agencia Estatal de Meteorología

domingo, 8 de febrero de 2026

Pronóstico hasta las 24 horas del lunes, día 9 de febrero

(Válido fuera de pistas de esquí balizadas y abiertas)

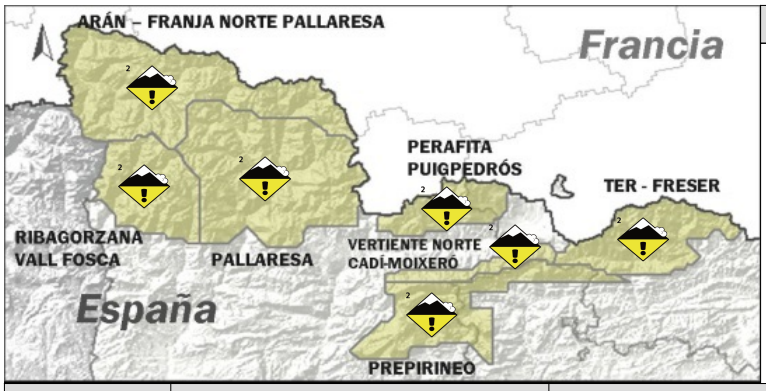

Problemas de aludes

Placas de viento

Nieve reciente

Macizo	Peligro	Problemas de aludes, cota, orientación, tamaño	Innivación observada (m)
Arán - Franja norte Pallaresa	2 Limitado	Placas de viento: 2100, N O E S, 2 Nieve reciente: 1700, N O E S, 2	2026-02-08 N S Cotas bajas
Ribagorzana - Vall Fosca	2 Limitado	Placas de viento: 2100, N O E S, 2 Nieve reciente: 1700, N O E S, 2	2026-02-08 N S Cotas bajas
Pallaresa	2 Limitado	Placas de viento: 2100, N O E S, 2 Nieve reciente: 1700, N O E S, 2	2026-02-08 N S Cotas bajas

AEMET. Se autoriza la reproducción de su contenido citando la fuente.

Boletín de información nivológica y de peligro de aludes

Pirineo Catalán

Perafita - Puigpedrós	2 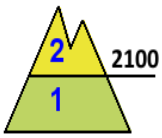 **Limitado**	**Placas de viento** 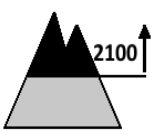  **Nieve reciente** 	2026-02-08 Cotas bajas
Ter - Freser	2 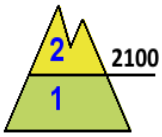 **Limitado**	**Placas de viento** 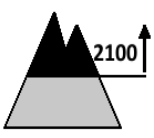 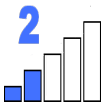 **Nieve reciente** 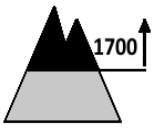 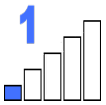	2026-02-08 Cotas bajas
Vertiente norte Cadí - Moixeró	2 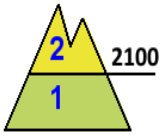 **Limitado**	**Placas de viento**  **Nieve reciente** 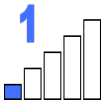	2026-02-08 Cotas bajas
Prepirineo	2 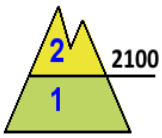 **Limitado**	**Placas de viento** 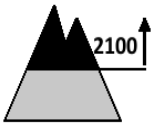 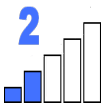 **Nieve reciente** 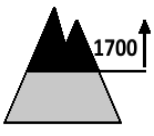 	2026-02-08 Cotas bajas

Estado del manto y observaciones recientes

El paso de sucesivas borrascas asociadas al chorro polar, está dejando abundantes precipitaciones en la cordillera desde hace semanas, si bien en las últimas 24 horas las nevadas han sido débiles, lo que ha supuesto incrementos discretos de los espesores en algunas zonas, mientras que en otras se han registrado pérdidas de algunos centímetros.

AEMET. Se autoriza la reproducción de su contenido citando la fuente.

El manto es continuo desde cotas bajas, con espesores que, por lo general, están muy por encima de lo que sería habitual para esta época del año. A 2200-2400 metros se alcanzan los 120-200 cm, aún más en ventisqueros, hoyas y otras zonas propensas a la acumulación.

En cotas altas la nieve se mantiene seca y muy venteada, con numerosas placas en muchas orientaciones. Además, en zonas de umbría, todavía pueden persistir estratos débiles.

Evolución del manto y peligro de aludes para el lunes, día 9

Problema de placas de viento y capas débiles persistentes en cotas altas. Problema de nieve reciente, que irá dando paso a problema de nieve húmeda en cota medias y bajas.

En las próximas horas van a continuar las precipitaciones débiles, de nieve por encima de unos 1100-1200 metros, que serán más probables e intensas en los macizos occidentales al final del lunes, cuando la cota de nieve ascenderá hasta unos 1700-1800 metros. En cotas altas se esperan unos 10-20 cm en el sector occidental y 5-10 cm en el oriental, localmente más. A altitudes inferiores las cantidades serán menores, ya que lloverá al final del episodio. Así, serán frecuentes las purgas de nieve reciente en las laderas suficientemente inclinadas, de tamaño pequeño (riesgo de caída) o mediano (capaz de enterrar a una persona). A partir del mediodía también podrán producirse aludes de nieve húmeda, primero en cotas bajas y posteriormente en medias, generalmente de tamaño 1.

El viento fuerte de componente oeste volverá a formar placas en diferentes áreas de cotas altas, aunque con preferencia en vertientes este. Estas se sumarán a las ya existentes, que abarcan todas las orientaciones, y que en algunos casos son difíciles de localizar al haber quedado ocultas por las nevadas de los últimos días. Todas estas estructuras permanecerán frágiles y podrán fracturar ante una sobrecarga débil (paso de un solo esquiador), provocando aludes medianos, aunque sin descartar que en algún caso aislado puedan llegar a ser grandes.

Por último hacer notar que en las umbrías de alta montaña no se descarta la existencia de capas débiles persistentes, especialmente en enclaves con un manto delgado, que en caso de colapsar podrían ocasionar aludes grandes.

Predicción meteorológica para el lunes, día 9

Intervalos nubosos, aumentando a muy nuboso o cubierto en el transcurso del día. Periodos de visibilidad localmente reducida. Se esperan precipitaciones débiles, principalmente al final del día, siendo más probables en los macizos occidentales. Cota de nieve en ascenso, de 1500 a 1700-1800 metros. Temperaturas mínimas sin cambios o en ligero descenso, y máximas sin cambios o en ligero ascenso, más acusado en el Arán. Heladas débiles o moderadas, que serán localmente fuertes y persistentes en cotas altas. Viento de componente oeste, moderado aumentando a fuerte, con alguna racha muy fuerte en cotas altas y zonas expuestas a últimas horas.

AEMET. Se autoriza la reproducción de su contenido citando la fuente.

Datos en la atmósfera libre:

Altitud de la isoterma de 0 ºC: 1900 m
Altitud de la isoterma de -10 ºC: 3700 m

Viento a 1500 m: W 30 km/h
Viento a 3000 m: NW 60 km/h (W) - NW 30 km/h (E)

Evolución para el martes día 10

En aumento. En cotas medias y bajas se incrementará el peligro por nieve húmeda, mientras que en cotas altas se acentuarán los problemas de nieve reciente y placas de viento.

Escala europea de peligro de aludes

Débil | Limitado | Notable | Fuerte | Muy Fuerte

Problemas de aludes

Nieve reciente | Placas de viento | Capas débiles persistentes | Nieve húmeda | Deslizamientos basales | Sin problema evidente

Nota1: Se recuerda que, siempre que haya nieve, la ausencia total de peligro no existe. Hay que tener presente que en circunstancias desfavorables, con aludes de tamaño 1 (alud pequeño o colada) y tamaño 2 (alud mediano), se pueden sufrir severos daños personales.

Nota2: Los BPA se elaboran en base a información meteorológica así como al estado del manto nivoso a través de sondeos puntuales. Se advierte a los usuarios de la variabilidad de esta información al extrapolarla a zonas extensas de montaña. Por ello, AEMET no se hace responsable de su uso para la toma de decisiones que conciernen a la seguridad personal, ni de los riesgos físicos o materiales de ellas derivadas.

AEMET. Se autoriza la reproducción de su contenido citando la fuente.