GOBIERNO DE ESPAÑA
VICEPRESIDENCIA TERCERA DEL GOBIERNO
MINISTERIO PARA LA TRANSICIÓN ECOLÓGICA Y EL RETO DEMOGRÁFICO

Boletín de información nivológica y de peligro de aludes

Pirineo Navarro y Aragonés

aemet Agencia Estatal de Meteorología

domingo, 8 de febrero de 2026

Pronóstico hasta las 24 horas del lunes, día 9 de febrero

(Válido fuera de pistas de esquí balizadas y abiertas)

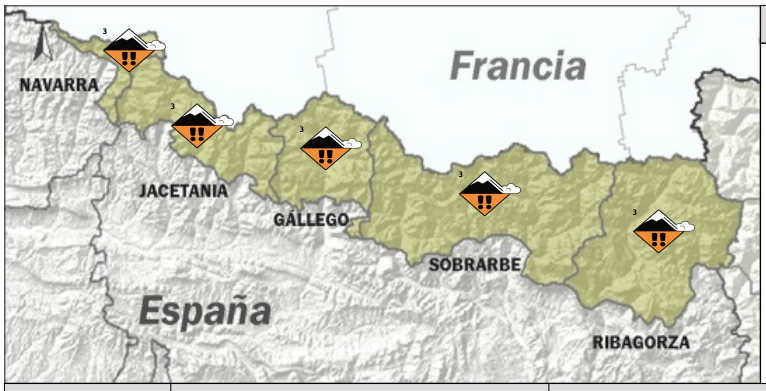

Problemas de aludes

Placas de viento

Nieve reciente

Macizo	Peligro	Problemas de aludes, cota, orientación, tamaño	Innivación observada (m)
Navarra	3 3 / 2 — 2100 Notable	**Placas de viento** 2100 — N, E, S, O — 3 **Nieve reciente** 2000 — N, E, S, O — 2	2026-02-08 N / S Cotas bajas
Jacetania	3 3 / 2 — 2100 Notable	**Placas de viento** 2100 — N, E, S, O — 3 **Nieve reciente** 2000 — N, E, S, O — 2	2026-02-08 N / S Cotas bajas
Gállego	3 3 / 2 — 2100 Notable	**Placas de viento** 2100 — N, E, S, O — 3 **Nieve reciente** 1800 — N, E, S, O — 2	2026-02-08 N / S Cotas bajas

AEMET. Se autoriza la reproducción de su contenido citando la fuente.

Boletín de información nivológica y de peligro de aludes

Pirineo Navarro y Aragonés

Sobrarbe	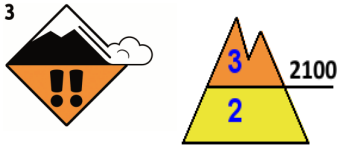 **Notable**	**Placas de viento** 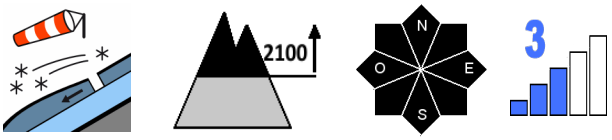 **Nieve reciente** 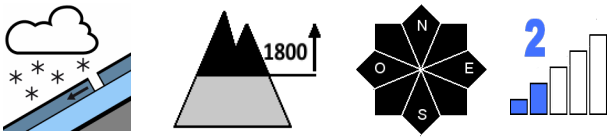	2026-02-08 Cotas bajas
Ribagorza	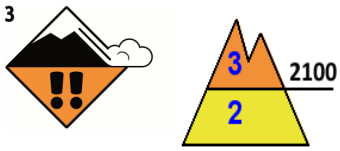 **Notable**	**Placas de viento** 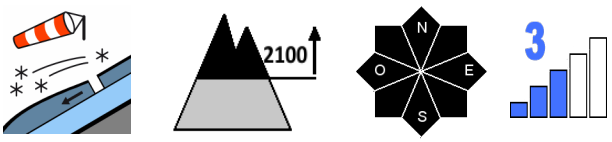 **Nieve reciente** 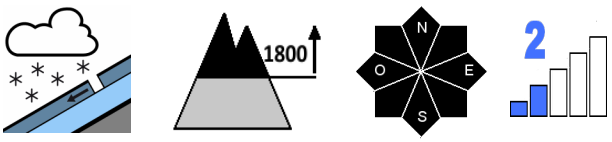	2026-02-08 Cotas bajas

Estado del manto y observaciones recientes

El paso de sucesivas borrascas asociadas al chorro polar, está dejando abundantes precipitaciones en la cordillera desde hace semanas, si bien en las últimas 24 horas las nevadas han sido débiles, lo que ha supuesto depósitos de 1 a 4 cm en algunos puntos de la red de observación, mientras que en otros se han registrado pérdidas, que en algún caso han alcanzado los 10 cm.

El manto es continuo desde cotas bajas, con espesores que, por lo general, están muy por encima de lo que sería habitual para esta época del año. A 1300-1500 metros rondan los 50-100 cm, y se van incrementando conforme ascendemos, de manera que a unos 2100 metros se superan fácilmente los 200-220 cm, aún más en ventisqueros, hoyas y otras zonas propensas a la acumulación.

El perfil del manto consta de una capa superficial de nieve reciente de espesor variable y otras múltiples en el interior donde se van intercalando grano fino o redondo con costras de rehielo. En cotas altas la nieve se mantiene más seca, venteada y menos evolucionada, en particular en zonas de umbría, donde todavía persisten estratos débiles a distintas profundidades, que en algunos casos se sitúan en la base del manto. Además, hay varias generaciones de placas de viento, que abarcan todas las orientaciones, y que todavía se mantienen inestables, pudiendo colapsar ante sobrecargas débiles.

En las últimas 24 horas se han reportado 2 aludes grandes de placa en el Gállego, con salida a 2500-3000 metros y orientación norte y nordeste. Así como varios de nieve reciente en la mayoría de macizos, 4 medianos y 2 pequeños, con salida a 2000-2500 metros en vertientes oeste, nordeste, sur y sureste. También se han reportado algunos disparos positivos en Jacetania, que han desencadenado aludes de nieve húmeda a 2000-2250 metros en orientación oeste.

AEMET. Se autoriza la reproducción de su contenido citando la fuente.

Evolución del manto y peligro de aludes para el lunes, día 9

Problema de placas de viento y capas débiles persistentes en cotas altas. Problema de nieve reciente, que irá dando paso a problema de nieve húmeda en cota medias y bajas.

En las próximas horas van a continuar las precipitaciones débiles, de nieve por encima de unos 1100-1200 metros, que se intensificarán al final del lunes, cuando la cota de nieve ascienda hasta situarse a unos 2000-2100 metros. En cotas altas se esperan unos 20-30 cm en los macizos occidentales y unos 10 cm en el resto, localmente más. A altitudes inferiores las cantidades serán menores, ya que lloverá al final del episodio. Así, serán frecuentes las purgas de nieve reciente en las laderas suficientemente inclinadas, de tamaño pequeño (riesgo de caída) o mediano (capaz de enterrar a una persona), aunque no se descarta que en zonas donde las acumulaciones sean importantes, sobre todo a últimas horas, puedan adquirir dimensiones mayores. A partir del mediodía también podrán producirse aludes de nieve húmeda, primero en cotas bajas y posteriormente en medias, de tamaño 1 o 2.

El viento fuerte de componente oeste volverá a formar placas en diferentes áreas de cotas altas, aunque con preferencia en vertientes este. Estas se sumarán a las ya existentes, que abarcan todas las orientaciones, y que en algunos casos son difíciles de localizar al haber quedado ocultas por las nevadas de los últimos días. Todas estas estructuras permanecerán frágiles y podrán fracturar ante una sobrecarga débil (paso de un solo esquiador), provocando aludes que pueden alcanzar dimensión grande, tamaño suficiente como para enterrar a un grupo de personas.

Además, en las umbrías de la alta montaña podemos encontrar capas débiles persistentes en el interior del manto, que siguen dando muestras de reactividad, especialmente en zonas de poco espesor, y que en caso de colapsar podrían ocasionar aludes grandes, aunque sin descartar que localmente pueda producirse alguno de mayor tamaño.

Predicción meteorológica para el lunes, día 9

Pirineo navarro:

Predominio de cielos muy nubosos o cubiertos, con visibilidad localmente reducida. Se esperan precipitaciones débiles, más frecuentes y generalizadas en la segunda mitad del día, cuando serán moderadas. Cota de nieve en ascenso, de 1100-1200 a 2100 metros. Temperaturas mínimas en ligero descenso o sin cambios, y máximas en ascenso. Heladas débiles, moderadas en cotas altas. Viento de componente oeste, moderado aumentando a fuerte, con rachas muy fuertes en cotas altas y zonas expuestas a últimas horas.

Pirineo aragonés:

Intervalos nubosos de madrugada, aumentando pronto a muy nuboso o cubierto, aunque transitoriamente se podrán abrir algunos claros en las horas centrales. Visibilidad localmente reducida. Se esperan precipitaciones débiles, más frecuentes e intensas al final del día, cuando serán moderadas, sobre todo en los macizos occidentales. Cota de nieve en ascenso, de 1100-1200 a 1900-2100 metros. Temperaturas mínimas en descenso, localmente ligero, y máximas sin cambios o en ligero ascenso, más acusado en la divisoria. Heladas débiles o moderadas, que serán localmente fuertes y persistentes en cotas altas. Viento de componente oeste, moderado aumentando a fuerte, con rachas muy fuertes en cotas altas y zonas

AEMET. Se autoriza la reproducción de su contenido citando la fuente.

expuestas a últimas horas.

Datos en la atmósfera libre:

Altitud de la isoterma de 0 ºC: 2000 m
Altitud de la isoterma de -10 ºC: 3700 m

Viento a 1500 m: NW de 30 km/h a 40 km/h
Viento a 3000 m: NW 60 km/h

Evolución para el martes día 10

En aumento. En cotas medias y bajas se incrementará el peligro por nieve húmeda, mientras que en cotas altas se acentuarán los problemas de nieve reciente y placas de viento.

(Información elaborada a partir de los datos recibidos de los refugios de Linza, Lizara, Panticosa, Bachimaña, Góriz, Pineta, Estós, Angel Orús, La Renclusa y Cap de Llauset, de las estaciones de esquí de Astún, Formigal y Panticosa (lagos) y de la estación de esquí de fondo de Llanos del Hospital)

Escala europea de peligro de aludes

1 Débil | 2 Limitado | 3 Notable | 4 Fuerte | 5 Muy Fuerte

Problemas de aludes

Nieve reciente | Placas de viento | Capas débiles persistentes | Nieve húmeda | Deslizamientos basales | Sin problema evidente

Nota1: Se recuerda que, siempre que haya nieve, la ausencia total de peligro no existe. Hay que tener presente que en circunstancias desfavorables, con aludes de tamaño 1 (alud pequeño o colada) y tamaño 2 (alud mediano), se pueden sufrir severos daños personales.

Nota2: Los BPA se elaboran en base a información meteorológica así como al estado del manto nivoso a través de sondeos puntuales. Se advierte a los usuarios de la variabilidad de esta información al extrapolarla a zonas extensas de montaña. Por ello, AEMET no se hace responsable de su uso para la toma de decisiones que conciernen a la seguridad personal, ni de los riesgos físicos o materiales de ellas derivadas.

AEMET. Se autoriza la reproducción de su contenido citando la fuente.