Sonntag 08.02.2026

Aktualisiert am 08.02.2026 um 08:13

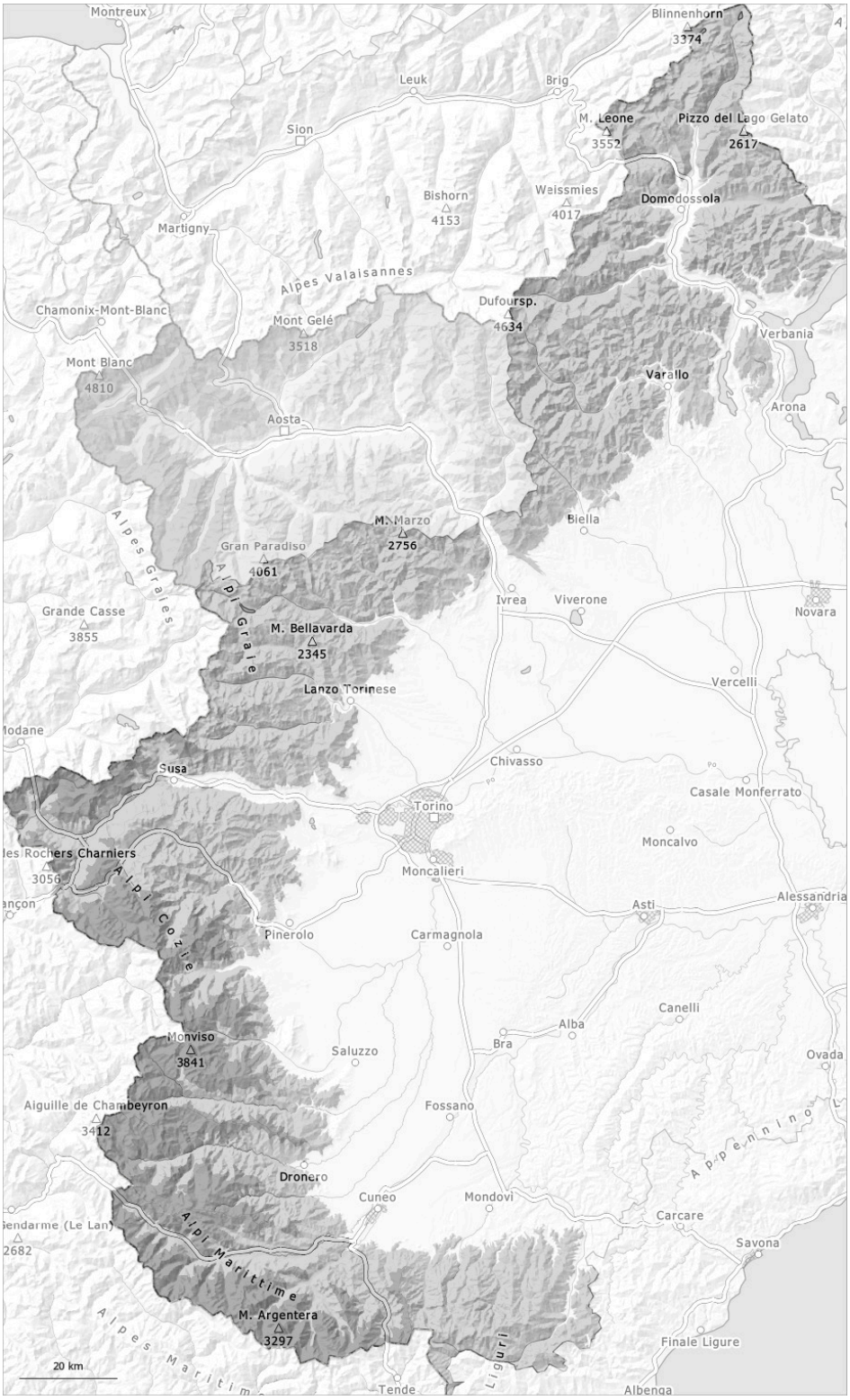

1	2	3	4	5
gering	mäßig	erheblich	groß	sehr groß

Gefahrenstufe 3 - Erheblich

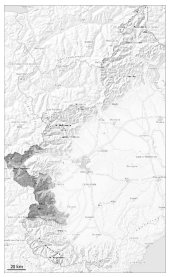

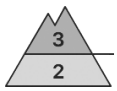

Waldgrenze

Tendenz: Lawinengefahr bleibt gleich
am Montag, den 09.02.2026

Triebschnee

Waldgrenze

Triebschnee

In mittleren und hohen Lagen weiterhin erhebliche Lawinengefahr.

Mit Neuschnee und mäßigem Wind entstanden meist dünne Triebschneeansammlungen.
Triebschneeansammlungen können schon von einzelnen Wintersportlern ausgelöst werden. Dies vor allem an steilen Hängen sowie in Rinnen, Mulden und hinter Geländekanten auch in mittleren Lagen.
Lawinen können v.a. an steilen Schattenhängen in tieferen Schichten ausgelöst werden.
Die Gefahrenstellen sind bei der schlechten Sicht kaum zu erkennen.

Eine überlegte Routenwahl ist nötig. Entlastungsabstände und Einzelabfahrten werden empfohlen.

Schneedecke

Gefahrenmuster gm.6: lockerer schnee und wind | gm.1: bodennahe schwachschicht

Mit Neuschnee und teils mäßigem Wind aus westlichen Richtungen entstanden vor allem oberhalb der Waldgrenze weitere Triebschneeansammlungen. Neu- und Triebschnee liegen an windgeschützten Schattenhängen auf weichen Schichten.

Mittlere und hohe Lagen: Im unteren Teil der Schneedecke sind vor allem an sehr steilen Schattenhängen vereinzelt störanfällige Schwachschichten vorhanden.

Tendenz

Ab dem Nachmittag fällt verbreitet Schnee oberhalb von rund 1000 m. Mit dem Neuschnee nehmen die Gefahrenstellen zu.

Gefahrenstufe 3 - Erheblich

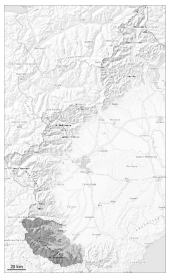

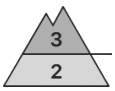

Waldgrenze

Tendenz: Lawinengefahr bleibt gleich
am Montag, den 09.02.2026

Triebschnee

Waldgrenze

Neuschnee

Mit Neuschnee und Wind verbreitet erhebliche Gefahr von trockenen Lawinen. Dies v.a. oberhalb der Waldgrenze.

Mit Neuschnee und mäßigem Wind entstanden weitere Triebschneeansammlungen. Der Neuschnee und insbesondere die teils großen Triebschneeansammlungen können an allen Expositionen und allgemein oberhalb der Waldgrenze von einzelnen Wintersportlern ausgelöst werden. Dies vor allem an steilen Hängen und in Kammlagen, Rinnen und Mulden.
Die Lawinen können in den verschiedenen Neu- und Triebschneeschichten anreißen und groß werden. Die Gefahrenstellen sind bei der schlechten Sicht kaum zu erkennen.

Eine vorsichtige Routenwahl und Entlastungsabstände werden empfohlen. Touren erfordern große Vorsicht und Zurückhaltung.

Schneedecke

Gefahrenmuster gm.6: lockerer schnee und wind

Mit Schneefall und mäßigem Westwind entstanden frische Triebschneeansammlungen. Neu- und Triebschnee liegen verbreitet auf weichen Schichten.

Oberhalb von rund 1500 m liegt viel Schnee.

Tendenz

Ab dem Nachmittag fällt verbreitet Schnee oberhalb von rund 800 m. Mit dem Neuschnee nehmen die Gefahrenstellen zu.

Gefahrenstufe 2 - Mäßig

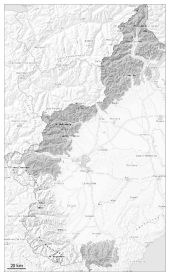

Tendenz: Lawinengefahr bleibt gleich
am Montag, den 09.02.2026

Triebschnee

Einzelne Gefahrenstellen liegen vor allem im Steilgelände in mittleren und hohen Lagen.

Die frischen und schon etwas älteren Triebschneeansammlungen bilden die Hauptgefahr. Die Gefahrenstellen liegen vor allem in Kamm- und Passlagen sowie an steilen, wenig befahrenen Hängen. In der Höhe sind diese Gefahrenstellen häufiger und die Gefahr höher.
Die Lawinen sind mittelgroß und meist mit großer Belastung auslösbar.
Sehr vereinzelt können Lawinen auch im Altschnee anbrechen und groß werden.

Die Gefahrenstellen sind bei der schlechten Sicht kaum zu erkennen. Entlastungsabstände und Einzelabfahrten werden empfohlen.

Schneedecke

Gefahrenmuster gm.6: lockerer schnee und wind | gm.1: bodennahe schwachschicht

Die Schneedecke ist verbreitet gut verfestigt. Beobachtungen im Gelände und Stabilitätstests zeigten diese Situation.
Die Gefahrenstellen liegen besonders an Triebschneehängen. Die Triebschneeansammlungen liegen vor allem an Schattenhängen auf weichen Schichten.

Mittlere und hohe Lagen: Im unteren Teil der Schneedecke sind vor allem an sehr steilen Schattenhängen keine ausgeprägten Schwachschichten vorhanden.

Tendenz

Ab dem Nachmittag fällt verbreitet Schnee oberhalb von rund 1200 m. Mit dem Neuschnee nehmen die Gefahrenstellen zu.