Dimanche 08.02.2026

Update du 08 02 2026, 08:13

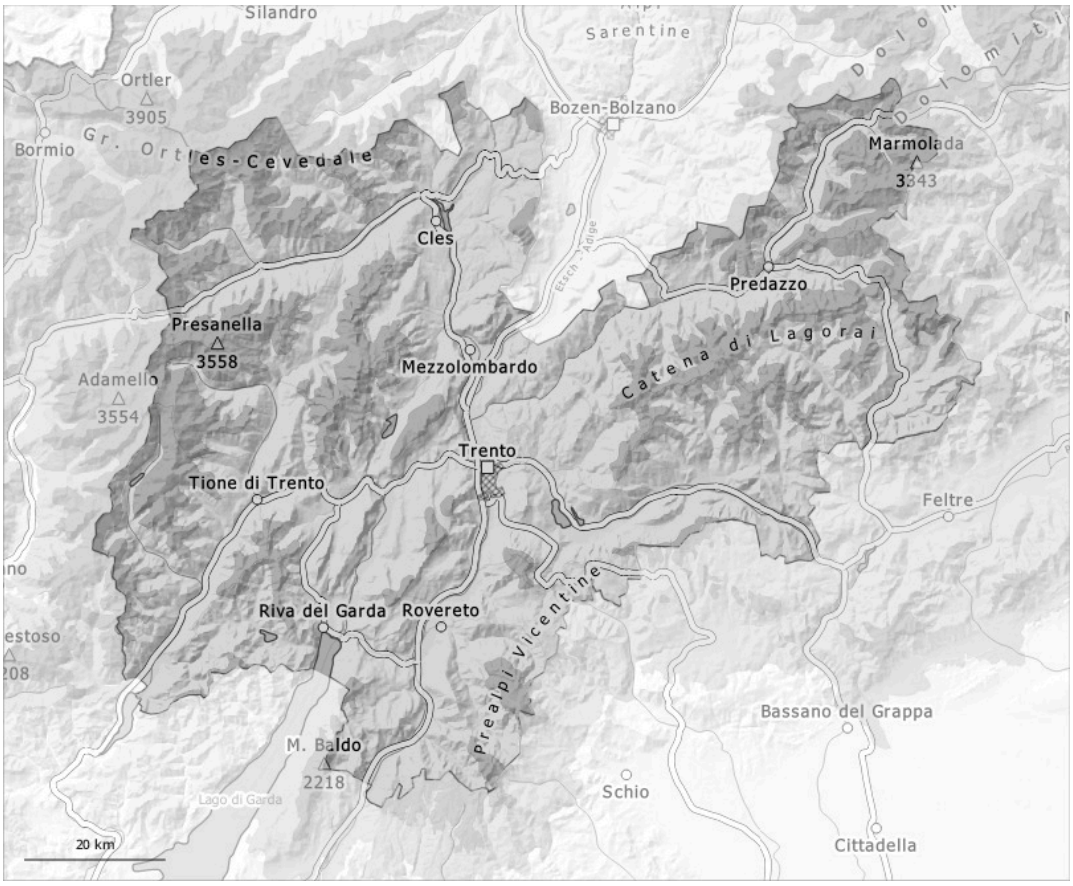

1	2	3	4	5
faible	limité	marqué	fort	très fort

Degré de danger 3 - Marqué

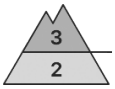

Limite de la forêt

Tendance: danger d'avalanche constant
leLundi 09 02 2026

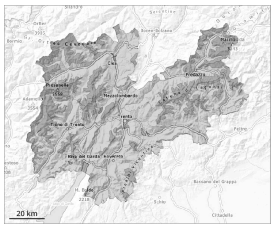

Neige ancienne (Sous-couche fragile persistante)

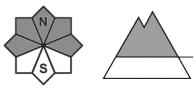

Limite de la forêt

Neige ancienne (Sous-couche fragile persistante)

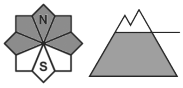

Limite de la forêt

Attention à la neige soufflée et neige ancienne fragile. Le danger d'avalanches se situe surtout au-dessus de la limite de la forêt dans la plage supérieure du degré de danger 3, "marqué".

La neige fraîche des derniers jours ainsi que les accumulations de neige soufflée reposent sur une surface de neige ancienne défavorable. Prudence surtout sur les pentes raides exposées à l'ouest, au nord et à l'est au-dessus de la limite de la forêt. Des couches fragiles marquées en partie inférieure du manteau neigeux peuvent déjà être déclenchées facilement par des amateurs de sports d'hiver isolés. Des avalanches peuvent entraîner le manteau jusqu'au sol et atteindre une grande taille. Des bruits sourds et des fissures lors du passage sur le manteau neigeux ainsi que des départs spontanés d'avalanches sont des signes d'alarme qui attirent l'attention sur le danger.
Les endroits dangereux sont fréquents et difficilement identifiables.
Des déclenchements à distance sont possibles.

Manteau neigeux

Modèles de danger md.1: sous-couche fragile persistante | md.8: givre de surface enneigé

La neige fraîche et la neige soufflée des derniers jours reposent sur une surface de neige ancienne défavorable.
Dans le manteau neigeux ancien des couches fragiles importantes sont présentes. Ceci particulièrement sur les pentes exposées à l'ouest, au nord et à l'est. Le manteau neigeux reste fragile.
Lundi: Il tombe localement au-dessus d'environ 1200 m jusqu'à 5 cm de neige. À basse altitude le manteau neigeux est humide.

Tendance

Le danger d'avalanches subsiste. Au-dessus de la limite de la forêt situation avalancheuse traître en général.