MINISTERO DELLA DIFESA

meteomont Servizio Nazionale di previsione neve e valanghe

EAWS EUROPEAN AVALANCHE WARNING SERVICES

CARABINIERI

In collaborazione con: arpav

DOLOMITI SETTENTRIONALI

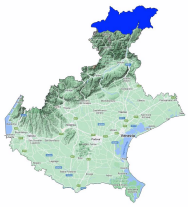

Bollettino Valanghe N. 338/2026 del 07/02/2026 ore 14.00
Validità 48 ore prossima emissione 08/02/2026

A cura del Servizio METEOMONT dell'ARMA dei CARABINIERI
In collaborazione con Servizio Meteorologico dell'Aeronautica militare

SITUAZIONE alle 14:00 del 07/02/2026

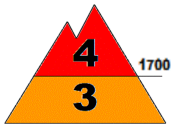

SITUAZIONE TIPO: neve a debole coesione e vento.



SITUAZIONE TIPO: situazione primaverile.

Quota neve (mslm)	Nord	Sud
	800 - 1300	900 - 1500

Altezza Neve (cm)	Neve al suolo	Neve Fresca	Quota (mslm)
	81	0	2119
	72	0	1530

VALANGHE OSSERVATE: Valanghe di piccole dimensioni, Valanghe a lastroni di superficie.

PREVISIONI 08/02/2026

GRADO DI PERICOLO: FORTE 4

SITUAZIONE TIPO: neve a debole coesione e vento.

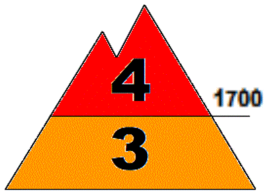



SITUAZIONE TIPO: situazione primaverile.

MANTO NEVOSO: La stabilità del manto nevoso è scarsa su molti punti (aree) per versanti settentrionali al di sopra di 1700 mslm, possibili valanghe di dimensioni grandi.
La stabilità del manto nevoso è scarsa su alcuni punti (aree) per tutte le esposizioni al di sotto di 1700 mslm, possibili valanghe di dimensioni medie.

AVVERTENZE

Viste le condizioni del manto nevoso, le attività al di fuori delle piste battute e segnalate richiedono ottime capacità di valutazione del pericolo locale.

SCALA EUROPEA DEL GRADO DI PERICOLO VALANGHE

LEGENDA PROBLEMA

Bollettino realizzato su scala sinottica-regionale (standard EAWS). La sua valutazione non può escludere in alcun modo la necessità di una seria e capace valutazione locale del pericolo (singolo pendio) che può essere anche sensibilmente diverso. Le previsioni meteorologiche sono relative all'orario UTC (per l'Italia +1 in inverno e +2 in estate).

MINISTERO DELLA DIFESA

meteomont
Servizio Nazionale di previsione neve e valanghe

EAWS EUROPEAN AVALANCHE WARNING SERVICES

CARABINIERI

In collaborazione con: arpav

DOLOMITI SETTENTRIONALI

PREVISIONE METEO

Quota		08/02/2026 h6:00	08/02/2026 h12:00	08/02/2026 h18:00
1000	Venti	01 Nodi da Nord	00 Calma	01 Nodi da Est
	Temperature	-03 °C	-02 °C	-02 °C
	Temp.percepita	-3 °C	-2 °C	-2 °C
2000	Venti	01 Nodi da Sud	01 Nodi da S-Ovest	01 Nodi da Est
	Temperature	-03 °C	-03 °C	-03 °C
	Temp.percepita	-3 °C	-3 °C	-3 °C
3000	Venti	01 nodi da Ovest	01 Nodi da Ovest	02 Nodi da Sud
	Temperature	-09 °C	-08 °C	-09 °C
	Temp.percepita	-9 °C	-8 °C	-9 °C
Zero termico		1000-1200 m.	1500-1700 m.	1400-1600 m.
Fenomeno		—	—	—
Stato del cielo				

LEGENDA FENOMENI

— Assenza Fenomeni · Nebbia · Foschia · Pioggia debole · Pioggia moderata · Pioggia forte · Temporali

Nevicata debole · Nevicata moderata · Nevicata forte

STATO DEL CIELO

Sereno · Poco nuvoloso · Nuvoloso · Molto nuvoloso · Coperto

Parametri meteonivometrici registrati presso i campi di rilevamento il 07/02/2026.

Località	Comune	Quota (m.s.l.m.)	Altezza neve (cm)	Neve caduta nelle 24 ore (cm)	Temp. Min (°C)	Temp. Max (°C)	Condizioni del tempo
MISURINA	Auronzo di Cadore (BL)	1759	64	0	-6	+5	Assenza di precipitazioni
MONTE AGUDO	Auronzo di Cadore (BL)	1530	72	0	-3	+2	Assenza di precipitazioni
MONTE FALORIA	Cortina d'Ampezzo (BL)	2119	81	0	-5	+6	Assenza di precipitazioni
COL DELLA TENDA	Comelico Superiore (BL)	1930	96	0	-4	+7	Assenza di precipitazioni
RIFUGIO VENEZIA *	Vodo Cadore (BL)	1999	81	1	N.P.	N.P.	Nevicata debole continua

(*) Rilievi fuori campo

L'INFORMAZIONE E' PREVENZIONE - LEGGI L'ATTUALE GRADO DI PERICOLO VALANGHE!

IL CAPO DEL CENTRO NAZIONALE METEOMONT
(Ten. Col. RFI Emanuela Gini)
FIRMA AUTOGRAFA OMESSA AI SENSI
DELL'ART.3 DEL D.LGS N.39/1993