MINISTERO DELLA DIFESA

meteomont Servizio Nazionale di previsione neve e valanghe

EAWS EUROPEAN AVALANCHE WARNING SERVICES

CARABINIERI

ALPI RETICHE

Bollettino Valanghe N. 341/2026 del 08/02/2026 ore 14.00
Validità 48 ore prossima emissione 09/02/2026

A cura del Servizio METEOMONT dell'ARMA dei CARABINIERI
In collaborazione con Servizio Meteorologico dell'Aeronautica militare

SITUAZIONE alle 14:00 del 08/02/2026

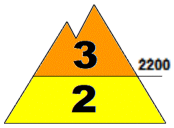

SITUAZIONE TIPO: brina di superficie sepolta.



SITUAZIONE TIPO: neve a debole coesione e vento.

Quota neve (mslm)	Nord	Sud
	900 - 1100	1100 - 1300

Altezza Neve (cm)	Neve al suolo	Neve Fresca	Quota (mslm)
	59	000	2582
	58	000	1640

VALANGHE OSSERVATE: Alcune valanghe di medie dimensioni, Valanghe di neve a debole coesione di fondo.

PREVISIONI 09/02/2026

GRADO DI PERICOLO: MARCATO 3

SITUAZIONE TIPO: brina di superficie sepolta.

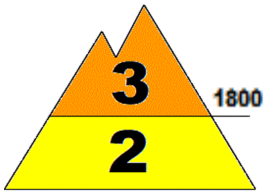

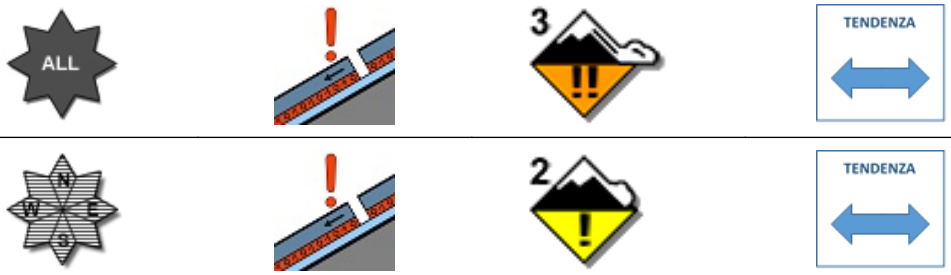

SITUAZIONE TIPO: passaggio da poca a molta neve.

MANTO NEVOSO: La stabilità del manto nevoso è scarsa su molti punti (aree) per tutte le esposizioni al di sopra di 1800 mslm, possibili valanghe di dimensioni medie.
La stabilità del manto nevoso è scarsa su alcuni punti (aree) per isolati pendii al di sotto di 1800 mslm, possibili valanghe di dimensioni medie.

AVVERTENZE

Viste le condizioni del manto nevoso, le attività al di fuori delle piste battute e segnalate richiedono ottime capacità di valutazione del pericolo locale.

SCALA EUROPEA DEL GRADO DI PERICOLO VALANGHE

5 - MOLTO FORTE | 4 - FORTE | 3 - MARCATO | 2 - MODERATO | 1 - DEBOLE | NO NEVE | NO INFO

LEGENDA PROBLEMA

NEVE FRESCA | LASTRONI DA VENTO | STRATI DEBOLI PERSISTENTI | NEVE BAGNATA | SLITTAMENTO | CORNICI | NESSUN PROBLEMA VALANGHIVO EVIDENTE | NO_INFO

Bollettino realizzato su scala sinottica-regionale (standard EAWS). La sua valutazione non può escludere in alcun modo la necessità di una seria e capace valutazione locale del pericolo (singolo pendio) che può essere anche sensibilmente diverso. Le previsioni meteorologiche sono relative all'orario UTC (per l'Italia +1 in inverno e +2 in estate).

MINISTERO DELLA DIFESA

meteomont
Servizio Nazionale di previsione neve e valanghe

EAWS EUROPEAN AVALANCHE WARNING SERVICES

CARABINIERI

ALPI RETICHE

PREVISIONE METEO

Quota		09/02/2026 h6:00	09/02/2026 h12:00	09/02/2026 h18:00
1000	Venti	00 Calma	00 Calma	01 Nodi da Nord
	Temperature	-03 °C	-04 °C	-04 °C
	Temp.percepita	-3 °C	-4 °C	-4 °C
2000	Venti	00 Calma	00 Calma	01 Nodi da Nord
	Temperature	-03 °C	-04 °C	-04 °C
	Temp.percepita	-3 °C	-4 °C	-4 °C
3000	Venti	01 Nodi da Sud	03 Nodi da S-Ovest	02 Nodi da S-Ovest
	Temperature	-10 °C	-10 °C	-10 °C
	Temp.percepita	-10 °C	-13 °C	-10 °C
Zero termico		0800-1000 m.	0900-1100 m.	1000-1200 m.
Fenomeno		—	—	
Stato del cielo				

LEGENDA FENOMENI

Assenza Fenomeni · Nebbia · Foschia · Pioggia debole · Pioggia moderata · Pioggia forte · Temporali

Nevicata debole · Nevicata moderata · Nevicata forte

STATO DEL CIELO

Sereno · Poco nuvoloso · Nuvoloso · Molto nuvoloso · Coperto

Parametri meteonivometrici registrati presso i campi di rilevamento il 08/02/2026.

Località	Comune	Quota (m.s.l.m.)	Altezza neve (cm)	Neve caduta nelle 24 ore (cm)	Temp. Min (°C)	Temp. Max (°C)	Condizioni del tempo
SPONDA	Livigno (SO)	2150	53	0	-13	+5	Assenza di precipitazioni
BORMIO2000-LECCIONA	Valdisotto (SO)	2050	57	0	-9	+5	Assenza di precipitazioni
VALAR	Valdidentro (SO)	1930	60	0	-12	+7	Assenza di precipitazioni
DOSSO DEL VALLONE	Valfurva (SO)	2582	59	0	-13	+1	Assenza di precipitazioni
COLONIA VIGILI	Ponte di Legno (BS)	1640	58	0	-6	+1	Assenza di precipitazioni
PISTA STELVIO *	Valdisotto (SO)	2220	63	0	N.P.	N.P.	Assenza di precipitazioni
MONTE CARDINE *	Madesimo (SO)	2165	142	0	N.P.	N.P.	Assenza di precipitazioni

(*) Rilievi fuori campo

L'INFORMAZIONE E' PREVENZIONE - LEGGI L'ATTUALE GRADO DI PERICOLO VALANGHE!

IL CAPO DEL CENTRO NAZIONALE METEOMONT
(Ten. Col. RFI Emanuela Gini)
FIRMA AUTOGRAFA OMESSA AI SENSI
DELL'ART.3 DEL D.LGS N.39/1993

Bollettino realizzato su scala sinottica-regionale (standard EAWS). La sua valutazione non può escludere in alcun modo la necessità di una seria e capace valutazione locale del pericolo (singolo pendio) che può essere anche sensibilmente diverso. Le previsioni meteorologiche sono relative all'orario UTC (per l'Italia +1 in inverno e +2 in estate).