MINISTERO DELLA DIFESA

meteomont
Servizio Nazionale di previsione neve e valanghe

EAWS EUROPEAN AVALANCHE WARNING SERVICES

CARABINIERI

APPENNINO EMILIANO CENTRALE

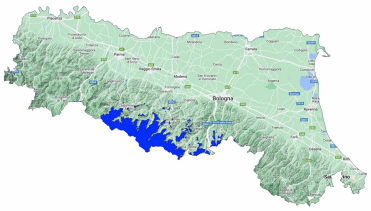

Bollettino Valanghe N. 312/2026 del 08/02/2026 ore 14.00
Validità 48 ore prossima emissione 09/02/2026
A cura del Servizio METEOMONT dell'ARMA dei CARABINIERI
In collaborazione con Servizio Meteorologico dell'Aeronautica militare

SITUAZIONE alle 14:00 del 08/02/2026

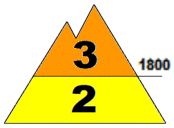

SITUAZIONE TIPO: neve a debole coesione e vento.

SITUAZIONE TIPO: situazione primaverile.

Quota neve (mslm)	Nord	Sud
	1200 - 1300	1300 - 1400

Altezza Neve (cm)	Neve al suolo	Neve Fresca	Quota (mslm)
	125	001	1840
	061	001	1550

VALANGHE OSSERVATE: Nessuna valanga.

PREVISIONI 09/02/2026

GRADO DI PERICOLO: MARCATO 3

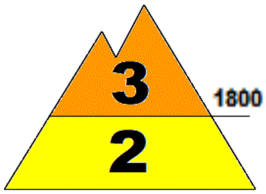

SITUAZIONE TIPO: neve a debole coesione e vento.

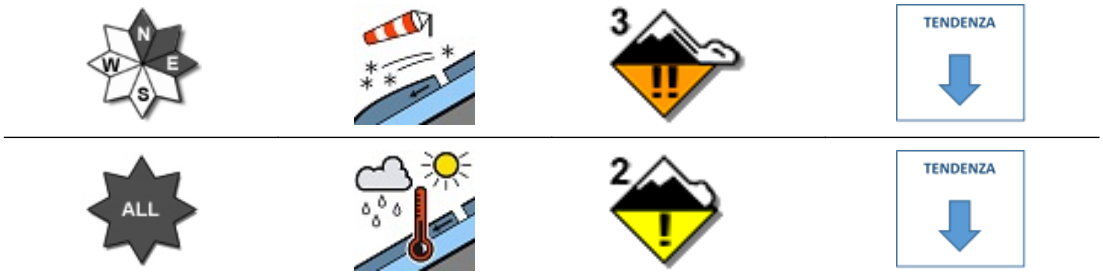

SITUAZIONE TIPO: situazione primaverile.

MANTO NEVOSO: La stabilità del manto nevoso è scarsa su molti punti (aree) per versanti nord orientali al di sopra di 1800 mslm, possibili valanghe di dimensioni medie.
La stabilità del manto nevoso è discreta su alcuni punti (aree) per tutte le esposizioni al di sotto di 1800 mslm, possibili valanghe di dimensioni medie.

AVVERTENZE

Viste le condizioni del manto nevoso, le attività al di fuori delle piste battute e segnalate richiedono ottime capacità di valutazione del pericolo locale.

SCALA EUROPEA DEL GRADO DI PERICOLO VALANGHE

LEGENDA PROBLEMA

Bollettino realizzato su scala sinottica-regionale (standard EAWS). La sua valutazione non può escludere in alcun modo la necessità di una seria e capace valutazione locale del pericolo (singolo pendio) che può essere anche sensibilmente diverso. Le previsioni meteorologiche sono relative all'orario UTC (per l'Italia +1 in inverno e +2 in estate).

MINISTERO DELLA DIFESA

meteomont
Servizio Nazionale di previsione neve e valanghe

EAWS EUROPEAN AVALANCHE WARNING SERVICES

CARABINIERI

APPENNINO EMILIANO CENTRALE

PREVISIONE METEO

Quota		09/02/2026 h6:00	09/02/2026 h12:00	09/02/2026 h18:00
1000	Venti	02 Nodi da N-Est	02 Nodi da N-Est	02 Nodi da Est
	Temperature	+01 °C	+01 °C	+01 °C
	Temp.percepita	1 °C	1 °C	1 °C
2000	Venti	09 Nodi da Est	07 Nodi da Est	06 Nodi da Est
	Temperature	-02 °C	-02 °C	-02 °C
	Temp.percepita	-7 °C	-6 °C	-6 °C
3000	Venti	07 Nodi da S-Est	03 Nodi da S-Est	00 Calma
	Temperature	-08 °C	-07 °C	-08 °C
	Temp.percepita	-14 °C	-10 °C	-8 °C
Zero termico		1400-1600 m.	1400-1600 m.	1400-1600 m.
Fenomeno				—
Stato del cielo				

LEGENDA FENOMENI

— Assenza Fenomeni · Nebbia · Foschia · Pioggia debole · Pioggia moderata · Pioggia forte · Temporali

Nevicata debole · Nevicata moderata · Nevicata forte

STATO DEL CIELO

Sereno · Poco nuvoloso · Nuvoloso · Molto nuvoloso · Coperto

Parametri meteonivometrici registrati presso i campi di rilevamento il 08/02/2026.

Località	Comune	Quota (m.s.l.m.)	Altezza neve (cm)	Neve caduta nelle 24 ore (cm)	Temp. Min (°C)	Temp. Max (°C)	Condizioni del tempo
RIFUGIO CAVONE	Lizzano in Belvedere (BO)	1416	50	0	+1	+1	Assenza di precipitazioni
LAGO DELLA NINFA	Sestola (MO)	1550	61	1	+1	+2	Assenza di precipitazioni
PIANCAVALLARO	Riolunato (MO)	1840	125	1	N.P.	N.P.	Assenza di precipitazioni
LE PRESE *	Villa Minozzo (RE)	1805	129	4	N.P.	N.P.	Assenza di precipitazioni

(*) Rilievi fuori campo

L'INFORMAZIONE E' PREVENZIONE - LEGGI L'ATTUALE GRADO DI PERICOLO VALANGHE!

IL CAPO DEL CENTRO NAZIONALE METEOMONT
(Ten. Col. RFI Emanuela Gini)
FIRMA AUTOGRAFA OMESSA AI SENSI
DELL'ART.3 DEL D.LGS N.39/1993

Bollettino realizzato su scala sinottica-regionale (standard EAWS). La sua valutazione non può escludere in alcun modo la necessità di una seria e capace valutazione locale del pericolo (singolo pendio) che può essere anche sensibilmente diverso. Le previsioni meteorologiche sono relative all'orario UTC (per l'Italia +1 in inverno e +2 in estate).