Bulletin d'estimation du risque d'avalanche
(valable en dehors des pistes balisées et ouvertes)

MASSIF : Chartreuse

Rédigé le dimanche 8 février 2026 à 15h

Estimation des risques pour le : LUNDI 09 FÉVRIER

POSSIBLES PETITES PLAQUES VERS LES HAUTES CRETES, EN PENTES OMBRAGEES...

2

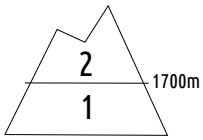

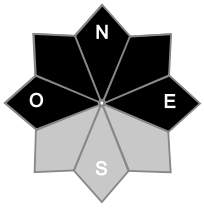

Hautes crêtes ?

Au-dessus de 1700m indice de risque limité, plus bas indice faible.

Départs spontanés : Rare coulée ponctuelle au soleil,. En pentes herbeuses, rare avalanche de glissement (de taille moyenne)

Déclenchements provoqués : Rares plaques instables en faces sommitales, ombragées...

Indices de risque : 5 très fort - 4 fort - 3 marqué - 2 limité - 1 faible -- En noir : les pentes les plus dangereuses

Stabilité du manteau neigeux

Situation avalancheuse typique : neige ventée

Vers les sommets vent de Sud modéré pouvant former quelques petites plaques en faces ombragées? En Sud et sous 1700m, neige croutée par regel, plus stable...

Déclenchements provoqués :
Lundi, quelques rafales de Sud pourraient former de petites plaques près des crêtes, en faces ombragées ? Noter qu'une rupture accidentelle de surface pourrait créer une cassure plus épaisse en contrebas, donnant une avalanche de moyenne taille.
Indices observables : Chasse neige temporaire, alternance zones dégarnies/accumulations...
En faces Sud et au Nord plus bas que 1700m le récent redoux a crouté la neige en surface, peu de risque accidentel mais ski parfois délicat...

Départs spontanés :
Peu d'activé attendue, ou de rares départs humides ponctuels lors d'éclaircies, près des rochers.
En pentes herbeuses raides (parfois fissurées), une rare avalanche de glissement, au terrain n'est pas exclue, notamment sous 1800m, d'ampleur moyenne (taille 2), et ce plutôt l'après-midi ou le soir.

Qualité de la neige

Qualification de l'enneigement : L'enneigement s'est récemment dégradé aux basses altitudes, sous les sapins mais reste correct pour la saison dès la moyenne montagne et dans les combes Nord.
Limites skiables : Vers 1100/1400 m, sur les pistes forestières/clairières...

Qualité de la neige lundi : Sous 1700/1800m et au Sud, neige croutée par regel , s'humidifiant lors de brèves éclaircies (ski parfois difficile en pentes peu tracées) . En faces Nord d'altitude reste un peu de neige poudreuse, reposant sur des sous couches plus ventées. Un peu de vent de Sud possible vers les sommets ?

Aperçu météo pour le lundi 09 février

	nuit	matin	après-midi	soir
Pluie-Neige				
Iso 0 °C	1700 m	1700 m	1700 m	1700 m
Vent 1500 m	5 km/h	10 km/h	20 km/h	25 km/h
Vent 2000 m	15 km/h	30 km/h	35 km/h	35 km/h

Regel lundi matin, éclaircies puis ciel davantage voilé voire nuageux l'après-midi. Un peu de vent de Sud vers les sommets...

Épaisseur de neige hors-piste

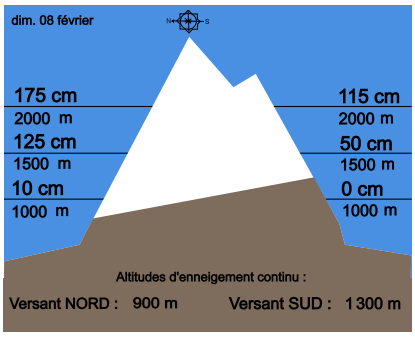

Précipitations à 1800 m

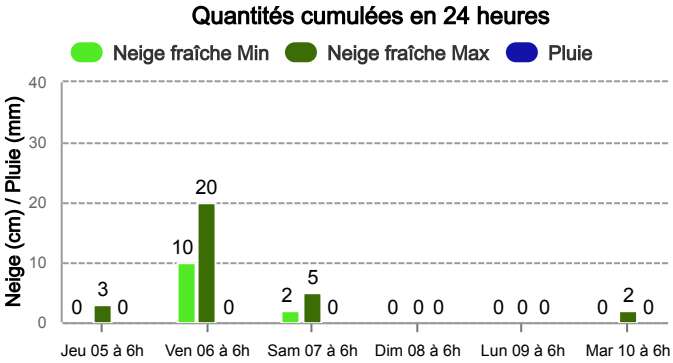

Tendance du mardi 10 février

3

Indice de risque marqué

Risque d'avalanche en hausse mardi.
Intempéries ; le matin vent et neige en moyenne montagne puis de la pluie mardi soir jusqu'en en haut de la Chartreuse.
D'abord formations de plaques puis de nombreuses avalanches (humides) spontanées probables mardi soir...

Pour consulter la vigilance en cours, veuillez vous rendre sur le site https://vigilance.meteofrance.fr/fr

Météo-France - 73 avenue de Paris, 94165 Saint-Mandé cedex - Contact : contact@meteo.fr

Rédigé par Météo-France avec la contribution des observateurs du réseau nivo-météorologiques. Partenariat : ANMSM (Maires de Stations de Montagne), DSF (Domaines Skiables de France), ADSP (Directeurs de Pistes et de la Sécurité des Stations de Sports d'Hiver) et autres acteurs de la montagne.

Bulletin neige & avalanches par téléphone au
0 892 68 10 20 Service 0,35 € / min + prix appel

Bulletin d'estimation du risque d'avalanche

(valable en dehors des pistes balisées et ouvertes)

MASSIF : Chartreuse

Rédigé le dimanche 8 février 2026 à 15h

Conditions nivo-météo des 7 derniers jours

	lun. 02/02				mar. 03/02				mer. 04/02				jeu. 05/02				ven. 06/02				sam. 07/02				dim. 08/02			
	03h	09h	15h	21h	03h	09h	15h	21h	03h	09h	15h	21h	03h	09h	15h	21h	03h	09h	15h	21h	03h	09h	15h	21h	03h	09h	15h	21h
Météo																												
Vent (km/h)	30	55	80	110	110	100	95	90	75	55	35	35	35	45	65	50	60	35	30	20	15	15	5	5	15	20	15	10
à 2000m																												
Vent (km/h)	15	35	60	90	90	80	75	70	55	40	25	20	20	20	40	25	30	20	15	10	10	5	10	10	10	5	5	5
à 1500m																												

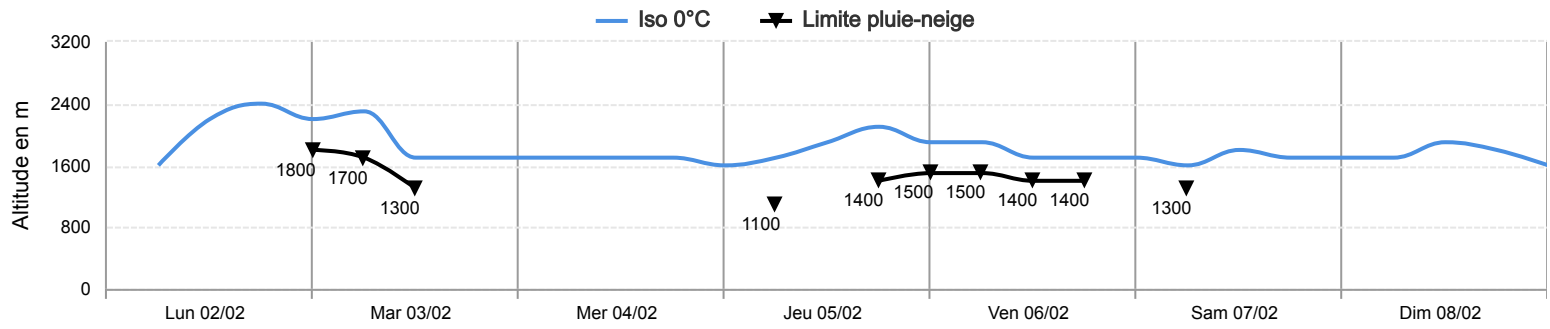

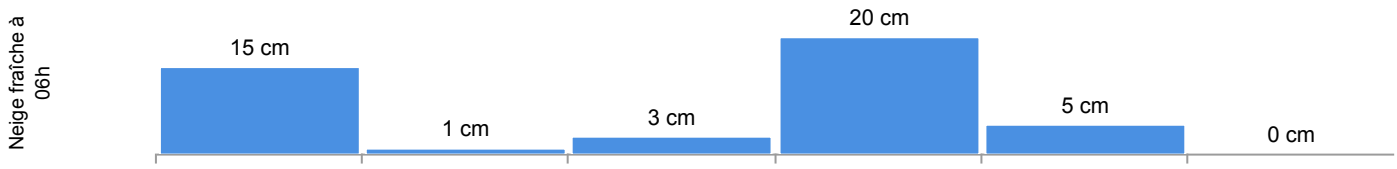

Risque d'avalanche	lun. 02/02	mar. 03/02	mer. 04/02	jeu. 05/02	ven. 06/02	sam. 07/02	dim. 08/02
	3	3	3	3	3	2	2

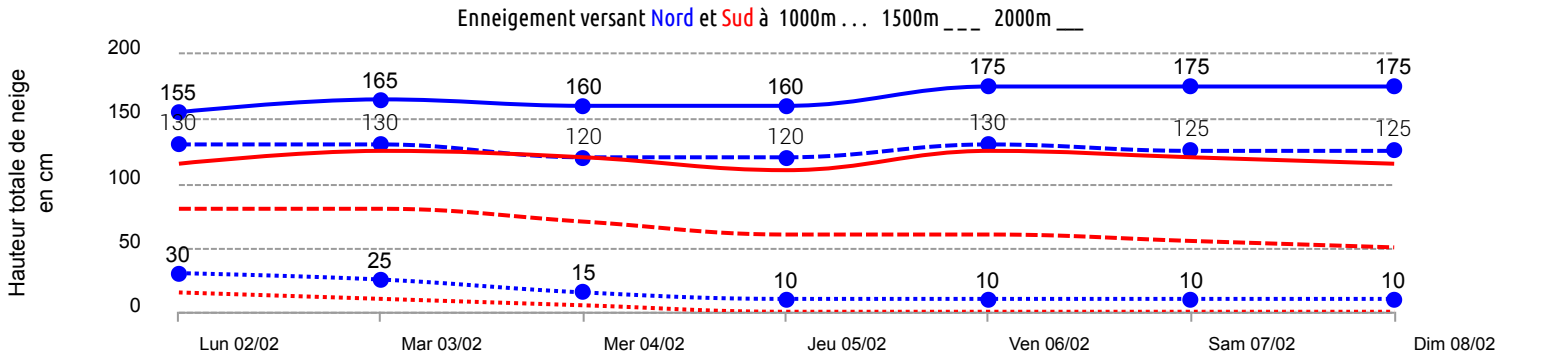

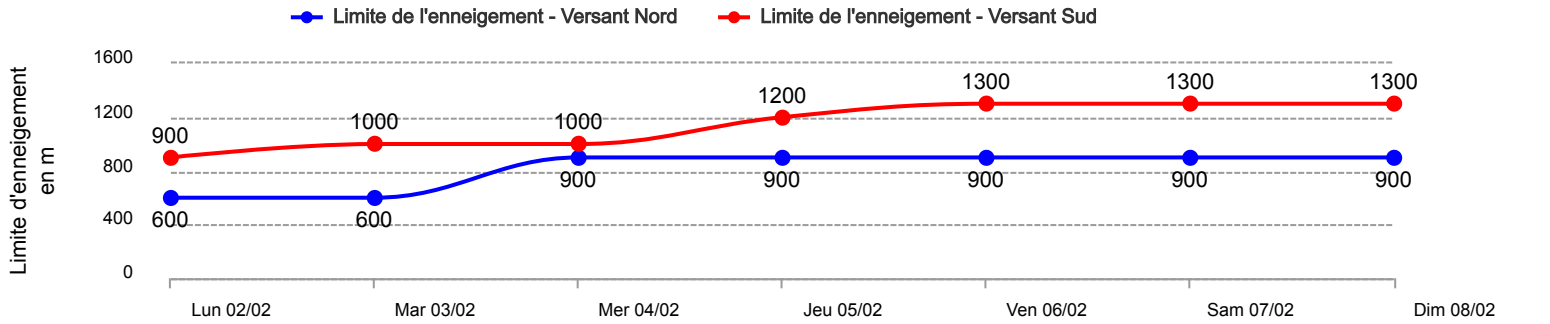

Pour consulter la vigilance en cours, veuillez vous rendre sur le site https://vigilance.meteofrance.fr/fr

Météo-France - 73 avenue de Paris, 94165 Saint-Mandé cedex - Contact : contact@meteo.fr

Bulletin neige & avalanches par téléphone au

0 892 68 10 20 Service 0,35 € / min + prix appel

Rédigé par Météo-France avec la contribution des observateurs du réseau nivo-météorologiques. Partenariat : ANMSM (Maires de Stations de Montagne), DSF (Domaines Skiables de France), ADSP (Directeurs de Pistes et de la Sécurité des Stations de Sports d'Hiver) et autres acteurs de la montagne.