Bulletin d'estimation du risque d'avalanche
(valable en dehors des pistes balisées et ouvertes)

MASSIF : Vercors

Rédigé le dimanche 8 février 2026 à 15h

Estimation des risques pour le : LUNDI 09 FÉVRIER

POSSIBLES PETITES PLAQUES VERS LES HAUTES CRETES, EN PENTES OMBRAGEES...

2

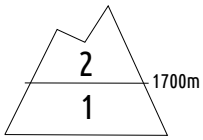

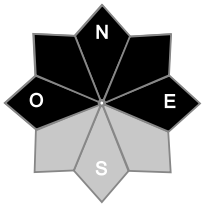

Hautes crêtes ?

Indices de risque : 5 très fort - 4 fort - 3 marqué - 2 limité - 1 faible -- En noir : les pentes les plus dangereuses

Au-dessus de 1700m indice de risque limité, plus bas indice faible.

Départs spontanés : Rare coulée ponctuelle au soleil. En pentes herbeuses, rare avalanche de glissement (de taille moyenne)

Déclenchements provoqués : Rares plaques instables en faces sommitales, ombragées...

Stabilité du manteau neigeux

Situation avalancheuse typique : neige ventée

Vers les sommets vent de Sud modéré pouvant former quelques petites plaques en faces ombragées? En Sud et sous 1700m, neige croutée par regel, plus stable...

Déclenchements provoqués :
Lundi, quelques rafales de Sud pourraient former de petites plaques près des hautes crêtes du Vercors, en faces ombragées, sorties de couloirs. Noter qu'une rupture accidentelle de surface pourrait créer une cassure plus épaisse en contrebas, donnant une avalanche de moyenne taille.
Indices observables : Chasse neige temporaire, alternance zones dégarnies/accumulations...
En faces Sud et au Nord plus bas que 1700m le récent redoux a crouté la neige en surface, peu de risque accidentel mais ski parfois délicat...

Départs spontanés :
Peu d'activé attendue, ou de rares départs humides ponctuels lors d'éclaircies, près des rochers.
En pentes herbeuses raides (parfois fissurées), une rare avalanche de glissement, au terrain n'est pas exclue, notamment sous 1800m, d'ampleur moyenne (taille 2), et ce plutôt l'après-midi ou le soir.

Qualité de la neige

Qualification de l'enneigement : L'enneigement s'est récemment dégradé aux basses altitudes, sous les sapins mais reste correct pour la saison dès la moyenne montagne et dans les combes Nord.
Limites skiables : Vers 1100/1400 m, sur les pistes forestières/clairières...

Qualité de la neige lundi : Sous 1700/1800m et au Sud, neige croutée par regel , s'humidifiant lors de brèves éclaircies (ski parfois difficile en pentes peu tracées) . En faces Nord d'altitude reste un peu de neige poudreuse, reposant sur des sous couches plus ventées. Un peu de vent de Sud possible vers les sommets ?

Aperçu météo pour le lundi 09 février

nuit	matin	après-midi	soir

Regel lundi matin, éclaircies puis ciel davantage voilé voire nuageux l'après-midi. Un peu de vent de Sud vers les sommets...

Pluie-Neige				
Iso 0 °C	1 700 m	1 700 m	1 700 m	1 700 m
Vent 1500 m	↙ 10 km/h	↑ 15 km/h	↑ 25 km/h	↑ 25 km/h
Vent 2000 m	↙ 10 km/h	↑ 25 km/h	↗ 25 km/h	↑ 25 km/h

Épaisseur de neige hors-piste

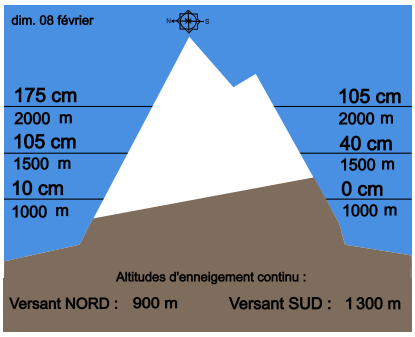

Précipitations à 1800 m

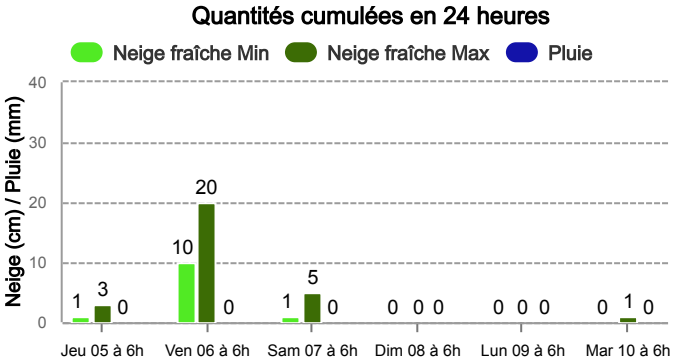

Tendance du mardi 10 février

3

Indice de risque marqué

Risque d'avalanche en hausse mardi.
Intempéries ; le matin vent et neige en moyenne montagne puis de la pluie mardi soir jusqu'en en haut du Vercors. D'abord formations de plaques puis de nombreuses avalanches (humides) spontanées probables mardi soir...

Pour consulter la vigilance en cours, veuillez vous rendre sur le site https://vigilance.meteofrance.fr/fr

Météo-France - 73 avenue de Paris, 94165 Saint-Mandé cedex - Contact : contact@meteo.fr

Rédigé par Météo-France avec la contribution des observateurs du réseau nivo-météorologiques. Partenariat : ANMSM (Maires de Stations de Montagne), DSF (Domaines Skiables de France), ADSP (Directeurs de Pistes et de la Sécurité des Stations de Sports d'Hiver) et autres acteurs de la montagne.

Bulletin neige & avalanches par téléphone au
0 892 68 10 20 Service 0,35 € / min + prix appel

RÉPUBLIQUE FRANÇAISE
Liberté Égalité Fraternité

METEO FRANCE
À VOS CÔTÉS, DANS UN CLIMAT QUI CHANGE

Bulletin d'estimation du risque d'avalanche

(valable en dehors des pistes balisées et ouvertes)

MASSIF : Vercors

Rédigé le dimanche 8 février 2026 à 15h

Conditions nivo-météo des 7 derniers jours

	lun. 02/02				mar. 03/02				mer. 04/02				jeu. 05/02				ven. 06/02				sam. 07/02				dim. 08/02			
	03h	09h	15h	21h	03h	09h	15h	21h	03h	09h	15h	21h	03h	09h	15h	21h	03h	09h	15h	21h	03h	09h	15h	21h	03h	09h	15h	21h
Météo																												
Vent (km/h)	25	55	80	120	125	90	75	70	45	50	50	30	25	35	50	45	55	25	25	15	15	15	15	10	25	20	25	20
à 2000m																												
Vent (km/h)	15	35	65	100	110	75	55	50	40	45	40	25	25	20	45	30	20	20	20	10	10	10	15	10	15	20	20	15
à 1500m																												

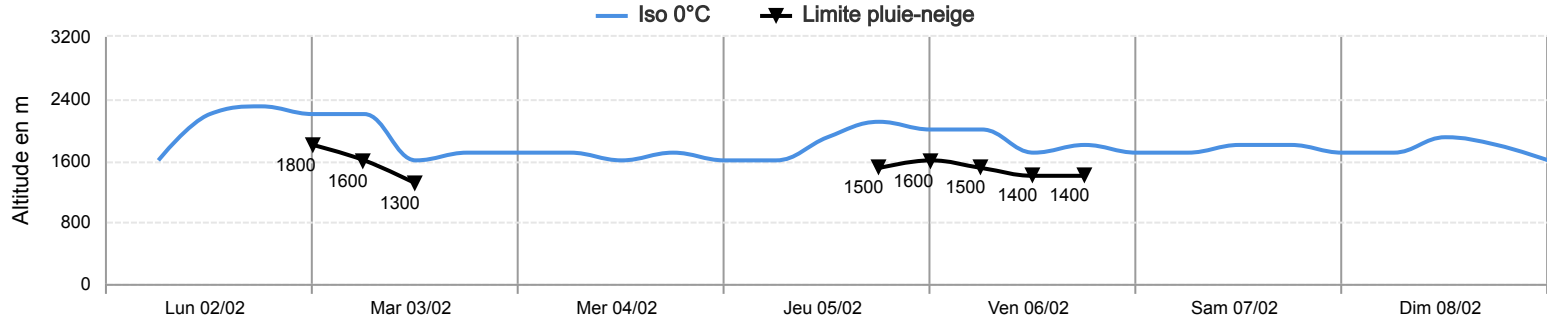

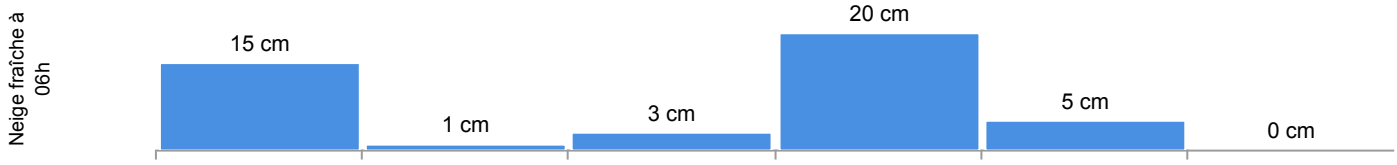

Risque d'avalanche	lun. 02/02	mar. 03/02	mer. 04/02	jeu. 05/02	ven. 06/02	sam. 07/02	dim. 08/02
	3	3	3	3	3	3	2

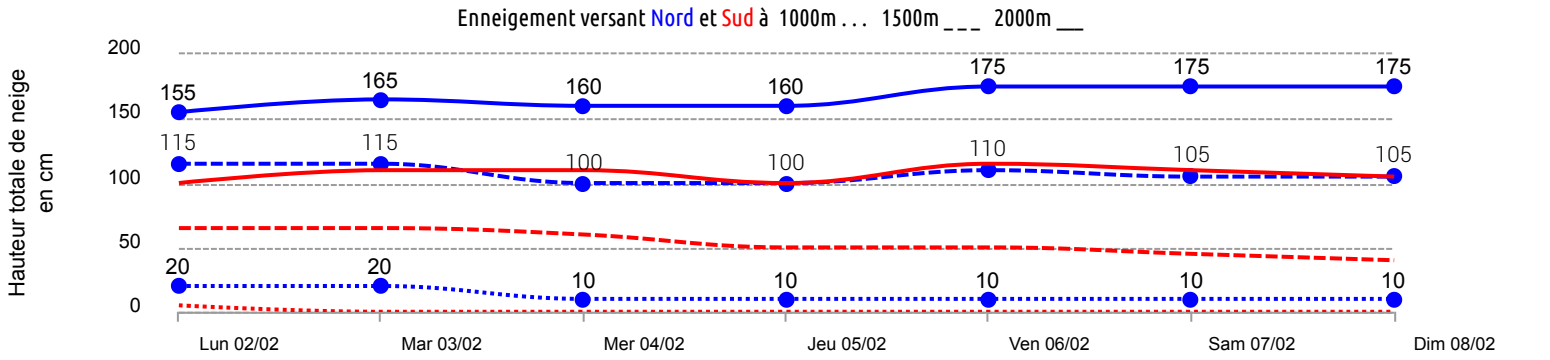

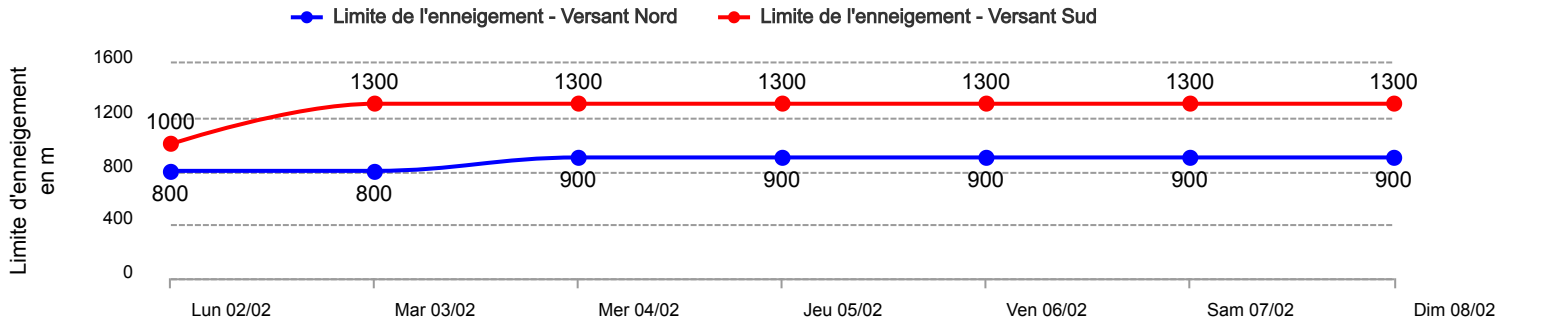

Pour consulter la vigilance en cours, veuillez vous rendre sur le site https://vigilance.meteofrance.fr/fr

Météo-France - 73 avenue de Paris, 94165 Saint-Mandé cedex - Contact : contact@meteo.fr

Rédigé par Météo-France avec la contribution des observateurs du réseau nivo-météorologiques. Partenariat : ANMSM (Maires de Stations de Montagne), DSF (Domaines Skiables de France), ADSP (Directeurs de Pistes et de la Sécurité des Stations de Sports d'Hiver) et autres acteurs de la montagne.

Bulletin neige & avalanches par téléphone au
0 892 68 10 20 Service 0,35 € / min + prix appel