Bulletin d'estimation du risque d'avalanche
(valable en dehors des pistes balisées et ouvertes)

MASSIF : Bauges

Rédigé le dimanche 8 février 2026 à 16h

Estimation des risques pour le : LUNDI 09 FÉVRIER

2

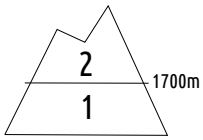

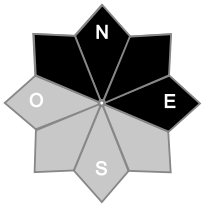

Au-dessus de 1700m indice de risque limité, plus bas indice faible.

Départs spontanés : Petits départs au fil de l'ensoleillement.

Déclenchements provoqués : Plaques friables dans la neige récente.

Indices de risque : 5 très fort - 4 fort - 3 marqué - 2 limité - 1 faible -- En noir : les pentes les plus dangereuses

Stabilité du manteau neigeux

Situation avalancheuse typique : neige ventée

Déclenchements provoqués :
Au-dessus de 1700 m dans les versants Nord à Est : rares **plaques friables dans la neige récente**. Formées par le **vent de secteur Sud à Ouest**. Cassure de 10-30 cm d'épaisseur. Taille 1 (petite), rarement 2 (moyenne).
Observables : irrégularités d'épaisseur du manteau neigeux, zones d'accumulation, fissures devant les skis ...

Départs spontanés :
* Rares plaques de fond. Départs possibles à toute heure du jour et de la nuit. Départs plus probables dans les faces exposées au soleil, dans les pentes raides et lisses (pentes herbeuses, dalles rocheuses). Taille 1 (petite) à 2 (moyenne).
* Petits départs ponctuels dans les pentes raides. Principalement près des rochers/falaises et au fil de l'ensoleillement.

Qualité de la neige

Enneigement : déficitaire à correct pour la saison. On peut chausser les skis ou raquettes vers 1100/1200 m environ. Peu de sous-couche sous 1500 m. Cailloux vers les crêtes peu enneigées.

Qualité de la neige ce lundi :
* En dessous de 1400 m : neige dure regelée le matin, qui décaille légèrement en surface dans la journée.
* En-dessous de 1700m en versants Nord et dans les versants Sud : le matin, une petite croûte de regel non portante est présente en surface. Au fil de la journée, la neige se ramollit légèrement en surface, surtout dans les versants ensoleillés.
* Au-dessus de 1700m en versants N : couche de neige récente restée froide et assez légère qui repose sur un fond dur, travaillé par le vent.

Aperçu météo pour le lundi 09 février

nuit	matin	après-midi	soir

Soleil dominant avec un voile nuageux en altitude. Le ciel se couvre en fin de journée. Le vent de Sud-Ouest à Ouest se renforce.

Pluie-Neige				
Iso 0 °C	1 700 m	1 600 m	1 600 m	1 600 m
Vent 1500 m	5 km/h	10 km/h	15 km/h	25 km/h
Vent 2000 m	10 km/h	15 km/h	25 km/h	35 km/h

Épaisseur de neige hors-piste

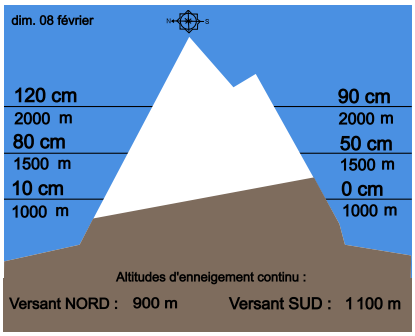

Précipitations à 1800 m

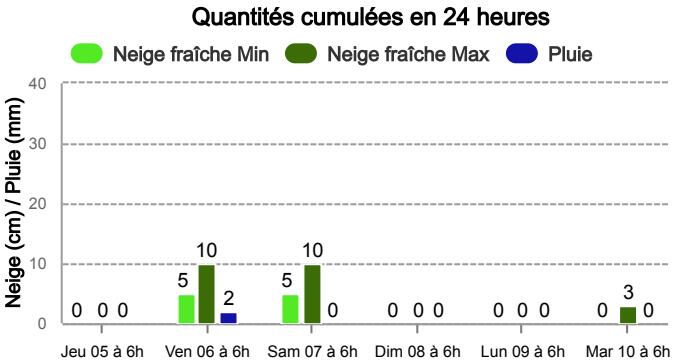

Tendance du mardi 10 février

2

Indice de risque limité

Petites chutes de neige/pluie dans la journée de mardi (limite pluie-neige vers 1200 m remontant jusqu'à 1800 m). Le vent de Sud-Ouest se renforce. Des nouvelles petites plaques friables se forment dans la neige meuble en surface et de la neige humide coule avec la pluie.

Pour consulter la vigilance en cours, veuillez vous rendre sur le site https://vigilance.meteofrance.fr/fr

Météo-France - 73 avenue de Paris, 94165 Saint-Mandé cedex - Contact : contact@meteo.fr

Rédigé par Météo-France avec la contribution des observateurs du réseau nivo-météorologiques. Partenariat : ANMSM (Maires de Stations de Montagne), DSF (Domaines Skiables de France), ADSP (Directeurs de Pistes et de la Sécurité des Stations de Sports d'Hiver) et autres acteurs de la montagne.

Bulletin neige & avalanches par téléphone au
0 892 68 10 20 Service 0,35 € / min + prix appel

RÉPUBLIQUE FRANÇAISE
Liberté Égalité Fraternité

METEO FRANCE
À VOS CÔTÉS, DANS UN CLIMAT QUI CHANGE

Bulletin d'estimation du risque d'avalanche

(valable en dehors des pistes balisées et ouvertes)

MASSIF : Bauges

Rédigé le dimanche 8 février 2026 à 16h

Conditions nivo-météo des 7 derniers jours

	lun. 02/02				mar. 03/02				mer. 04/02				jeu. 05/02				ven. 06/02				sam. 07/02				dim. 08/02			
	03h	09h	15h	21h	03h	09h	15h	21h	03h	09h	15h	21h	03h	09h	15h	21h	03h	09h	15h	21h	03h	09h	15h	21h	03h	09h	15h	21h
Météo																												
Vent (km/h)	30	40	50	55	55	45	35	30	20	20	25	35	30	30	30	25	30	30	25	20	20	10	10	10	10	10	15	10
à 2000m																												
Vent (km/h)	20	25	30	30	40	35	25	20	10	10	15	25	20	20	20	20	25	25	20	10	10	5	5	5	5	5	10	5
à 1500m																												

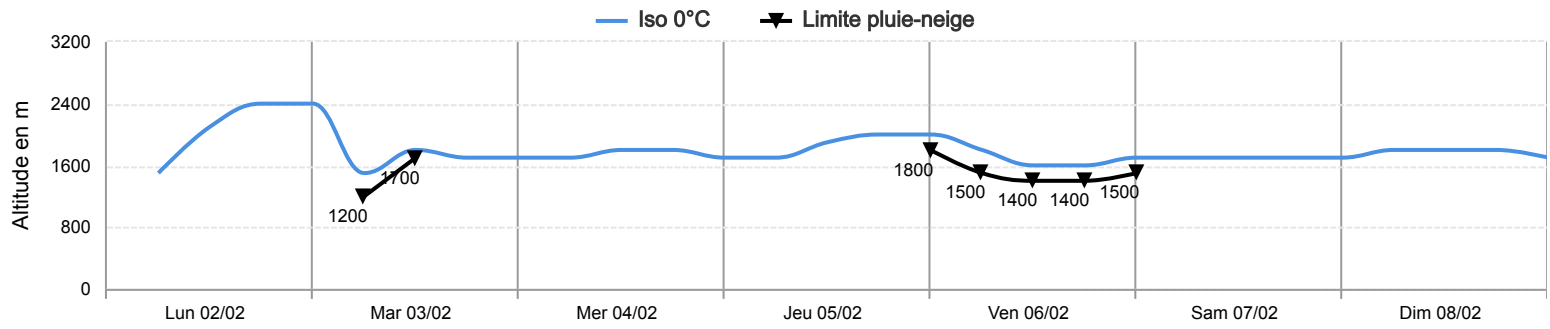

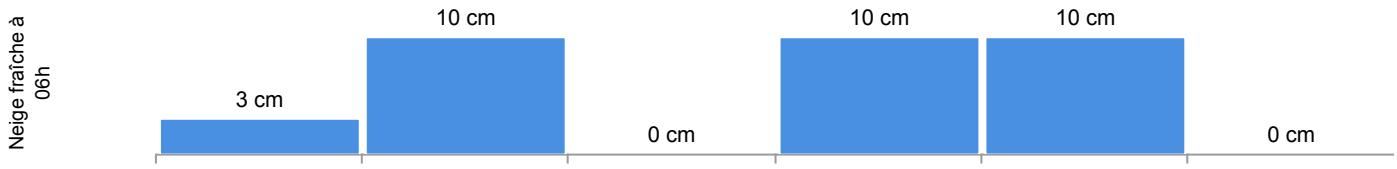

Risque d'avalanche	lun. 02/02	mar. 03/02	mer. 04/02	jeu. 05/02	ven. 06/02	sam. 07/02	dim. 08/02
	2	3	3	3	3	2	2

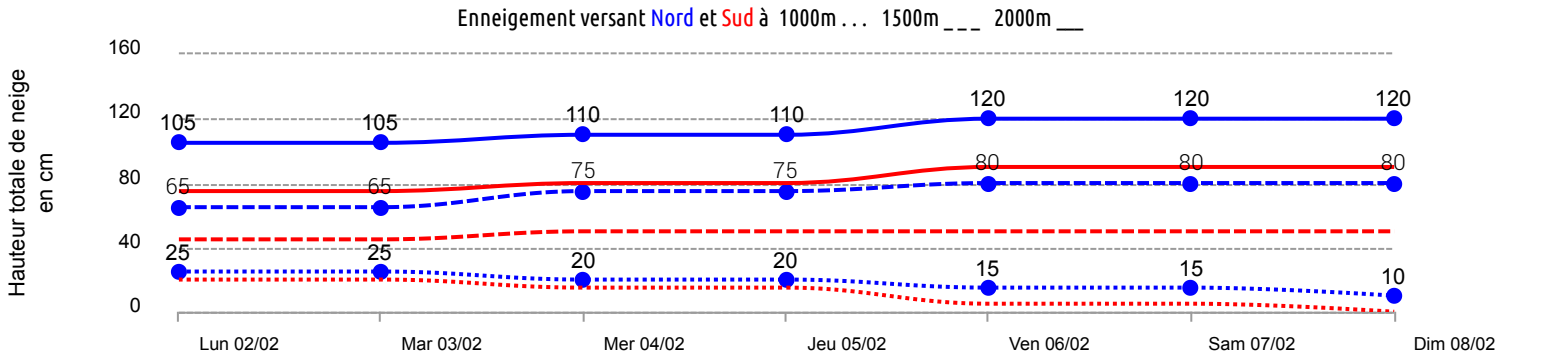

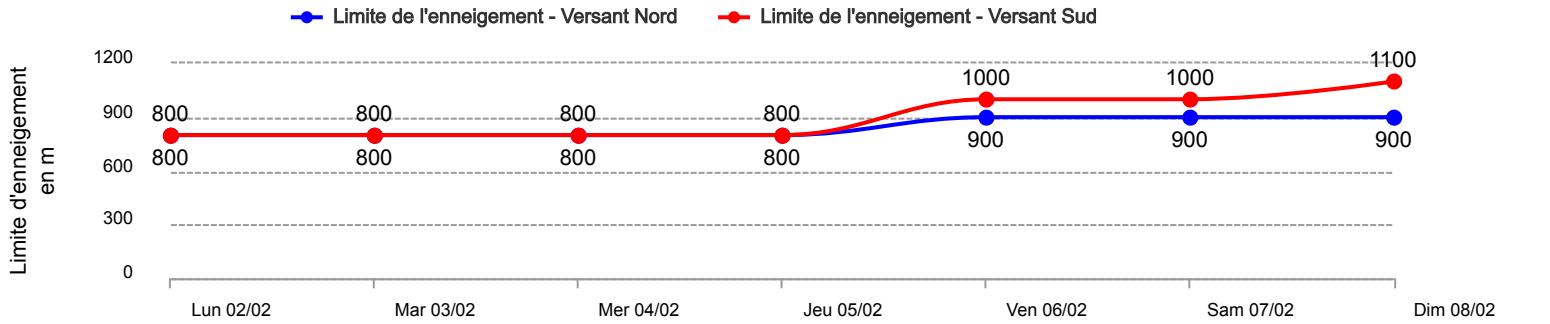

Pour consulter la vigilance en cours, veuillez vous rendre sur le site https://vigilance.meteofrance.fr/fr

Météo-France - 73 avenue de Paris, 94165 Saint-Mandé cedex - Contact : contact@meteo.fr

Rédigé par Météo-France avec la contribution des observateurs du réseau nivo-météorologiques. Partenariat : ANMSM (Maires de Stations de Montagne), DSF (Domaines Skiables de France), ADSP (Directeurs de Pistes et de la Sécurité des Stations de Sports d'Hiver) et autres acteurs de la montagne.

Bulletin neige & avalanches par téléphone au
0 892 68 10 20 Service 0,35 € / min + prix appel