Bulletin d'estimation du risque d'avalanche

(valable en dehors des pistes balisées et ouvertes)

MASSIF : Chablais

Rédigé le dimanche 8 février 2026 à 16h

Estimation des risques pour le : LUNDI 09 FÉVRIER

2

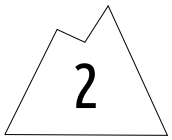

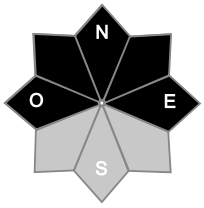

Indice de risque limité.

Départs spontanés : Petits départs au fil de l'ensoleillement.

Déclenchements provoqués : Couche fragile persistante enfouie.

Indices de risque : 5 très fort - 4 fort - 3 marqué - 2 limité - 1 faible -- En noir : les pentes les plus dangereuses

Stabilité du manteau neigeux

Situation avalancheuse typique : couche fragile persistante neige ventée

Déclenchements provoqués :

* **Au-dessus de 2000 m en versants E/N/W** : Présence d'une **couche fragile persistante** enfouie. Difficilement déclenchable par un· skieur·euse. Risque d'avalanches en cascade (par exemple, déclenchement par la rupture d'une plaque à vent). **Cassure épaisse** (50-80 cm) et **large**. Taille 2 (moyenne), rarement 3 (grande).
Observables : peu d'observables directs, réalisation de tests CT et ECT.
* Au-dessus de 2200 m : **rares plaques friables dans la neige récente**. Formées par le **vent de secteur Sud à Ouest**. Cassure de 15-30 cm d'épaisseur. Taille 1 (petite), rarement 2 (moyenne).
Observables : irrégularités d'épaisseur du manteau neigeux, zones d'accumulation, fissures devant les skis ...

Départs spontanés :

* Petits départs ponctuels dans les pentes raides. Principalement près des rochers/falaises et au fil de l'ensoleillement.
* Rares plaques de fond. Départs possibles à toute heure du jour et de la nuit. Départs plus probables dans les faces exposées au soleil, dans les pentes raides et lisses (pentes herbeuses, dalles rocheuses). Taille 1 (petite) à 2 (moyenne).

Autre :
Risque de cassure de corniches.

Qualité de la neige

Enneigement : correct pour la saison, sauf vers les crêtes soufflées. On peut chausser les skis vers 1100/1300 m. Pas de sous-couche sous 1400/1500 m, gare aux cailloux masqués.

Qualité de la neige ce lundi :

* En dessous de 1400 m : neige dure regelée le matin, qui décaille légèrement en surface dans la journée.
* En-dessous de 1700m en versants Nord et 2200m en versants Sud : le matin, une petite croûte de regel non portante est présente en surface. Au fil de la journée, la neige se ramollit légèrement en surface, surtout dans les versants ensoleillés.
* Au-dessus : couche de neige récente restée froide et assez légère (20-30 cm). Elle repose soit sur de la neige restée meuble (l'enfoncement piéton est alors important), soit sur une surface durcie par le travail du vent de Sud à Ouest.

Aperçu météo pour le lundi 09 février

	nuit	matin	après-midi	soir
	Soleil dominant avec un voile nuageux en altitude. Le ciel se couvre en fin de journée. Le vent de Sud-Ouest à Ouest se renforce.			
Pluie-Neige				
Iso 0 °C	1 800 m	1 700 m	1 800 m	1 700 m
Vent 2000 m	5 km/h	10 km/h	20 km/h	30 km/h
Vent 2500 m	5 km/h	15 km/h	30 km/h	40 km/h

Épaisseur de neige hors-piste

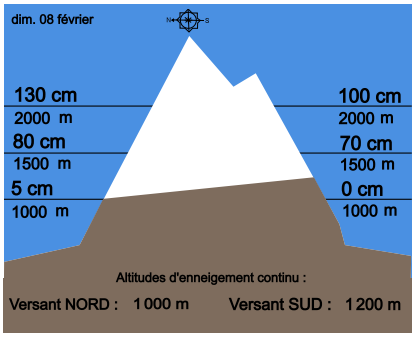

Précipitations à 1800 m

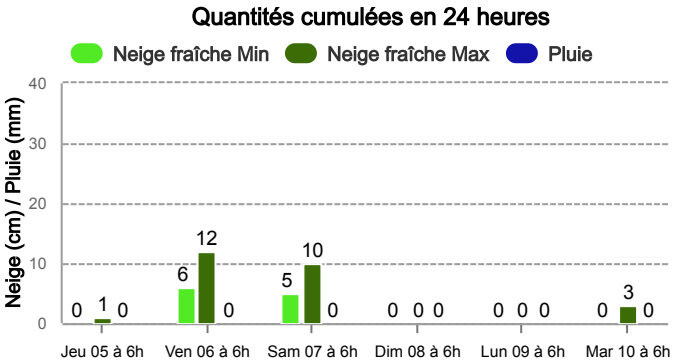

Tendance du mardi 10 février

2

Indice de risque limité

Petites chutes de neige en altitude dans la journée de mardi (limite pluie-neige vers 1200 m remontant jusqu'à 1800 m). Le vent de Sud-Ouest se renforce. Des nouvelles plaques friables se forment dans la neige meuble en surface.

Pour consulter la vigilance en cours, veuillez vous rendre sur le site https://vigilance.meteofrance.fr/fr

Météo-France - 73 avenue de Paris, 94165 Saint-Mandé cedex - Contact : contact@meteo.fr

Rédigé par Météo-France avec la contribution des observateurs du réseau nivo-météorologiques. Partenariat : ANMSM (Maires de Stations de Montagne), DSF (Domaines Skiables de France), ADSP (Directeurs de Pistes et de la Sécurité des Stations de Sports d'Hiver) et autres acteurs de la montagne.

Bulletin neige & avalanches par téléphone au

0 892 68 10 20 Service 0,35 € / min + prix appel

RÉPUBLIQUE FRANÇAISE
Liberté Égalité Fraternité

METEO FRANCE
À VOS CÔTÉS, DANS UN CLIMAT QUI CHANGE

Bulletin d'estimation du risque d'avalanche

(valable en dehors des pistes balisées et ouvertes)

MASSIF : Chablais

Rédigé le dimanche 8 février 2026 à 16h

Conditions nivo-météo des 7 derniers jours

	lun. 02/02				mar. 03/02				mer. 04/02				jeu. 05/02				ven. 06/02				sam. 07/02				dim. 08/02			
	03h	09h	15h	21h	03h	09h	15h	21h	03h	09h	15h	21h	03h	09h	15h	21h	03h	09h	15h	21h	03h	09h	15h	21h	03h	09h	15h	21h
Météo																												
Vent (km/h)	45	50	55	55	55	70	50	40	20	15	10	20	30	35	45	40	50	40	40	30	20	10	10	10	10	10	15	5
à 2500m																												
Vent (km/h)	30	40	35	35	40	55	35	35	10	5	5	15	25	30	30	30	30	30	30	20	10	5	5	5	5	5	10	5
à 2000m																												

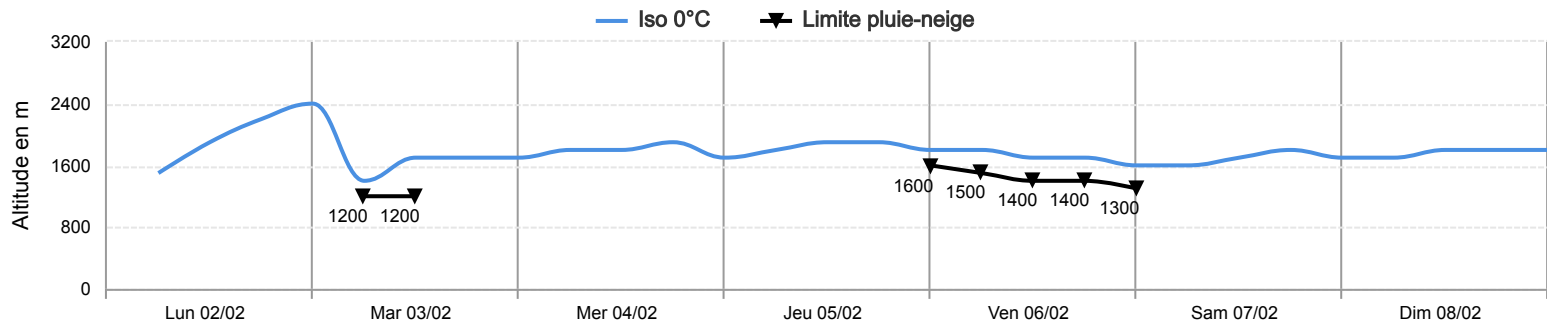



Risque d'avalanche	lun. 02/02	mar. 03/02	mer. 04/02	jeu. 05/02	ven. 06/02	sam. 07/02	dim. 08/02
	3	3	3	3	3	3	2

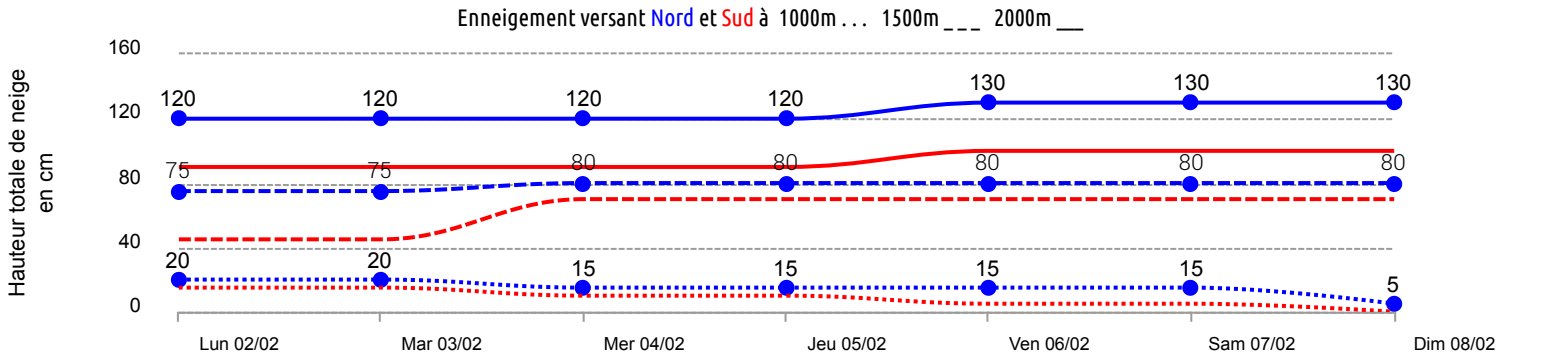

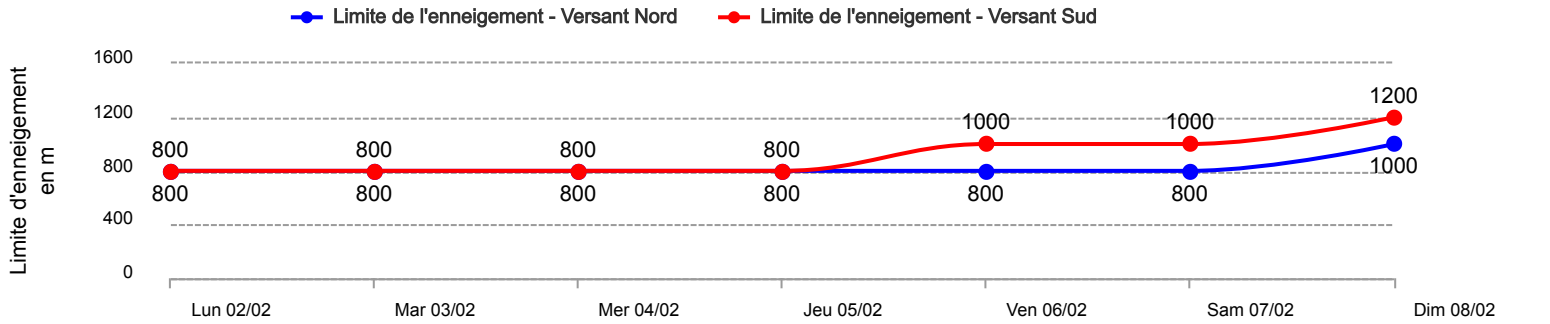

Pour consulter la vigilance en cours, veuillez vous rendre sur le site https://vigilance.meteofrance.fr/fr

Météo-France - 73 avenue de Paris, 94165 Saint-Mandé cedex - Contact : contact@meteo.fr

Rédigé par Météo-France avec la contribution des observateurs du réseau nivo-météorologiques. Partenariat : ANMSM (Maires de Stations de Montagne), DSF (Domaines Skiables de France), ADSP (Directeurs de Pistes et de la Sécurité des Stations de Sports d'Hiver) et autres acteurs de la montagne.

Bulletin neige & avalanches par téléphone au
0 892 68 10 20 Service 0,35 € / min + prix appel