Bulletin d'estimation du risque d'avalanche

(valable en dehors des pistes balisées et ouvertes)

MASSIF : Renoso Incudine

Rédigé le dimanche 8 février 2026 à 16h

Estimation des risques pour le : LUNDI 09 FÉVRIER

RISQUE RESTANT MARQUÉ EN ALTITUDE.

3

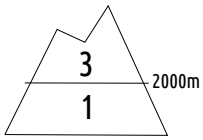

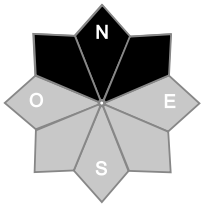

Au-dessus de 2000m indice de risque marqué, plus bas indice faible.

Départs spontanés : peu probables ou superficiel en neige récente.

Déclenchements provoqués : Plaques en altitude

Indices de risque : 5 très fort - 4 fort - 3 marqué - 2 limité - 1 faible -- En noir : les pentes les plus dangereuses

Stabilité du manteau neigeux

Situation avalancheuse typique : neige ventée couche fragile persistante

Déclenchements provoqués : Plaques en place parfois loin des crêtes formées par les épisodes successifs de vent fort d'ouest à sud-ouest. Plaques dures juste sous les crêtes balayées par le vent, friables en altitude dans les zones de redépose un peu plus abrités. Elles se stabilisent peu à peu par tassement mais restent encore facilement déclenchables au-dessus de 2000m et peuvent générer des avalanches de taille moyenne(taille 2). Dans les secteurs froids bien ombragés au-dessus de 2000m, une avalanche de grande taille (taille 3) reste non exclue, par sollicitation de couches fragiles persistantes dans le manteau neigeux. Elles sont difficilement déclenchables car maintenant enfouies assez profondément. Leur sollicitation est parfois possible là où l'épaisseur de neige est moins importante (abords des combes, ruptures de pente....).
En dessous de 2000 m, les pluies des jours précédents et le tassement ont contribué à stabiliser le manteau. Les plaques formées par la suite sont généralement peu épaisses.
Départs spontanés : Quelques coulée voire avalanches de neige récente de taille petites à moyenne sont attendues à la faveur des éclaircies.

Qualité de la neige

Qualification de l'enneigement : l'enneigement est excellent pour la saison à toutes altitudes, avec des cumuls de neige récente atteignant ponctuellement 40 à 60 cm en moyenne montagne. On relève plus de 2 mètres dans les combes abritées.
Limite d'enneigement skiable : 1400 à 1500 m.
État de la neige : Le manteau neigeux a connu un cycle degel/regel sous 1800m voire plus haut en versants sud. La neige est souvent dure et portante en dessous de 2000 m environ. Au dessus de 2000m en secteurs ombragés ou à soleil plus rasant, La neige reste sèche, légère et profonde à l'abri du vent d'ouest abrités et de la neige très changeante (dure, carton, regelée) dans les secteurs ventés. Au dessus de 1600m on peut trouver une dizaine de cm de neige fraîche. Corniches et accumulations parfois volumineuses en place.

Aperçu météo pour le lundi 09 février

	nuit	matin	après-midi	soir
Pluie-Neige	1 500 m	1 500 m	1 600 m	
Iso 0 °C	1 800 m	1 900 m	1 900 m	1 900 m
Vent 1500 m	↗ 15 km/h	↘ 15 km/h	→ 15 km/h	→ 10 km/h
Vent 2000 m	↑ 10 km/h	→ 10 km/h	→ 10 km/h	↘ 10 km/h

Épaisseur de neige hors-piste

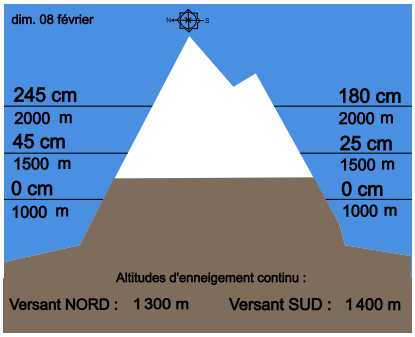

Précipitations à 1800 m

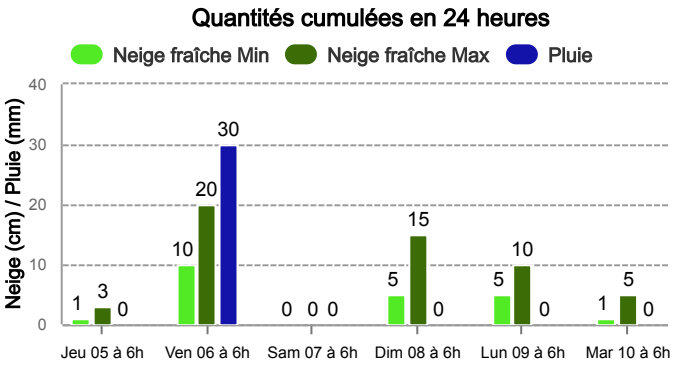

Tendance du mardi 10 février

3

Indice de risque marqué

Pas d'évolution notable en termes de risque.

Pour consulter la vigilance en cours, veuillez vous rendre sur le site https://vigilance.meteofrance.fr/fr

Météo-France - 73 avenue de Paris, 94165 Saint-Mandé cedex - Contact : contact@meteo.fr

Rédigé par Météo-France avec la contribution des observateurs du réseau nivo-météorologiques. Partenariat : ANMSM (Maires de Stations de Montagne), DSF (Domaines Skiables de France), ADSP (Directeurs de Pistes et de la Sécurité des Stations de Sports d'Hiver) et autres acteurs de la montagne.

Bulletin neige & avalanches par téléphone au **0 892 68 10 20** Service 0,35 € / min + prix appel

Bulletin d'estimation du risque d'avalanche

(valable en dehors des pistes balisées et ouvertes)

MASSIF : Renoso Incudine

Rédigé le dimanche 8 février 2026 à 16h

Conditions nivo-météo des 7 derniers jours

	lun. 02/02				mar. 03/02				mer. 04/02				jeu. 05/02				ven. 06/02				sam. 07/02				dim. 08/02			
	03h	09h	15h	21h	03h	09h	15h	21h	03h	09h	15h	21h	03h	09h	15h	21h	03h	09h	15h	21h	03h	09h	15h	21h	03h	09h	15h	21h
Météo																												
Vent (km/h)	40	25	25	30	55	45	10	20	15	60	40	20	30	60	45	70	85	70	60	45	55	55	45	50	50	30	30	10
à 2000m																												
Vent (km/h)	40	20	20	25	35	35	10	15	20	50	30	10	25	40	35	55	95	80	75	60	60	45	65	50	60	30	30	15
à 1500m																												

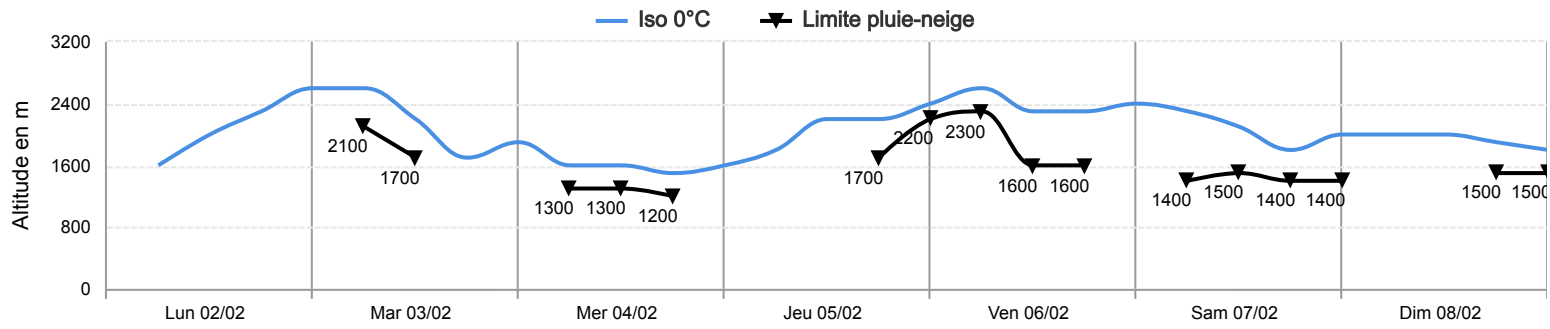

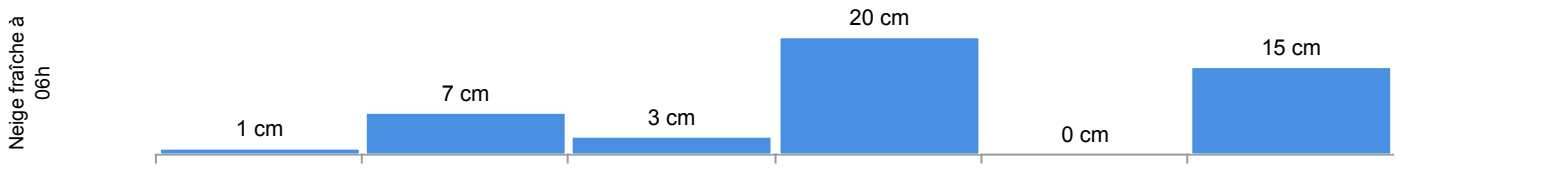

Risque d'avalanche	lun. 02/02	mar. 03/02	mer. 04/02	jeu. 05/02	ven. 06/02	sam. 07/02	dim. 08/02
	3	3	3	3	3	3	3

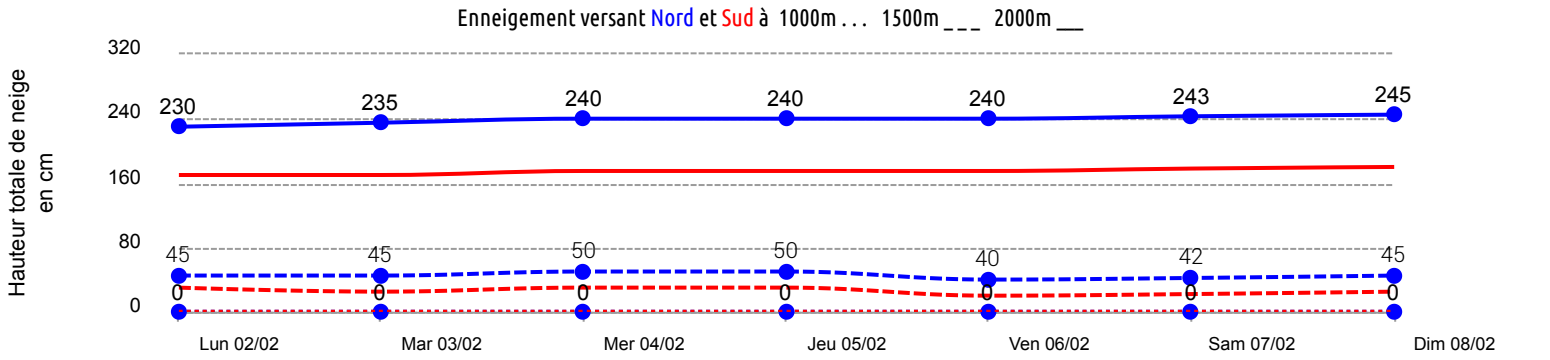

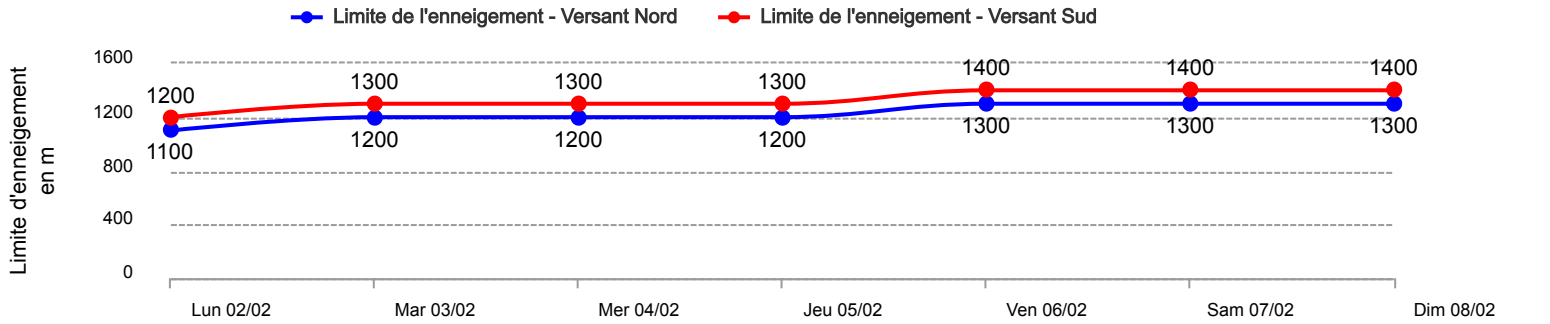

Pour consulter la vigilance en cours, veuillez vous rendre sur le site https://vigilance.meteofrance.fr/fr

Météo-France - 73 avenue de Paris, 94165 Saint-Mandé cedex - Contact : contact@meteo.fr

Rédigé par Météo-France avec la contribution des observateurs du réseau nivo-météorologiques. Partenariat : ANMSM (Maires de Stations de Montagne), DSF (Domaines Skiables de France), ADSP (Directeurs de Pistes et de la Sécurité des Stations de Sports d'Hiver) et autres acteurs de la montagne.

Bulletin neige & avalanches par téléphone au

0 892 68 10 20 Service 0,35 € / min + prix appel