Bulletin d'estimation du risque d'avalanche

(valable en dehors des pistes balisées et ouvertes)

MASSIF : Vanoise

Rédigé le dimanche 8 février 2026 à 16h

Estimation des risques pour le : LUNDI 09 FÉVRIER

QUELQUES PLAQUES D'ASPECT POUDREUX. RARES GRANDES AVALANCHES POSSIBLES.

3

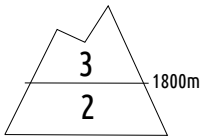

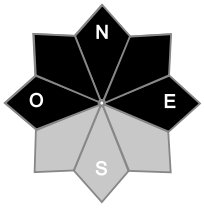

Au-dessus de 1800m indice de risque marqué, plus bas indice limité.

Départs spontanés : Peu probable

Déclenchements provoqués : quelques plaques poudreuses. Rares grandes avalanches possibles.

Indices de risque : 5 très fort - 4 fort - 3 marqué - 2 limité - 1 faible -- En noir : les pentes les plus dangereuses

Stabilité du manteau neigeux

Situation avalancheuse typique : neige ventée couche fragile persistante

Déclenchements provoqués : quelques **plaques friables d'aspect poudreux** sont encore en place près des crêtes. De rares nouvelles se forment ce dimanche là où le vent de Sud transporte la neige récente. Elles restent réactives ce lundi dans les versants Est, Nord et Ouest. Elles occasionnent des cassures de ~20/40 cm et des avalanches de taille 1 à 2 (petite à moyenne). **Observables :** accumulation de neige fraiche supérieure à la moyenne environnante, transport de neige par le vent.
Facteur aggravant, au dessus de 1800m et en versants froids (Est/Nord/Ouest) mais **aussi en Sud à haute altitude, des couches fragiles persistantes sont enfouies** dans le manteau, elles pourront réagir au passage d'un skieur ou en cascade après un départ de plaques friables en surface. Elles **engendrent de plus grandes et larges avalanches : taille 3 possible.**
Observables : woumfs en ce qui concerne les couches fragiles persistantes enfouies.

Départs spontanés : Peu probable

Qualité de la neige

Enneigement : un peu en dessous des normales de saison mais les chutes à venir (dans la semaine) devraient améliorer nettement l'enneigement au moins au dessus de 1800m

Limite skiable : les versants froids voyant pas ou peu le soleil ont gardé de la neige à basse altitude, skiable sur l'herbe ou sur pistes forestières dès 800 à 1000m. Sous bois skiables dès 1200m. Sur terrain rocheux, il vaut mieux atteindre 1300 m en Nord. En versant sud skiable dès 1300/1400m en prairies pas trop raides, 1600/1700m en Sud raide.

Qualité de la neige : en Est, Nord et Ouest, la neige est croutée jusqu'à 1500-1700 m. Plus haut, elle devient poudreuse (~20 cm), bonne à skier, jusqu'à l'approche des crêtes où elle est légèrement travaillée par le vent.
En Sud Est à Sud Ouest, elle est croutée le matin et ramollie doucement au fil des heures. Il faut monter au dessus de 2000m dans ces orientations pour trouver de la neige froide.

Aperçu météo pour le lundi 09 février

nuit	matin	après-midi	soir

Belle journée calme avant une séquence fortement perturbé les jours suivants

Pluie-Neige				
Iso 0 °C	1 700 m	1 800 m	2 000 m	1 700 m
Vent 2500 m	↖ 10 km/h	↗ 10 km/h	↗ 10 km/h	↑ 10 km/h
Vent 3500 m	← 25 km/h	↗ 15 km/h	↗ 20 km/h	↗ 25 km/h

Épaisseur de neige hors-piste

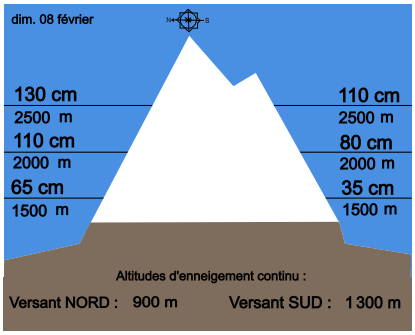

Précipitations à 1800 m

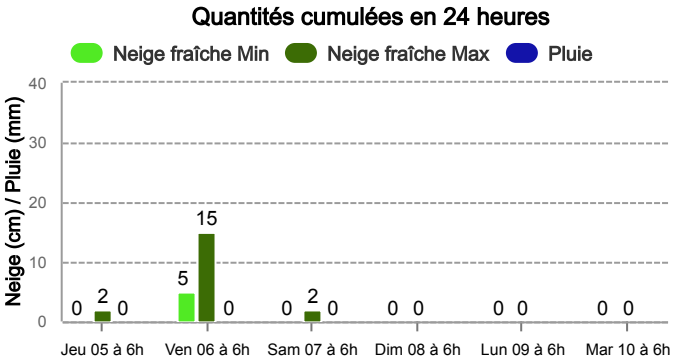

Tendance du mardi 10 février

3 **Indice de risque marqué**

Faible chute de neige en journée puis fortes pluies en soirée et nuit suivante avec une limite pluie neige temporairement vers 1000m en matinée puis rapidement 1500/1600m en journée puis 2000 voir un peu plus en soirée et nuit suivante. Le risque de départs spontanées sera en forte hausse dès qu'il va pleuvoir sur de la neige fraiche (plutôt en soirée donc)

Pour consulter la vigilance en cours, veuillez vous rendre sur le site https://vigilance.meteofrance.fr/fr

Météo-France - 73 avenue de Paris, 94165 Saint-Mandé cedex - Contact : contact@meteo.fr

Rédigé par Météo-France avec la contribution des observateurs du réseau nivo-météorologiques. Partenariat : ANMSM (Maires de Stations de Montagne), DSF (Domaines Skiables de France), ADSP (Directeurs de Pistes et de la Sécurité des Stations de Sports d'Hiver) et autres acteurs de la montagne.

Bulletin neige & avalanches par téléphone au 0 892 68 10 20 Service 0,35 € / min + prix appel

Bulletin d'estimation du risque d'avalanche

(valable en dehors des pistes balisées et ouvertes)

MASSIF : Vanoise

Rédigé le dimanche 8 février 2026 à 16h

Conditions nivo-météo des 7 derniers jours

	lun. 02/02				mar. 03/02				mer. 04/02				jeu. 05/02				ven. 06/02				sam. 07/02				dim. 08/02			
	03h	09h	15h	21h	03h	09h	15h	21h	03h	09h	15h	21h	03h	09h	15h	21h	03h	09h	15h	21h	03h	09h	15h	21h	03h	09h	15h	21h
Météo																												
Vent (km/h)	35	35	55	80	90	75	50	35	40	30	30	20	35	45	65	70	55	45	35	25	15	15	15	15	20	30	30	25
à 3500m																												
Vent (km/h)	15	25	40	65	80	60	35	25	25	20	20	10	10	25	55	60	45	30	25	15	10	5	5	5	10	20	20	15
à 2500m																												

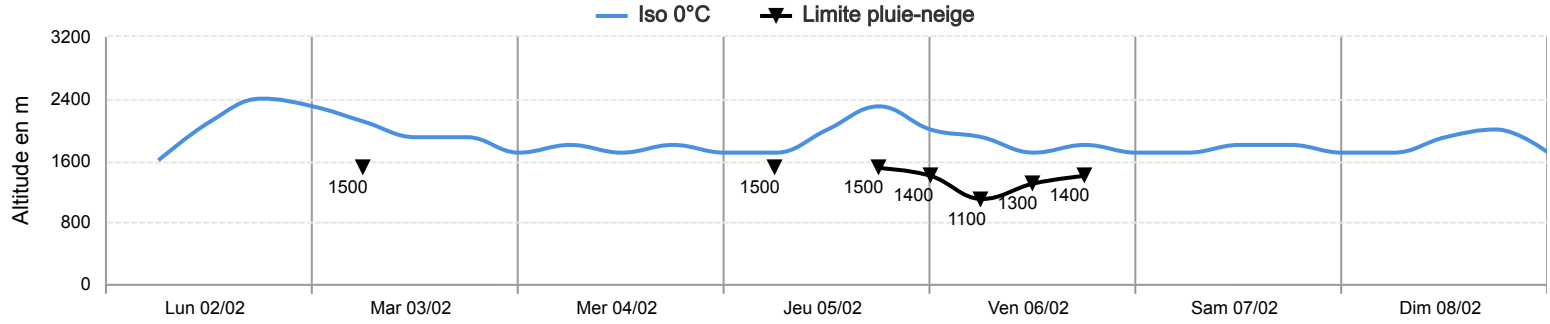

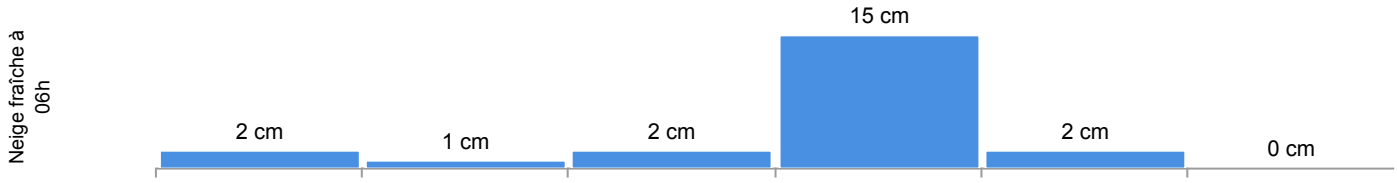

Risque d'avalanche	lun. 02/02	mar. 03/02	mer. 04/02	jeu. 05/02	ven. 06/02	sam. 07/02	dim. 08/02
	3	3	3	3	3	3	3

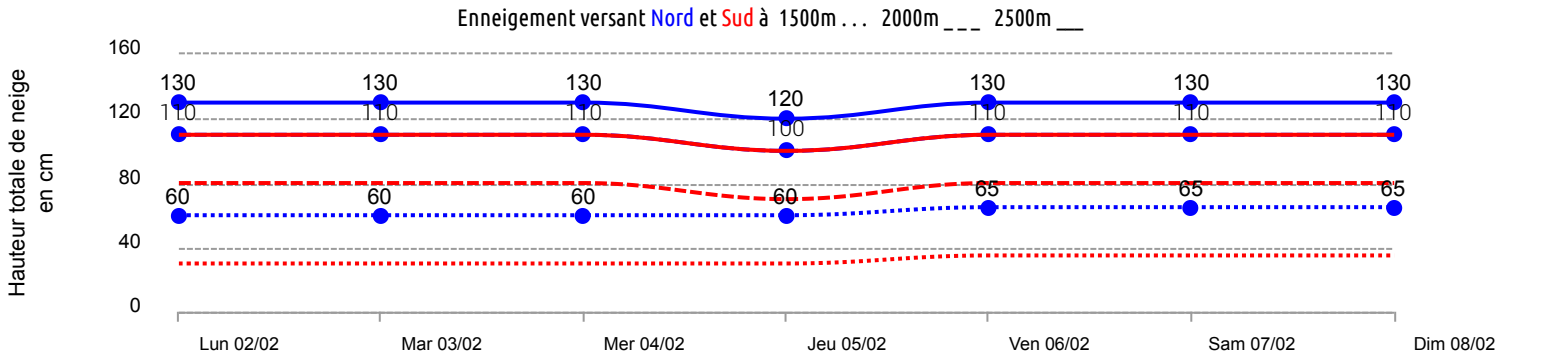

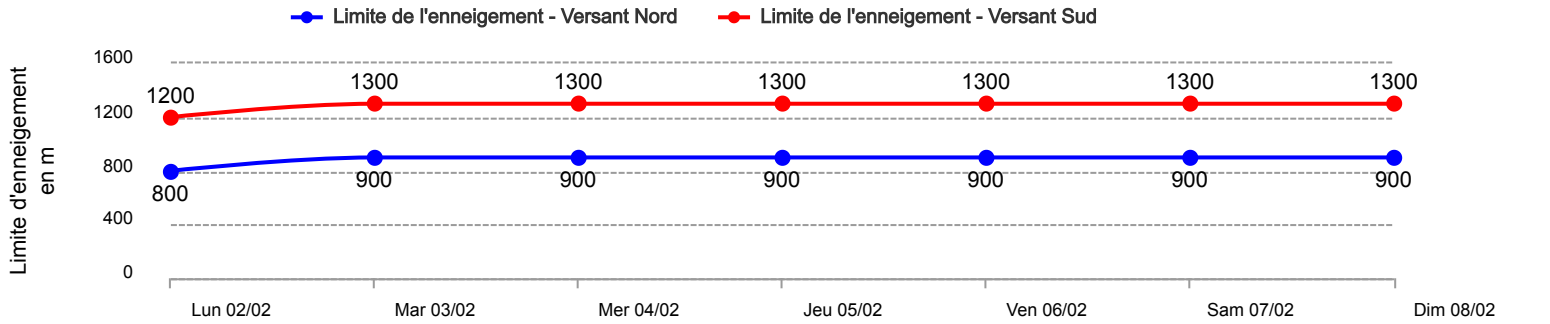

Pour consulter la vigilance en cours, veuillez vous rendre sur le site https://vigilance.meteofrance.fr/fr

Météo-France - 73 avenue de Paris, 94165 Saint-Mandé cedex - Contact : contact@meteo.fr

Rédigé par Météo-France avec la contribution des observateurs du réseau nivo-météorologiques. Partenariat : ANMSM (Maires de Stations de Montagne), DSF (Domaines Skiables de France), ADSP (Directeurs de Pistes et de la Sécurité des Stations de Sports d'Hiver) et autres acteurs de la montagne.

Bulletin neige & avalanches par téléphone au

0 892 68 10 20 Service 0,35 € / min + prix appel